GUÍA TURÍSTICA

SCZ

METRÓPOLI

Santa Cruz Metrópoli, tierra de contrastes fascinantes y exuberante belleza que invita a ser explorada por todos tus sentidos. Como Gobernador del Departamento de Santa Cruz, es un honor presentarte nuestra Guía Metropolitana de Turismo, una recopilación de los tesoros que nuestra Región Metropolitana tiene para ofrecerte.

Sumergíte en una experiencia única, donde la historia se funde con la modernidad y la naturaleza se viste de colores vibrantes para cautivar a todo aquel que la contempla. A menos de 2 horas de viaje desde el centro de la Metrópoli, descubrirás una gama diversa de atractivos que seducirán tu espíritu aventurero y tu sed de conocimiento.

Impresionantes atractivos naturales, monumentos históricos impregnados de cultura, modernos paisajes urbanos y una diversa oferta gastronómica. Santa Cruz Metrópoli te brinda un abanico de posibilidades, incluidas todas las experiencias cosmopolitas propias de cualquier gran metrópoli del mundo. Cada rincón, cada paisaje, está cuidadosamente seleccionado para garantizar una estancia inolvidable en cualquiera de sus municipios y área de influencia.

Arq. Mario Aguilera Cirbian

Gobernador del Departamento de Santa Cruz

¡Bienvenidos a Santa Cruz Metrópoli!
¡El epicentro Sudamericano!

Ni te imaginás

GUÍA TURÍSTICA
SANTA CRUZ METRÓPOLI

GOBIERNO AUTÓNOMO DEPARTAMENTAL DE SANTA CRUZ

Mario Aguilera Cirbian	**Gobernador del Departamento de Santa Cruz**
Ismael Medrano Suárez	**Coordinador y supervision Guía Turística**
Celina Miranda Vogt	**Diagramación, estilo y forma**

EQUIPO DE CONSULTORES

Roy Dávalos Terrazas	**Coordinador General del estudio**
Luís Eduardo Martínez Almanza	**Especialista en Planificación Urbana Metropolitana**
Ana Cinthia Menacho Ayala	**Especialista en Desarrollo Turístico**
Juan Miguel Vogtschmidt Rojas	**Especialista en Comunicación**
Mariela Saavedra Menacho	**Asesora en Patrimonio Arquitectónico y Cultural**

EDICIÓN E IMPRESIÓN

Renny Santiago Ramos Villarroel
Walter Américo Mamani Mamani

Gobierno Autónomo Departamental de Santa Cruz
Av. Omar Chávez, Esq. Pozo
Telf.(591-3) 3636000 – 3636001
https://sczmetropoli.santacruz.gob.bo/

ph: GAD SCZ

INSTRUCCIONES PARA LEER LA

GUÍA TURÍSTICA SANTA CRUZ METRÓPOLI

CONOCÉ LOS MUNICIPIOS

Distancia de Santa Cruz de la Sierra a:

1. La Guardia **17 Km**
2. Porongo **19 Km**
3. Cotoca **20 Km**
4. Warnes **27 Km**
5. El Torno **36 Km**
6. Colpa Bélgica **39 Km**
7. Montero **52 Km**
8. Pailón **53 Km**
9. Portachuelo **72 Km**
10. Okinawa I **86 Km**
11. Buena Vista **105 Km**

CATEGORÍAS DE TURISMO Y SU COLOR

Turismo arquitectónico, cultural, histórico y religioso | Turismo de naturaleza | Turismo de entretenimiento y recreación | Turismo de negocios | Turismo gastronónomico | Hotelería

HACÉ CLICK EN LOS SIGUIENTES ÍCONOS

Hacé click y conocé la ubicación

Hacé click y conocé sus redes sociales

**Para abrir los hipervínculos debe tener instalado Adobe Acrobat Reader o abrir con Lector PDF Google Drive*

10 MOTIVOS PARA VISITAR SANTA CRUZ METRÓPOLI

ph: GAD SCZ

ES LEY DEL CRUCEÑO LA HOSPITALIDAD

3 Millones de habitantes que tienen como cultura la buena atención al visitante, siendo popular la frase: “Es Ley del Cruceño la Hospitalidad”.

UNA METRÓPOLI PARA HACER NEGOCIOS

Más de 27.000 empresas establecidas, responsable del 24% del PIB de Bolivia

ALTA RIQUEZA NATURAL

A menos de 2 hrs en carretera están algunos de los sitios más biodiversos del mundo como el Parque Amboró. Además cuenta con una diversidad de paisajes desde lomas de arena, cascadas, lagunas, ríos, selvas, valles, llanuras y colinas.

SANTA CRUZ METRÓPOLI HUB DE FRANQUICIAS

Con más de 346 marcas concentrando el 60% de las franquicias en Bolivia.

UN LUGAR DE PRECIOS ACCESIBLES

El Índice de Precios al Consumidor es inferior al promedio latinoamericano (LATAM = 9.8% Vs. RMSCZ = 1.88%) y el Índice de Costo de Vida es 27% inferior en la RMSCZ, respecto al resto de Latinoamérica.

AMPLIA OFERTA HOTELERA

Con más de 260 establecimientos autorizados entre los cuales están las más importantes cadenas hoteleras del mundo así como acogedores hospedajes locales.

BENDECIDA CON UN CLIMA AGRADABLE

Caracterizado por un ambiente cálido, con un promedio de 29C° en primavera y verano, y 21C° en invierno. Su composición tropical – húmedo lo hace ideal para disfrutar de diversas actividades al aire libre."

SEDE DE UNA DE LAS FERIAS EXPOSICIÓN MÁS GRANDES DEL CONTINENTE

Más de 2000 expositores de 23 países, mueve más 100 Millones de dólares y recibe cerca de medio millón de visitantes.

SANTA CRUZ METRÓPOLI, UN LUGAR SEGURO

Una de las tasas de homicidios más bajos del continente.
- Latam 15.8 por cada 100.000 habitantes
- RMSCZ 2.65 por cada 100,000 habitantes

Una de las tasas de inseguridad (robos, hurtos, estafas, etc.) más bajos del continente.
- Latam 2.244 por cada 100,000 habitantes
- RMSCZ 267 por cada 100.000 habitantes

GASTRONOMÍA EXQUISITA

Con gran variedad de platos típicos. Se sirve con calidez. Además, se tiene la presencia de toda la gastronomía boliviana y se puede encontrar todo tipo de Cocina Internacional.

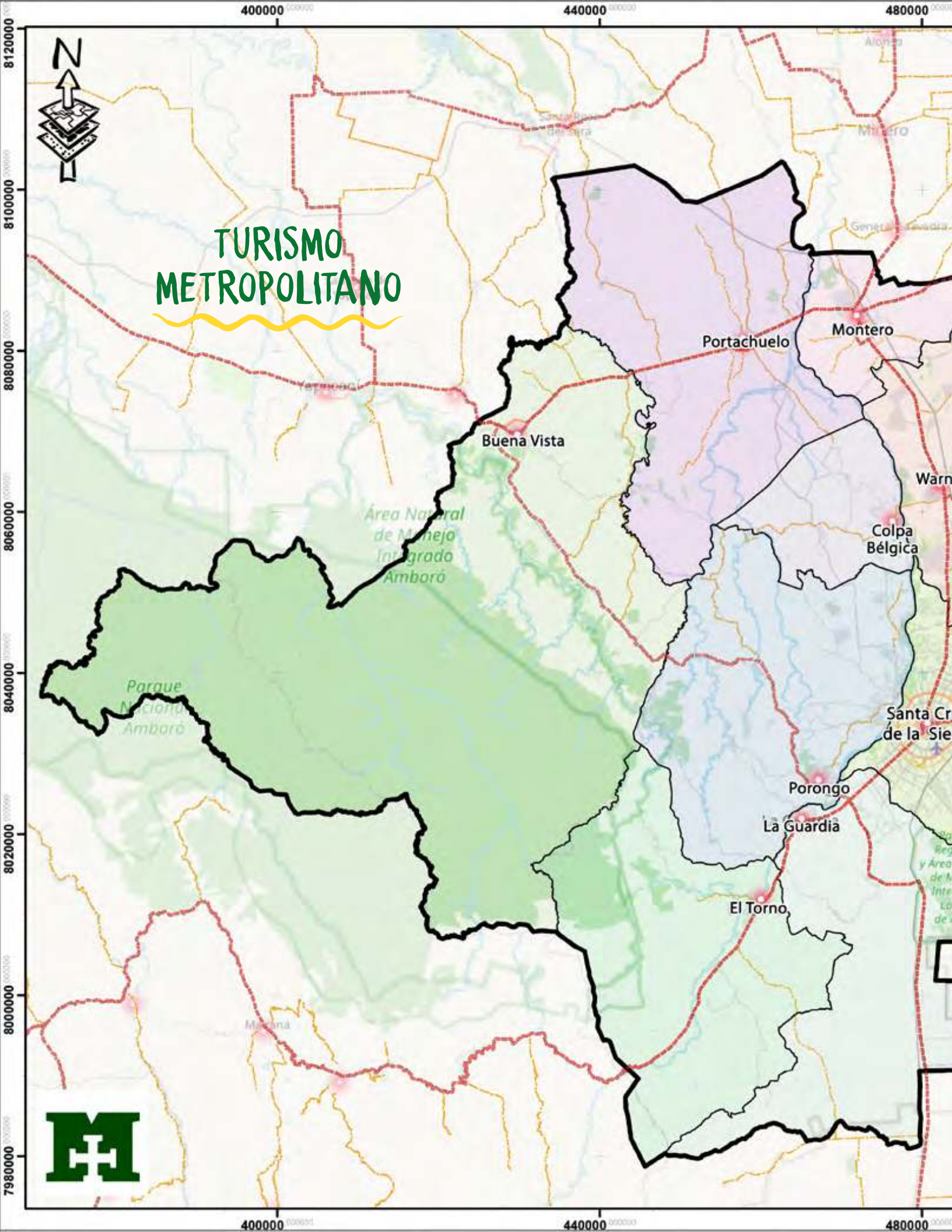
TURISMO
METROPOLITANO
N
400000
440000
480000
8120000
8100000
8080000
8060000
8040000
8020000
8000000
7980000
Portachuelo
Montero
Buena Vista
Área Natural
de Manejo
Integrado
Amboró
Parque
Nacional
Amboró
Colpa
Bélgica
Santa Cr
de la Sie
Porongo
La Guardia
El Torno

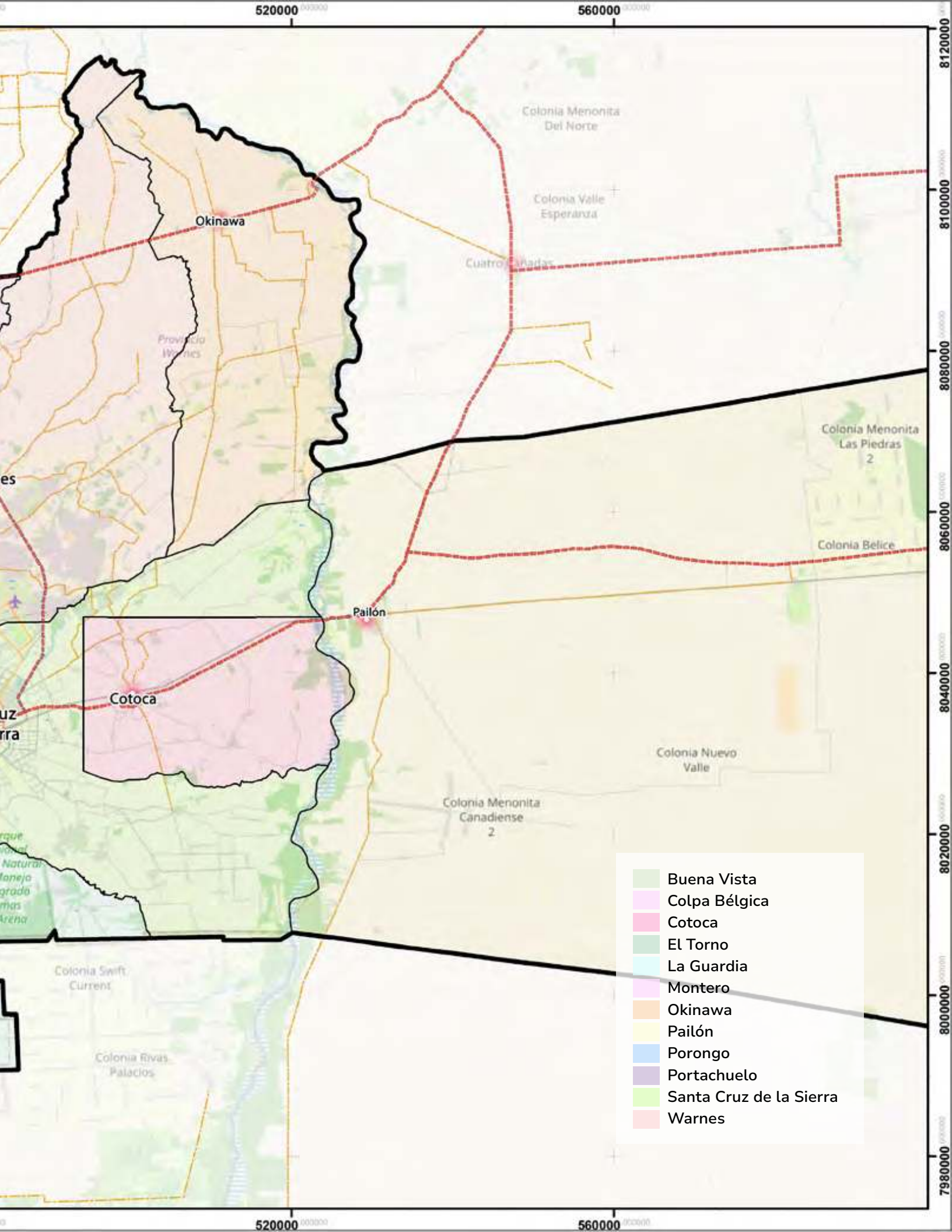
520000
560000
8120000
8100000
8080000
8060000
8040000
8020000
8000000
7980000
Colonia Menonita Del Norte
Colonia Valle Esperanza
Okinawa
Colonia Menonita Las Piedras 2
Colonia Belice
Pailón
Cotoca
Colonia Nuevo Valle
Colonia Menonita Canadiense 2
Colonia Swift Current
Colonia Rivas Palacios
Buena Vista
Colpa Bélgica
Cotoca
El Torno
La Guardia
Montero
Okinawa
Pailón
Porongo
Portachuelo
Santa Cruz de la Sierra
Warnes

SANTA CRUZ DE LA SIERRA

ph: GAD SCZ

SANTA CRUZ DE LA SIERRA

Provincia: Andrés Ibañez
Fundación: 26 de febrero de 1561

DATOS GENERALES

Otros Nombres:
"La Capital del Oriente Boliviano"
"La Ciudad de los Anillos"

Lema:
"Es ley del cruceño la hospitalidad"
"Siempre libres cruceños seamos"

DATOS DEMOGRÁFICOS

Gentilicio: Cruceño (a)
Población (2023)[1]: 2.251.627 habitantes, con una tasa de crecimiento anual del 4,99% del 2012 al 2023.
Densidad (2023): 6.915 hab. /km²

CLIMA

Clima tropical húmedo-seco, caracterizado por veranos muy cálidos y húmedos, e inviernos secos con temperaturas tibias a templadas.

Las temperaturas promedio oscilan entre los 29 °C y 32 °C en primavera y verano, aunque en verano se han registrado máximas que superan los 40 °C.

Durante el invierno, se producen incursiones de aire frío provenientes de latitudes más australes, conocidos como surazos, que pueden llevar las temperaturas por debajo de los 15 °C.

DATOS GEOGRÁFICOS

Situada en el margen derecho del río Piraí, que fluye hacia el norte hasta desembocar en el río Grande o Guapay, formando parte de la cuenca amazónica. La ciudad se encuentra en una divisoria de aguas: al oeste, las corrientes drenan hacia el río Piraí, mientras que al este, lo hacen hacia el río Grande. Su topografía es predominantemente plana.

Coordenadas: 17°48'02"S 63°10'41"O.

Superficie: 325.6 km²

Altitud: 416 m.s.n.m.

ECONOMÍA

Economía[2]: Las actividades económicas más importantes son la manufactura y turismo, que de acuerdo al Valor Bruto de Producción (VBP) del municipio representan el 95,26% y 4,27% respectivamente.

Es importante mencionar que la actividad agrícola no es representativa en la economía del municipio, a diferencia del departamento donde la actividad agrícola es uno de los mayores aportes al PIB departamental.

Valor Bruto de Producción (VBP): 49.639 MM Bs.
PIB per cápita[3]: 5.849 $us/habitantes

---

[1] Encuesta de Estimación Poblacional de Santa Cruz 2023. Instituto Cruceño de Estadística
[2] Mapa de Complejidades, BDP 2019
[3] PTDI G.A.M.S.C.S, con datos del índice de prosperidad de ciudades, estimaciones de ONU-Hábitat Bolivia, en base a INE 2012

SANTA CRUZ DE LA SIERRA

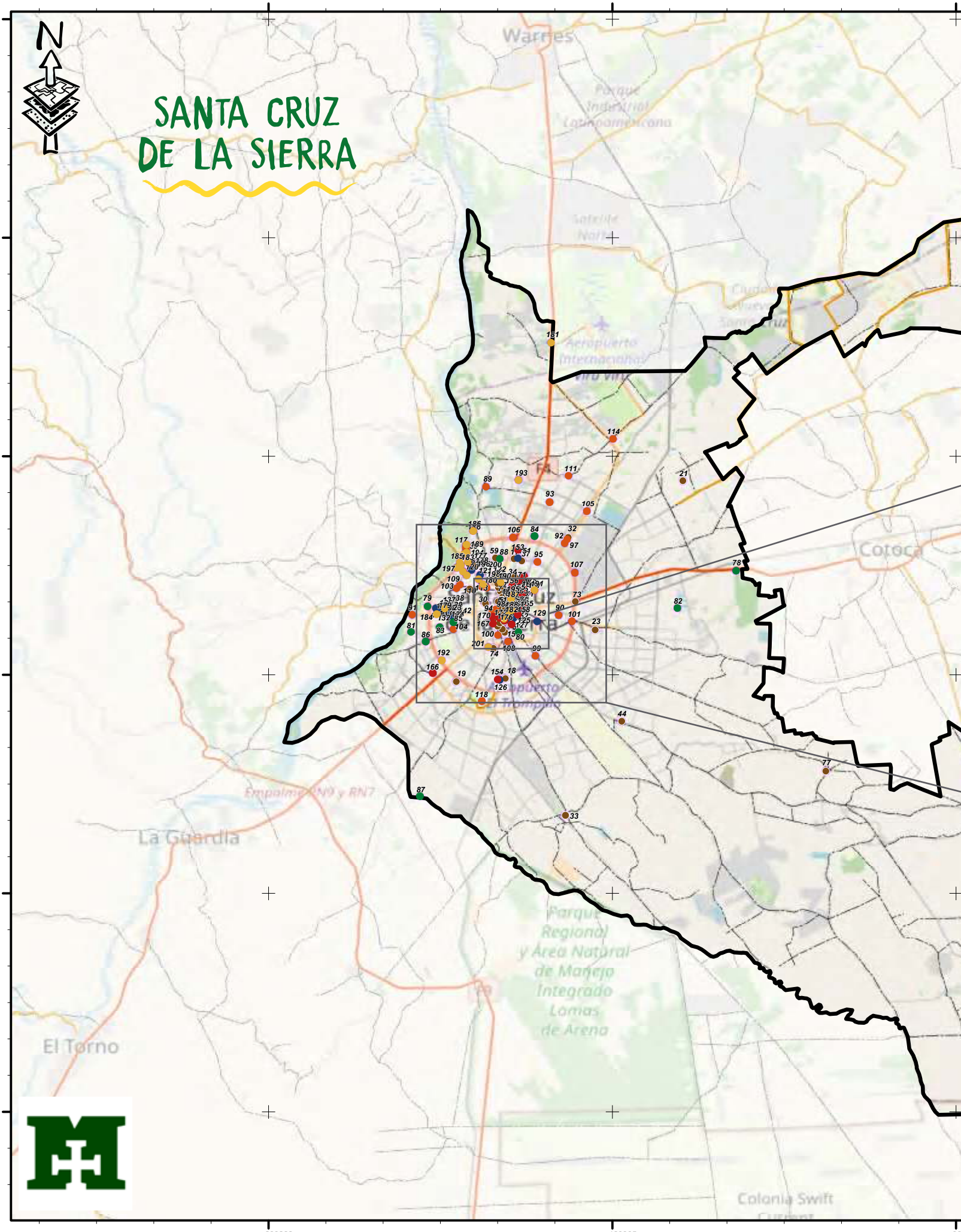

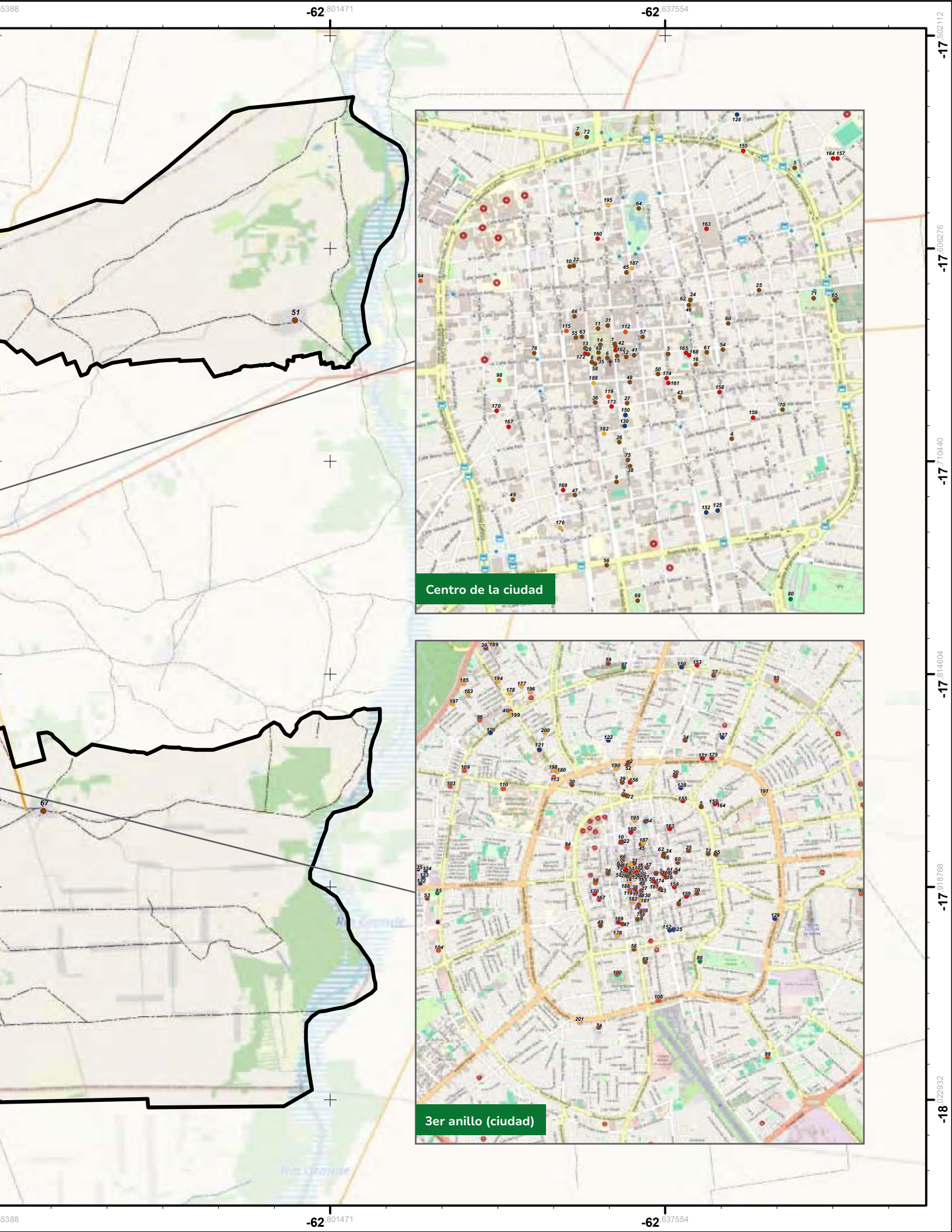
Centro de la ciudad
3er anillo (ciudad)

Turismo arquitectónico, cultural, histórico y religioso

1. Alianza Francesa
2. Altar Papal
3. Altillo Vaca Diez
4. Asociación Nueva Acropolis
5. Avión Pirata
6. Basílica Menor de San Lorenzo Mártir / Catedral Metropolitana de Santa Cruz de la Sierra
7. Biblioteca Municipal Enrique Kempff Mercado
8. Brigada Parlamentaria de Santa Cruz
9. Capilla Los Huérfanos
10. Carrera de Arte de la UAGRM
11. Casa de Gobierno
12. Casa Melchor Pinto
13. Casa Municipal de Cultura Raúl Otero Reiche
14. Casco Viejo (Centro Histórico de la ciudad)
15. Casona "Casa Cero" (Heladería)
16. Centro Boliviano Americano (CBA)
17. Centro Cultural Municipal Hamacas
18. Centro Cultural Guaracal La Morita
19. Centro Cultural Municipal La Cuchilla
20. Centro Cultural Ronald Roa
21. Centro Cultural San Antonio
22. Centro Cultural Seoane
23. Centro Cultural Villa Primero de Mayo
24. Centro de Arte Contemporaneo Kiosko
25. Centro de Formación de la Cooperación Española - AECID
26. Centro de la Cultura Plurinacional Santa Cruz
27. Centro Feliciana Rodriguez
28. Club Social 24 de septiembre
29. Comité Cívico Pro Santa Cruz
30. CRE
31. Edificio Central del Gobierno Autónomo Municipal de Santa Cruz de la Sierra
32. El Cambodromo
33. El Palmar - Distrito 13
34. Emergente Espacio de Arte
35. Espacio de Arte Manzana I
36. Fundación Simón I. Patiño
37. Galería de Arte 21 Santa Cruz
38. Galería de Arte Heberth Román
39. Galería de Arte Koqui Handal
40. Galería de Arte Los Tajibos
41. Galería de Arte y Café Abba Kadosh
42. Goethe - Zentrum Santa Cruz
43. Iglesia Jesús Nazareno
44. Iglesia Misional San Oscar Romero y Santa Mónica
45. Iglesia San Andrés
46. Iglesia San Francisco
47. Iglesia San Roque
48. La Federal
49. La Mansión, Centro Carismático Católico de Evangelización
50. Meraki Teatro Bar
51. Montero Hoyos - Distrito 15
52. Monumento Cristo Redentor
53. Museo Arte Originario y Popular de las Tierras Bajas, Artecampo
54. Museo de Arte Contemporáneo (MAC)
55. Museo de Historia - Uagrm
56. Museo de Historia Natural Noel Kempff Mercado
57. Museo de la Ciudad Altillo Beni (MAB)
58. Museo de la Independencia
59. Museo Guaraní Isoseño
60. Museo Historico Militar Heroes de La Guerra del Chaco
61. Museo Science Corner (CBA)
62. Nube Gallery
63. Paraninfo Universitario "Dr. Humberto Parada Caro"
64. Parque El Arenal
65. Paseo de Notables
66. Paseo La Recova
67. Paurito - Distrito 14
68. Plaza de Armas 24 de Septiembre
69. Plazuela Blacutt
70. Plazuela Calleja
71. Plazuela del Cementerio "Ñuflo de Chávez"
72. Plazuela del Estudiante
73. Romeria Cotoca
74. SAGUAPAC
75. Teatro Rene Moreno
76. Templo Nuestra Señora de la Merced
77. Tipoy - Distrito 14

Turismo de Naturaleza

78. Jardín Botánico Municipal de Santa Cruz de la Sierra
79. Parque Urbano 4 de Mayo (Autonómico)
80. Parque Urbano Central
81. Parque Urbano de Preservación Ecológica Curichi La Madre
82. Parque Urbano Laguna Guapilo
83. Parque Urbano Los Mangales I
84. Parque Urbano Los Mangales II
85. Parque Urbano Los Mangales III (scouts)
86. Parque Urbano Los Mangales Piraí
87. Reserva Natural las Garzas
88. Zoológico Municipal de Fauna Sudamericana Noel Kempff Mercado de Santa Cruz de la Sierra (bioparque)

Turismo de entretenimiento y recreación

89. Arena 26
90. Avenida Brasil
91. Cabañas del Rio Piraí
92. Carnaval Cruceño
93. Casa grande
94. Centro Comercial Cañoto
95. Centro Comercial Norte
96. Chaplin Show
97. CODASUR - Eventos Automovilistico
98. Coliseo Gilberto Parada (Calle Ingavi)
99. Estadio "Real Santa Cruz"
100. Estadio Ramón Tahuichi Aguilera
101. Feria de Barrio Lindo
102. Hard Rock
103. IC-NORTE
104. Indana
105. Las Alasitas
106. Las Brisas
107. Makro Parque Arena
108. Mega Center (Cine Center)
109. Patio Design
110. Polideportivo U.A.G.R.M.
111. Sede de Blooming
112. Shopping Boliviar
113. Show de Mier
114. Sonilum Arena (Av. G77)
115. Tiendas del Casco Viejo cruceño
116. Ventura Arena
117. Ventura Mall
118. Villa Olimpica
119. Bunkasai (Feria Cultural)

Turismo de negocios

120 AEDEP Asociación de Empresas para el Desarrollo
121 Av. San Martín (Equipetrol)
122 CAMEBOL - Cámara de Mujeres Empresarias de Bolivia
123 Cámara Agropecuaria del Oriente - CAO
124 Cámara de Exportadores, Logística y Promoción de Inversiones de Santa Cruz - CADEX
125 Cámara de Industria, Comercio, Servicio y Turismo de Santa Cruz - CAINCO
126 Cámara de la Construcción de Santa Cruz - CADECOCRUZ
127 Cámara Departamental de la Pequeña Industria y Artesanía - CADEPIA SANTA CRUZ
128 Cámara Gastronómica de Santa Cruz - CADEG
129 Cámara Hotelera Departamental de Santa Cruz - CADEHCRUZ
130 Federación de Empresarios Privados de Santa Cruz - FEPSC
131 Feria Agropecuaria Internacional de Santa Cruz
132 Fexpocruz
133 Fexpocruz - Centro de Convenciones
134 Fexpocruz - Expoleche
135 Fexpocruz - Expoteleinfo
136 Fexpocruz - Feria Automotriz de Santa Cruz
137 Fexpocruz - Feria de Accesorios y Actividades de Mascotas. EXPOPET
138 Fexpocruz - Feria de Inversiones Inmobiliarias. EXPO REAL ESTATE
139 Fexpocruz - Feria de la Construcción, Arquitectura y Diseño
140 Fexpocruz - Feria de la Industria del Café. Specialty Coffee Expo Bolivia
141 Fexpocruz - Feria de Servicios Financieros
142 Fexpocruz - Feria Integral del Bosque de Bolivia ExpoForest
143 Fexpocruz - Feria Internacional de Cómics
144 Fexpocruz - Feria Internacional de Estética y Peluquería Profesional (COSMOBEAUTY BOLIVIA)
145 Fexpocruz - Feria Internacional de Productos Gráficos - EXPOGRÁFICA BOLIVIA
146 Fexpocruz - Feria Internacional del Libro de Santa Cruz
147 Fexpocruz - Feria Nacional de Material Textil. BOLIVIA TEXTIL
148 Fexpocruz - Festival Internacional de Vinos y Quesos
149 Fexpocruz - XTREME FEXPO RACE
150 Juventud Empresa - Asociación de Jovenes Empresarios y Profesionales de Santa Cruz
151 Parque Industrial
152 Rueda de Negocios

Turismo Gastronómico

153 Av. Beni y Alemania, opciones de restaurantes
154 Av. Santos Dumont, opciones de restaurantes
155 Av. Uruguay del primer anillo, opción de churrasquería y restaurantes
156 Cafés y Heladerías Av. Monseñor Rivero
157 Comida Típica Suarez S.R.L.
158 El Aljibe Del Sabor
159 El Orquidiario Café (Centro)
160 Hamburguesas Rics
161 Industrias Alimenticias Cabrera (Heladería Cabrera)
162 La Pascana
163 Las tradicionales negritas
164 Los Agachaus del Avión Pirata
165 Mario Higado
166 Mercado “Los Bosques” y su oferta gastronómica de pescados
167 Mercado 7 calles y su oferta gastronomica
168 Mercado Nuevo
169 Pollo Chuy, atrás de la Iglesia San Roque como la primera sucursal
170 Restaurant La Barca
171 Restaurante “La Casa del Camba”
172 Restaurante del Club 24 de Septiembre
173 Snack La Le Li Lu
174 Tapekua
175 Tobby

Hotelería

176 Alvaro Gutierrez Galvez Comercialemente Llamado House Inn Apart Hotel
177 Apart Hotel Los Delfines S.R.L. Comercialmente Llamado Delfines Collection Hotel
178 Apart Hotel y Sala de Eventos Taos
179 Buganvillas Hotel Condominio S.R.L.
180 Complejo Hotelero Yotau S.A.
181 Coorporación Hotelera Teka S.A Denominado Hotel Sun
182 Cosmopolitano S.R.L.
183 Empresa de Servicios Chairú S.R.L. Denominado Hotel Chairú
184 Empresa Hotelera Balhoteli S.A. Denominado Novotel
185 Empresa Hotelera Icon S.A. Comercialmente llamado Marriott
186 Empresa Hotelera Meridianam S.A. Denominado Swissotel Santa Cruz de la Sierra
187 Hotel Arenal S.R.L.
188 Hotel Boutique Kusinitaña Misional S.R.L. denominado Hotel Boutique Kusinitaña Misional
189 Hotel Camino Real
190 Hotel Cortez LTDA.
191 Hotel Osho
192 Inhot S.R.L. Comercialmente Llamado Hotel Boutique D´Castillla
193 Inverhotel S.A. Apart Hotel Comercialmente Llamado Terranova Suites
194 Mercantile Investment Corporation Bolivia S.A. Merinco S.A. Con el Nombre Comercial Hampton By Hilton
195 Palacios S.R.L. Denominado Comercialmente Como Hotel Plaza 24
196 Paulistania Casablanca Hotel
197 Rosmery Handal ABS Comercialmente Llamado Mai Suites Apart Hotel
198 Sensescorp S.R.L.
199 Sociedad Hotelera Los Tajibos S.A.
200 Sociedad Inmobiliaria La Julieta S.R.L Comercialmente Denominado Alfonsina Hotel Boutique By Inboccalupo
201 Torre Hotel Ejecutivo S.R.L.

TURISMO
ARQUITECTÓNICO, CULTURAL, HISTÓRICO Y RELIGIOSO

Santa Cruz de la Sierra

ph: GAD SCZ

CASCO VIEJO

CENTRO HISTÓRICO DE SANTA CRUZ DE LA SIERRA

Ubicación: Perímetro contemplado dentro del primer anillo, desde el kilómetro cero hasta llegar a sus cuatro puntos cardinales finales que son: Norte Av. Cañoto, Sur Av. Irala Este Av. Argomosa Oeste Av. Cañoto.

ph: GAD SCZ

No dejés de visitar el "Casco Viejo" de Santa Cruz, si querés conocer uno de los lugares más emblemáticos de la ciudad, que encarna y conserva parte de la historia viva cruceña a través de sus monumentos, calles, galerías, horcones, ventanas, antiguos caserones con sus respectivos aljibes y altillos que hacen de esta zona un lugar arquitectónico único. Caminar por el Casco Viejo, también conocido como Centro Histórico, te llevará a recorrer su Plaza principal 24 de Septiembre, el corazón de la vida social y cultural de la ciudad y que a su vez está rodeada de obras que son un patrimonio para el departamento. Entre los puntos imperdibles se encuentran el Museo de Historia y Archivo Regional, que alberga valiosos documentos y piezas que narran la rica historia de la región. También, el Museo de la Ciudad "Altillo Beni", donde la historia local cobra vida a través de exhibiciones cautivadoras. En la esquina de las calles Ayacucho e Independencia, está un edificio construido en 1917 y donde hoy funciona el histórico Club Social 24 de Septiembre. Justo al lado se encuentra el ex Cine Palace, originalmente llamado Cine Roma, que fue la primera sala de cine en Santa Cruz.

ph: La Pascana

Luego, en la esquina de las calles Junín y Libertad, se eleva el edificio central de la "Universidad Autónoma Gabriel René Moreno", construido en el año 1940 por Rómulo Herrera Justiniano. En medio de este centro histórico resalta la estatua de Ignacio Warnes, que, por ser héroe de la independencia, ocupa el podio céntrico de este espacio de alta concurrencia. En el sudoeste de la plaza se alza de manera imponente la "Basílica Menor de San Lorenzo", construida en el año 1770, misma que tiene una vigencia de casi tres siglos. Al admirar esta edificación religiosa a detalle, lo primero que se observa son dos torres y en una de ellas existe un mirador desde el cual se puede observar la ciudad panorámicamente. En la acera sur se distingue una edificación construida por Simone Marchetti, entre los años 1871 y 1878, donde actualmente funciona la "Brigada Parlamentaria". En la acera norte esta la casa de gobierno de la Gobernación y a su lado las oficinas centrales de la Alcaldía Municipal. Esta obra empezó a construirse en el año 1901 y fue diseñada por el arquitecto Bernardo Cadario. Si estás en busca de una oferta cultural, no te podés perder las fascinantes joyas que Santa Cruz tiene para ofrecer. El "Museo de Arte Contemporáneo" y el "Espacio de Arte Manzana 1" son paradas obligatorias que te brindarán una perspectiva única de la creatividad local. Sumergite en la riqueza cultural visitando el "Centro Cultural Casa Melchor Pinto", el "Centro Simón Patiño en Santa Cruz" y la "Casa Municipal de Cultura Raúl Otero Reiche", todos ellos, centros vibrantes que resaltan la diversidad y vitalidad cultural de la ciudad. Por otro lado, si deseás explorar las artesanías locales, no podés perderte el encanto del "Paseo Artesanal La Recova" y dar un paseo por el Parque "El Arenal". En definitiva, el Centro Histórico de Santa Cruz es un auténtico museo al aire libre donde cada edificio, estructura y casona representa los diversos procesos históricos y culturales vividos por la ciudad y sus habitantes a lo largo de los años. No dejés pasar la oportunidad de sumergirte en la riqueza cultural e histórica que estos lugares atemporales ofrecen a los visitantes de Santa Cruz.

ph: GAD SCZ

ph: GAD SCZ

PLAZA

24 DE SEPTIEMBRE

Ubicación: Calle 24 de Septiembre, centro de la ciudad

ph: GAD SCZ

Si querés conocer y explorar Santa Cruz, la "Plaza 24 de Septiembre" es el punto de origen y partida de la ciudad. Aquí Don Lorenzo Suárez de Figueroa y Don Gonzalo Soliz de Holguín culminaron el traslado de la ciudad "San Lorenzo de la Frontera" (Cotoca) a orillas del río Piraí y la bautizaron con el nombre de la "Punta de San Bartolomé" hace ya más de 400 años, en 1590 y donde actualmente se alza la ciudad más pujante de Bolivia. En la actualidad, "La Plaza 24 de Septiembre" es un reflejo perfecto de la mezcla de historia y modernidad que caracteriza a Santa Cruz. Las primeras casas y calles de la Santa Cruz de antaño surgieron en torno a la plaza central. Se llama "Plaza 24 de Septiembre" en honor al grito emancipador del 1810 y se encuentra rodeada de edificaciones históricas importantes. Antiguamente, se la denominaba "Plaza Mayor", "Plaza Real" o "Plaza de Armas", siendo simplemente un campo verde. En 1621 toma el nombre de "Plaza de la Concordia" en honor a la unión de las ciudades de San Lorenzo el Real y Santa Cruz de la Sierra. A mediados del 1880 el francés Carlos de Charlot por encargo del gobierno, convierte este campo verde en un parque con jardines, enladrilla las cuatro aceras radiales, construye un murete periférico de ladrillo y una glorieta al centro, donde los fines de semana se podían escuchar las clásicas retretas musicales. El año 1910 el lugar toma el nombre definitivo de "Plaza 24 de Septiembre", se demuele el murete, los arcos de las esquinas y la glorieta en 1920 y en su lugar se instala la estatua del patriota Ignacio Warnes en 1922. En 1960 se modifica el diseño de los bancos, faroles, mosaicos y se plantan las primeras palmeras reales. En 2004 se realiza una importante renovación y remodelación, al cerrar dos calles integrándola de esta manera a la Catedral y al espacio conocido como Manzana Uno.

Plaza 24 de Septiembre

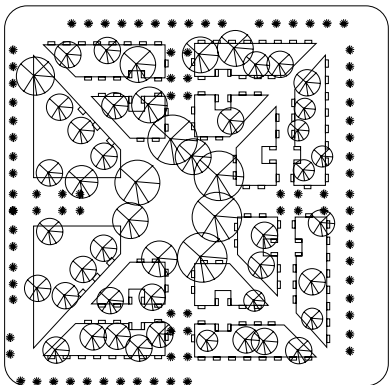

CLUB

24 DE SEPTIEMBRE

Ubicación: Plaza principal, esq. Calle Ayacucho

ph: GAD SCZ

¡Club 24 de septiembre, parte de la cuna de la cruceñidad! Si visitás el "Club 24 de Septiembre", te recibirán sus amplios, elegantes y acogedores salones que han sido testigos de importantes eventos sociales, culturales y cívicos de Santa Cruz. La construcción del edificio se remonta a la década del siglo XX, cuando el empresario José Lino Torrez compra el terreno para construir un palacete. Este edificio fue diseñado por el arquitecto argentino Abraham de Maturana, siendo inaugurado en 1917. Por su parte, el Club Social "24 de Septiembre" se funda en 1920 y compra la edificación el 21 de julio de 1941, durante la gestión de Osvaldo Gutiérrez, tomando posesión del preciado inmueble en 1949, para ocuparlo como su sede principal hasta la fecha; convirtiéndose así, en un referente para la región desde aquel entonces. Muchos cruceños destacados presidieron el Club Social como Rafael Soria Galvarro, el Dr. German Landívar y el Dr. Melchor Pinto Parada, entre otros. En este predio, se han dado las grandes reuniones cívicas y muchas de las luchas y reivindicaciones han nacido de los salones del Club 24 de Septiembre. Asimismo, se hacían las celebraciones de carnaval, la coronación de la reina y los famosos "bailes de máscaras". En su interior se encuentra una biblioteca, con una colección de libros que han sido donados en la década de los 50. Por su rol y decidido apoyo a las reivindicaciones cívicas, regionales y modernización del pueblo cruceño ha sido merecedor de varias distinciones como la "Medalla al Honor Cívico" en 1989 y el "Cóndor de los Andes" en 1990. El 07 de noviembre del 2017, es declarado como "Patrimonio Histórico" por el Consejo Municipal de Santa Cruz de la Sierra.

BRIGADA PARLAMENTARIA DE SANTA CRUZ

Ubicación: Plaza 24 de Septiembre, Esq. Independencia

ph: GAD SCZ

ph: GAD SCZ

En este antiguo terreno se encontraba el Cabildo Colonial y Casa de Gobierno a partir de 1825, donde se albergaba a los prefectos de turno que eran también comandantes de policía y funcionaban a la vez las dependencias de los Tribunales de Justicia. Fue demolido en 1860 y en 1871, el Gobierno autoriza al municipio reemplazarlo por otro de mayor envergadura, invitando al constructor italiano Simone Marchetti y el austriaco David Cronenbold para que se hagan cargo de la edificación. El nuevo edificio es la única obra publica de dos plantas, no religiosa, de estilo toscano que inauguró en 1892 con el nombre de "Palacio de Gobierno y Justicia". Actualmente funciona las oficinas de la Brigada Parlamentaria del Departamento de Santa Cruz en los dos pisos y en la planta baja, las dependencias del Museo de la Independencia y de la Galería de Arte Manzana Uno.

ph: GAD SCZ

PASEO
LA RECOVA

Ubicación: Calle Libertad a media cuadra de la Plaza 24 de Septiembre
Atención: Lunes a sábado de 09:00 a 19:00 horas

ph: GAD SCZ

Si querés llevarte recuerdos de tu estadía por Santa Cruz, tenés que ir al Paseo Artesanal "La Recova". Ubicado a media cuadra de la Plaza 24 de Septiembre, cuenta con recuerdos (souvenirs) típicos del oriente boliviano y del país, como obras artesanales hechas en cuero, joyas, piedras preciosas como la "bolivianita" y la "cruceñita", bisutería hecha de semillas y tallados en madera, entre otros. Tiene un escenario donde podés disfrutar de presentaciones folclóricas y otras expresiones artísticas y culturales, mientras degustas un café con horneados típicos de Santa Cruz. Fue fundado el 18 de agosto de 1983, con el objetivo de reunir a los artesanos cruceños y posicionar sus trabajos artesanales. Sin duda, tenés que pasar por este paseo artesanal para llevarte grandes recuerdos de tu visita por la ciudad.

ph: GAD SCZ

ph: GAD SCZ

CASA MUNICIPAL DE LA CULTURA

"RAÚL OTERO REICHE"

Ubicación: Calle Libertad # 65, al frente de la Plaza 24 de Septiembre
Atención: Lunes a viernes: 08:00 a 12:00 y 15:00 a 21:00
Sábados y domingos: 16:00 a 21:00

ph: GAD SCZ

ph: GAD SCZ

Si sos un amante de la cultura y las artes, la "Casa Municipal de Cultura Raúl Otero Reiche" es un espacio que no podés dejar de visitar. Lugar emblemático y cultural de la ciudad de Santa Cruz de la Sierra, donde podrás admirar obras de artistas locales, nacionales e internacionales, presentaciones de libros, conferencias, seminarios, danzas, obras de teatro que te harán reír, llorar y reflexionar. Representa el bastión del desarrollo cultural cruceño, siendo el primer espacio cultural que tuvo la ciudad de Santa Cruz de la Sierra. Está ubicado frente a la plaza principal, corazón de la ciudad, en un edificio catalogado Patrimonial, lo que le otorga características singulares, ya que fue construida en 1905, por lo que la historia resonará en cada rincón, siendo testigo de innumerables acontecimientos que han dado forma al desarrollo cultural de nuestra ciudad. Desde entonces, se ha convertido en un centro cultural dinámico donde artísticas y amantes se encuentran para celebrar la creatividad y la pasión. Desde sus inicios ha difundido la cultura local y regional, está orientada al fomento de expresiones y prácticas artísticas-culturales, en la búsqueda del fortalecimiento de la creatividad y las identidades. Fundada el 1 de abril de 1968 como una institución para la actividad cultural impulsada por un comité organizador y apoyada por la Alcaldía Municipal de la época. Se la denominó como "Casa de la Cultura Raúl Otero Reiche" en homenaje al poeta cruceño.

ph: GAD SCZ

MANZANA 1

ESPACIO DE ARTE

Ubicación: Calle Independencia, entre Ayacucho e Ingavi, Manzana Uno
Atención: Lunes a domingo: 10:00 a 13:00 y 15:00 a 20:00

ph: GAD SCZ

¿Buscás sumergirte en el fascinante mundo del arte en la metrópolis cruceña?

Bienvenido al "Espacio de Arte de Manzana 1", punto de encuentro para artistas emergentes y reconocidos; un destino obligado para los amantes del arte. En este espacio, te verás rodeado desde pinturas y esculturas hasta instalaciones de arte contemporáneo. Cada rincón está cuidadosamente pensado para ofrecerte una experiencia inolvidable.

Lo más interesante de este sitio es su enfoque en la diversidad y la innovación. Aquí encontrarás una fusión de diferentes estilos y corrientes artísticas, desde el realismo y el surrealismo hasta el arte abstracto y el minimalismo. No importa cuáles sean tus preferencias, aquí siempre encontrarás algo que te llame la atención y te haga reflexionar. Se encuentra ubicada en el centro histórico de Santa Cruz de la Sierra y se llama Manzana 1 porque está emplazada en la primera manzana de la ciudad.

CASA DE GOBIERNO

GOBIERNO AUTÓNOMO DEPARTAMENTAL DE SANTA CRUZ

Ubicación: Acera Norte de la Plaza Principal 24 de Septiembre

ph: GAD SCZ

La "Casa de Gobierno", patrimonio arquitectónico que refleja la identidad de los cruceños y ha sido escenario de muchos episodios que han marcado la historia de Santa Cruz. Este edificio, de estilo español fue construido en una Santa Cruz de Antaño de calles polvorientas, arquitectura simple e infraestructura urbana prácticamente inexistente, por el Arq. Bernardo Cadario entre los años 1901 y 1904. En aquel entonces era llamado el "Palacio Consistorial" y en él funcionaba la Alcaldía de la ciudad. Ha sido sede del Banco del Estado, Palacio Prefectural, Museo y Centro de Interpretación turística. El año 1994, el edificio fue completamente refaccionado y desde el 2006, con la elección del primer prefecto, se la establece como "Casa de Gobierno", sede del "Gobierno Autónomo Departamental de Santa Cruz". Dentro de sus instalaciones se encuentra una bóveda que fue acondicionada como un lugar que alberga la historia de los cabildos del siglo XXI.

EDIFICIO CENTRAL DE LA
ALCALDÍA

Municipal de Santa Cruz de la Sierra

Ubicación: Calle 24 de Septiembre #101
Atención: Lunes a viernes: 08:00 a 16:00

ph: GAD SCZ

El Edificio de la Alcaldía Municipal de Santa Cruz de la Sierra conserva la peculiaridad de la Santa Cruz de Antaño. Formó parte de las primeras edificaciones cuando nacían los primigenios cuadrantes del pueblo y desde entonces ha sido testigo de la transformación de la ciudad en la metrópolis que es hoy. Fue la sede entre los siglos XVII y XIX del Palacio Episcopal, siendo conocido el lugar como el "Altillo de los Obispos" por la frecuencia con que los parroquianos de la ciudad veían a los obispos disfrutar de las vistas y de las galerías de la antigua construcción. El edificio fue construido por el arquitecto Bernardo Cadario, entre 1901 y 1904. La Familia Zeller Mozer fue la propietaria de la casa hasta 1968, año en el que el alcalde My. Av. Hernán Castro Villazón adquirió la propiedad para el municipio cruceño. Fue restaurada y renovada entre 1985 y 1989 sin afectar las características iniciales de edificio elegante y señorial y se logra mantener su estilo monumental. Actualmente es patrimonio histórico de la ciudad.

ALTILLO
VACA DIEZ

Ubicación: Calle La Paz esquina Sucre
Atención: Lunes a viernes: 08:00 A 16:00

ph: GAD SCZ

¡Conoce una de las viviendas más antiguas de la época colonial cruceña!

Altillo Vaca Diez (Casa de Altos), data de finales del siglo XVIII y consta de dos plantas con doble galería, paredes de barro y guapá amarrados con güembé. En esta casa de altos, habitaron el Gobernador Francisco de Aguilera y José Toledo Pimentel en el Siglo XIX y posteriormente funcionó el Banco de la Nación Argentina; entidad a la que la familia Vaca Diez - Suárez Arana y Cronenbold, compra el inmueble en el año 1925. Esta original edificación sufrió una transformación, cuando el Concejo Municipal de 1916 lanza una Ordenanza Municipal, obligando a los vecinos la construcción del ochave en todas las esquinas y la apertura total de balcones. Se han hecho algunas remodelaciones al Altillo Vaca Diez, conservando todas las características del estilo colonial con el que fue construido.

PARANINFO

UNIVERSITARIO

Ubicación: Calle Junín, entre Libertad y 21 de Mayo
Atención: Lunes a viernes: 08:00 a 12:00 y 15:00 a 18:30

ph: Paraninfo Universitario

Si tu debilidad es una buena obra teatral o el gusto por la puesta en escena en teatro, sin duda el paraninfo universitario "Dr. Humberto Parada Caro" debe ser una de tus principales opciones. Se constituye en uno de los principales espacios donde se ejecuta la promoción y difusión cultural de actuación. Cuenta con un hermoso espacio que ha sido testigo de importantes eventos culturales y académicos; siendo sede de innumerables obras teatrales, conciertos, exposiciones, conferencias de renombre nacional e internacional, como apoyo a las actividades educativas y artísticas de nuestra ciudad. Inicio sus actividades en 1959 con el nombre de Gran Cine Grigotá, donde funcionaba el Teatro Experimental Universitario (T.E.U). El 13 de junio de 1984 reabre sus puertas como "Paraninfo Universitario" y el año 2022 el Ilustre Concejo Universitario lo denomina Paraninfo Universitario Dr. Humberto Parada Caro, esto en homenaje al hombre que aportó a los actores de la época y fue ganador de importantes premios locales e internacionales.

CENTRO CULTURAL

SIMÓN I. PATIÑO

Ubicación: Calle Independencia, esq. Suárez de Figueroa #89
Atención: Lunes a viernes: 08:30 a 12:00 y 15:00 a 19:00

ph: GAD SCZ

Exposiciones artísticas culturales, talleres, conferencias y propuestas lúdicas son las acciones educativas que propone el Centro Cultural Simón I. Patiño. Cuenta con una biblioteca especializada en temas de ecología y biología, constituyéndose como un refente de información especializada sobre estas temáticas. La Fundación Universitaria Simón I. Patiño fue fundada en 1931 por el mismo Simón I. Patiño y abrió sus puertas en la ciudad de Santa Cruz de la Sierra el 2004. Busca generar una educación de calidad a través del arte, la ciencia y la cultura. Asimismo, promueve el potencial humano y la conservación del patrimonio ambiental del país.

¿Buscás especializarte en el idioma francés y tener acceso a una biblioteca con más de 3.000 documentos, entre libros y revistas de literatura francesa, boliviana y de diversos países? Entonces, Alianza Francesa es el lugar. No solo organiza módulos del idioma francés, sino también actividades culturales como conciertos, conferencias y exposiciones. Entre sus principales actividades están la Semana Internacional del Idioma Francés, la Fiesta de la Música y el Festijazz.

Si estás en Santa Cruz y querés aprender el idioma alemán, Goethe Zentrum es una excelente opción. Organiza actividades pedagógicas y culturales con el objetivo de transmitir el idioma y la cultura alemana.

CENTRO DE LA CULTURA

PLURINACIONAL SANTA CRUZ

Ubicación: Calle René Moreno #369
Lunes a viernes: 08:00 a 12:00 y 14:30 a 18:30

ph: GAD SCZ

El Centro de la Cultura Plurinacional Santa Cruz, es el epicentro del arte y cultura nacional, siendo el reflejo de la identidad plurinacional de Bolivia. Alberga exposiciones permanentes sobre el arte del oriente del país y eventos que celebran la riqueza y la diversidad de las diferentes etnias y culturas que dan forma a Bolivia. Además, el Centro de la Cultura Plurinacional es conocido por su agenda cultural, con una amplia variedad de eventos, como conciertos, presentaciones teatrales y proyecciones de películas. Adicionalmente, si estás interesado más sobre la historia y las tradiciones de Bolivia, no podes perderte el archivo histórico que alberga este centro cultural. Manuscritos, fotografías antiguas y otros tesoros históricos te esperan para revelarte los secretos del pasado de Santa Cruz y de todo el país en su biblioteca especializada en arte y cultura.

AECID

CENTRO DE FORMACIÓN DE LA COOPERACIÓN ESPAÑOLA

Ubicación: Calle Arenales #583
Atención: Lunes a viernes: 08:00 a 18:00

ph: GAD SCZ

Punto de diversas manifestaciones artísticas, conferencias, talleres, presentaciones de libros, representaciones teatrales y proyecciones como el Festival Internacional de Cine de Santa Cruz y la proyección de Cine Español. El Centro de Formación AECID cuenta con salas de exposición para la realización de cursos y seminarios, un teatro para más de 240 personas y una moderna biblioteca. El Centro de Formación AECID está presente en la ciudad desde 1987, es una unidad especializada en gestión del conocimiento para el desarrollo que forma parte de la red de centros de la Cooperación Española en América Latina y el Caribe.

CBA

(BIG APPLE) CENTRO BOLIVIANO AMERICANO

Ubicación: Calle Sucre #364
Atención: Lunes a viernes: 07:30 a 22:00

ph: GAD SCZ

La posibilidad de especializarte en el idioma inglés, acceder a clases de voleibol, ballet, a una biblioteca con más de 5.000 volúmenes, salones de conferencia, teatro, cine, galería de arte, a un museo denominado "Science Corner" y una programación de actividades culturales a lo largo del año es todo lo que ofrece el "Centro Boliviano Americano" (Big Apple), que desde 1958, viene gestionando actividades académicas en el idioma inglés, y otras actividades socioculturales y artísticas que benefician a la sociedad cruceña.

MUSEO SCIENCE CORNER

Ubicación: Calle Sucre #365
Clases de teatro Lunes y miércoles: 19:30 a 21:00
Sábado: 10:00 a 12:00
Cine CBA Martes a domingo: 20:00

ph: CBA

El Museo "Science Corner" es el primer museo interactivo de nuestra ciudad que cuenta con una sala de exhibición, en la cual se destacan dos grandes áreas: "El Universo y los Planetas" y "La Evolución y el ser humano". En el "Universo y el Planeta" podés apreciar el sistema solar a escala, así como la exploración del universo, un mapamundi con las capitales de los diferentes países del mundo entre otras novedades más. Al lado opuesto se encuentra el sector de "La Evolución y el Ser Humano", en donde encontrarás un animal prehistórico junto al hombre de las cavernas. Acompañando esta exhibición se expone una diversidad de cráneos, mostrando la evolución del hombre en las diferentes etapas. El museo también cuenta con una sala de cine, con una capacidad aproximada para 140 personas, donde se proyectan películas informativas, didácticas, cuidadosamente seleccionadas para que sean aprovechadas en su totalidad por el público asistente.

MELCHOR PINTO PARADA

CENTRO CULTURAL

Ubicación: Calle Sucre #50
Atención: Lunes a viernes: 09:00 a 22:00
Sábados: 15:00 a 22:00 Domingo: 11:00 a 18:00

ph: GAD SCZ

ph: GAD SCZ

¿Estás en el corazón de la ciudad de Santa Cruz y querés conocer un lugar donde se desarrollaron importantes eventos históricos de activismo y liderazgo de luchas cívicas de Santa Cruz mientras degustás un cafecito?

Si tu respuesta es sí, entonces tenés que visitar el "Centro Cultural Melchor Pinto Parada". Se encuentra ambientado en una pintoresca casona de principios del siglo XX, con historia y características de antaño, dos patios centrales, rodeados por salas, un aljibe, tejas coloniales y blancas paredes. La casa lleva el nombre de Melchor Pinto Parada, uno de los personajes más notables en la historia cruceña de la segunda mitad del siglo XX. En esta casa vivió con su esposa y familia, donde se desarrollaron importantes eventos históricos durante sus años de gran activismo y liderazgo al aporte del crecimiento de Santa Cruz y que hoy alberga un centro cultural, que lleva asimismo, su nombre. El Centro Cultural Melchor Pinto Parada se presenta como un espacio articulador de las diversas artes que promueven la identidad y la cultura cruceña: música, teatro, literatura, pintura, escultura, audiovisuales (video y cines), fotografías, danza, presentaciones de libros, conversatorios, lecturas poéticas, entre otras manifestaciones. Una de sus principales salas es donde hace homenaje al legado de Melchor Pinto Parada, sintetizando su vida como médico y líder cívico. Asimismo, el centro posee un área acogedora para la recreación y socialización siguiendo la tradición del cafecito cruceño y el encuentro en la plaza 24 de septiembre, ambientada en un patio colonial con galerías que rodean las exposiciones.

CENTRO CULTURAL
FELICIANA RODRIGUEZ

Atención: Lunes, Miércoles y Viernes: 14:00 a 19:00
Martes y Jueves: 14:00 a 16:00
Sábado: 09:00 a 12:00; 14:00 - 16:00
Ubicación: Calle Ñuflo de Chávez # 21, entre René Moreno y Chuquisaca

Centro Cultural "Feliciana Rodríguez", punto de encuentro de expresiones culturales de artistas de la ciudad. Se denomina una plataforma para la promoción y formación de niños y jóvenes en danza, teatro, música y demás expresiones artísticas.

ESPACIO DE ARTE
EMERGENTE

Ubicación: Av. Beni, Calle Tacuarembó #2080 entre 2do. y 3er anillo.
Atención: Lunes a Sábado 10:30 a 20:00 Domingo 18:30 a 21:00

Espacio de arte y diseño conformado por artistas locales. Un rincón cargado de expresiones libres, mucha pasión y miles de sueños. Constantemente muestran nuevas creaciones para llenarlos de obras únicas e inspiración.

CENTRO CULTURAL
VILLA PRIMERO DE MAYO

Ubicación: Calle 3, zona oeste
Atención: Lunes a Viernes: 09:00 a 12:00 15:00 a 20:00

El Centro Cultural Municipal de la Villa Primero de Mayo, es un espacio establecido para el desarrollo de la cultura y artes escénicas, aquí se desarrollan múltiples talleres. Se encuentra en una moderna edificación de dos bloques; el primero con tres salas de música, salón de coros y de danza. La segunda área está destinada a los talleres y biblioteca. El teatro tiene la capacidad para 120 personas, cuenta con camerinos y cabinas de control e iluminación.

CENTRO CULTURAL GUARACAL
LA MORITA

Ubicación: Barrio La Morita, calle Augusto Zambrana Terán entre Av. Santos Dumont y Radial 13

El Centro Cultural Guaracal - La Morita se ubica en la zona sur de la ciudad capital y fue uno de los primeros espacios creados por la Municipalidad. Cuenta con una Biblioteca local, escenario y otros espacios para el uso de los vecinos. Lo dirige el popular gestor cultural Eduardo Quiller. Forma parte de la Red de Bibliotecas Municipales.

CENTRO CULTURAL
SEOANE

Ubicación: Calle Seone Nº 123 entre 21 de Mayo y Libertad
Atención: Lunes a Sábado: 16:00 a 21:00

Un espacio ideal para conciertos, espectáculos, obras de teatro, conferencias, eventos artísticos y culturales. Un espacio cultural de gestión independiente en Bolivia, ubicado en la ciudad de Santa Cruz de la Sierra, surge de una casa refaccionada, considerada patrimonio histórico de nuestra ciudad. La refacción fue realizada con fondos propios, con la finalidad de convertir la casa en un espacio de formación teatral, con elencos teatrales de adultos, niños y niñas, posicionándose como el primero en la ciudad de Santa Cruz.

CENTRO CULTURAL
LA CUCHILLA

Ubicación: Avenida Vallegrande, entre La Colina y Hugo Barranco

Ubicado en la zona sur de la ciudad de Santa Cruz de la Sierra, el centro cultural "La Cuchilla" es un espacio municipal que atiende las demandas para el uso de los ciudadanos en actividades culturales. Cuenta con biblioteca, escenario y otros ambientes además de formar parte de la red de bibliotécas departamentales.

CENTRO CULTURAL
RONALD ROA

Ubicación: Av. Beni, Calle Tacuarembó #2080 entre 2do. y 3er anillo.
Atención: Lunes a Sábado 10:30 a 20:00 Domingo 18:30 a 21:00

Brindan su escenario a artistas emergentes en áreas como la música, pintura, cerámica, canto, baile y poesía. El lugar, lleva su nombre gracias al Historiador boliviano, artista plástico Ronald Roa, importante figura del arte nacional que dejó con nosotros un importante legado a través de sus libros, el más conocido es "Historia del Arte en Santa Cruz".

ESCUELA
NUEVA ACRÓPOLIS

Ubicación: Calle Potosí # 462, entre Manuel Ignacio Salvatierra y Republiquetas
Atención: Lunes a viernes: 18:00 a 22:00
Sábado: 17:00 a 20:00

Nueva Acrópolis es una Escuela de Filosofía, a la manera clásica, que promueve el desarrollo y la mejora del ser humano y de su entorno, a través de una educación integral, basada en la filosofía, la cultura y el voluntariado.

ESPACIO COLABORATIVO
LA FEDERAL

Ubicación: Calle Ballivián N° 66, entre las calles Chuquisaca y René Moreno
Atención: Lunes a domingo: 09:00 a 22:00

¿Estás en el centro histórico de la ciudad y buscás un ambiente bohemio para descubrir y entretenerte? Visitá "La Federal" es espacio multidisciplinario donde podés disfrutarde eventos culturales como teatro, exposiciones de pintura, presentaciones de libro y grupos musicales. Esto transcurre en sus galerías que se pueden recorrer a lo largo de sus 5 ambientes, donde también ofrecen comida vegana, ropas recicladas, helados, un bar y una sala con libros para leer y comprar. Brindan incluso talleres de diferentes temáticas como poesía, dibujos, pintura, origami entre otras. Los sábados en las mañanas presentan una feria con productos orgánicos saludables.

GALERIA DE ARTE Y CAFÉ
KOQUI HANDALL

Ubicación: Barrio Equipetrol. Avenida San Martín, cuarto anillo. Manzana 20, torre 2, planta baja. Distrito 1
Atención: Lunes a viernes: 10:00 a 19:00

Galería de Arte Koqui Handal es un lugar que exhibe obras en diversos formatos que el artista y empresario José Luis Koqui Handal ha desarrollado a lo largo de 30 años. Esta galería se inauguro en el Edificio Manzana 40 en el 2022, como un tributo a la ciudad y la nueva infraestructura del edificio, un icono de la arquitectura cruceña.

TEATRO BAR
MERAKI

Atención: Variables de acuerdo a cada actividad
Ubicación: Calle Ballivián N.º 159, entre las calles La Paz y Chuquisaca

¿Buscás un lugar que fusione el teatro con la vida nocturna y espectáculos en vivo? Meraki Teatro Bar es sin duda el lugar, que, a través de su innovador concepto de combinar las artes escénicas en un ambiente festivo, hace de su estadía toda una experiencia.Cuenta con un amplio escenario, brindando las mejores condiciones de sonido e iluminación para artistas de diversas expresiones artísticas. Son parte de su programación permanente: conciertos de distintos géneros musicales, funciones de teatro, shows de humor, espectáculos de danza, proyecciones de cine, documentales y videos en pantalla gigante. Su auditorio también ofrece conferencias y capacitaciones sobre diversas temáticas, buscando enriquecer la extensa oferta cultural existente en nuestra ciudad.

CARRERA DE ARTE
UAGRM

Ubicación: C. Seoane #141, entre Libertad y 21 de Mayo
Atención: Lunes a viernes: 08:30 a 12:00 y 15:00 a 18:30

La Carrera de Estudio del Arte, perteneciente a la Universidad Autónoma Gabriel Rene Moreno contribuye con la formación de licenciados en Artes a nivel profesional en el territorio Nacional. Los estudiantes realizan actividades culturales y artísticas en beneficio de instituciones privadas y públicas, además las exhiben a la sociedad de manera periódica

MUSEO HISTÓRICO MILITAR
HÉROES DE LA GUERRA DEL CHACO

Ubicación: Calle Bolívar #402
Atención: Lunes a viernes: 08:30 a 12:00 y 15:00 a 18:30

El museo alberga artefactos, armamento y documentación que se utilizaron en la Guerra del Chaco entre Paraguay y Bolivia. Tiene una biblioteca dotada de libros históricos sobre los sucesos de la Guerra del Chaco, donde tenés la oportunidad de profundizar tus conocimientos sobre los hechos reales de la guerra. Cuenta con una plaza de honor que representa para el soldado boliviano el lugar sublime donde se rinde culto al patriotismo. También está el panteón de los héroes, que es el mausoleo de la patria, donde reposan los restos mortales de los héroes de la Guerra del Chaco

MUSEO
GUARANÍ ISOSEÑO

Ubicación: Av. Marcelo Terceros, Tercer Anillo Externo, 3 cuadras antes del Zoo
Atención: Lunes, Miércoles y Viernes: 14:00 a 19:00
Martes y jueves: 14:00 a 16:00 Sábado: 09:00 a 12:00; 14:00 - 16:00

El Museo Guaraní valora y difunde la cultura guaraní en ámbitos urbanos y rurales fortalecidos. Cuenta con una instalación física que le permite exhibir y relacionar los bienes y valores patrimoniales de las 27 comunidades que establecieron su origen fundacional, integrados a la Capitanía del Alto y Bajo Isoso.

TEATRO
RENÉ MORENO

Ubicación: Calle Sucre, esquina Potosí / Casco Viejo.

Nació como cine en 1957, vivió la época dorada de las películas de Hollywood. El Teatro Rene Moreno ha sido parte del entretenimiento cruceño; primero como cine y ahora como teatro. Como teatro tuvo éxito y apuesta por seguir adelante, con innovaciones en el ámbito artístico para ofrecer a Santa Cruz, con funciones importantes de artistas nacionales y extranjeros.El teatro también lo ocupan para conferencias y otro tipo de eventos. Puede contratarse de acuerdo al espacio que se va a utilizar, ya sea 100 o 200 o más butacas.

MUSEO
ARTE CAMPO

Ubicación: Monseñor Salvatierra 407
Atención: Lunes a Viernes 9:00 - 12:30 y 15:30 -19:00
Sábado 9:00 - 12:30

Museo Artecampo alberga una colección de piezas contemporáneas de los grupos étnicos guaraníes, ayoreos, guarayos, chiquitanos y comunidades interculturales. Este lugar cuenta con salas de exhibición y una agenda variada con visitas guiadas, talleres, exposiciones temporales, conversatorios, encuentros con las artesanas con el objetivo de difundir y exhibir lo mejor de las manifestaciones culturales originarias y la producción artística de indígenas y campesinos.

CASA CERO

Ubicación: Calle Sucre, esq. René Moreno

ph: GAD SCZ

ph: GAD SCZ

La denominada “Casa Cero”, ubicada en el casco viejo de Santa Cruz, es la primera casona que se construyó en la ciudad, convirtiéndose en un lugar icónico e histórico, en plena esquina de la plaza 24 de Septiembre. Lo importante de este lugar es que preserva las cualidades de la estructura típica colonial cruceña, con un patio central y corredores en su interior. Actualmente, en esta casona se ofrecen diferentes opciones culinarias como una cafetería, heladería y un restaurante de comida rápida.

ph: GAD SCZ

MUSEO
DE LA INDEPENDENCIA

Ubicación: Calle Independencia, esq. Ayacucho
Atención: Lunes a viernes: 9 :00–12:00 y 15:00 – 19:00

ph: Museo de la Independencia

El “Museo de la Independencia” difunde las historias de las batallas más importantes, que derivaron en la independencia cruceña. Es impulsado por la Sociedad de Estudios Geográficos e Históricos de Santa Cruz.

MUSEO DE ARTE
CONTEMPORÁNEO

Ubicación: Calle Sucre, esq. Potosí
Atención: Lunes a viernes: 08:00 a 19:00

ph: Museo de Arte Contemporáneo Santa Cruz

El “Museo de Arte Contemporáneo” único en su género en Bolivia, dedica su espacio a la difusión de las diversas expresiones artísticas, a escala local, nacional e internacional. Cuenta con salas de exposición, dos patios dedicados a la cultura y una importante preservación de arte. Su patrimonio alberga todas las tendencias de la plástica nacional desde la segunda mitad del siglo XX hasta nuestra actualidad, con una colección de 300 obras de arte en pintura, escultura, dibujo y grabado, reflejando las sucesivas generaciones de artistas bolivianos y extranjeros. Asimismo, es sede de la Bienal Internacional de Artes Visuales, del premio Municipal de Pintura y Escultura, del Festival de Música Renacentista, del Festival de Música Barroca Americana Misiones de Chiquitos y del Festival Internacional de Teatro Santa Cruz de la Sierra.

MUSEO DE HISTORIA REGIONAL

Ubicación: Calle Junín #151, entre Libertad y 21 de Mayo
Atención: Lunes a viernes: 08:00 a 14:00

ph: GAD SCZ

El Museo de Historia Regional es un espacio que promueve la difusión de la historia y la cultura cruceña y boliviana al mundo. Para la preservación del patrimonio histórico, documental, arqueológico y cultural de Santa Cruz, el museo posee el archivo en una Biblioteca y Hemeroteca, siendo las más valiosa del departamento. Además de sus colecciones arqueológicas y pictóricas, debidamente fichadas como exigen las autoridades nacionales de Cultura. La investigación es una de las funciones más importantes del museo, y aunque los primeros años fue muy difícil realizarla, se organizaron ciclos de conferencias sobre historia cruceña. Es una importante unidad dependiente de la Universidad Autónoma Gabriel René Moreno que funciona desde 1996.

ph: GAD SCZ

ph: GAD SCZ

MUSEO DE HISTORIA NATURAL

NOEL KEMPFF MERCADO

Ubicación: Av. Irala #565, entre Av. Ejército Nacional y Velarde
Atención: Lunes a viernes: 08:00 a 12:00 y 15:00 a 18:30

ph: GAD SCZ

ph: GAD SCZ

El Museo de Historia Natural "Noel Kempff Mercado" es uno de los centros más importantes de Bolivia en cuanto a documentación de patrimonio natural e investigación básica y aplicada. Alberga toda una colección científica en materia de biodiversidad. Se dedica a generar conocimiento, investigación, extensión, capacitación y/o educación a estudiantes, docentes, representantes de las comunidades locales y de la sociedad en general para promover la conservación y el uso sostenible de los recursos naturales.

ph: GAD SCZ

MUSEO DE LA CIUDAD ALTILLO BENI

Urbanización: Calle Beni #50, entre Bolívar y Sucre
Atención: Lunes a viernes: 08:00 A 16:00
Sábado: 16:00 a 20:00

ph: GAD SCZ

ph: GAD SCZ

El "Museo de la Ciudad Altillo Beni" es una de las edificaciones más antiguas de Santa Cruz de la Sierra. Construida en una vieja casona con más de 170 años de existencia en la urbe. Es conocida también como "Los altos de la calle Beni", pues sus propietarios levantaron el corredor exterior con la finalidad de tener un lugar desde el cual observar el popular juego de 'la sortija', que se realizaba a lo largo de la calle. Considerado un referente de la arquitectura cruceña del siglo XIX por sus elementos originales, como horcones, capiteles, tejas musleras, muros de tabique, puertas, ventanas con balaustre y singularidad. Se construyó a fines del siglo XVIII o principios del siglo XIX, y aún conserva su diseño original, tanto en la fachada como en su interior. Actualmente este espacio se dedica a la difusión de las diversas expresiones artísticas, a escala local, nacional e internacional. Cuenta con salas de exposición, un patio colonial y una terraza.

ph: GAD SCZ

BIBLIOTECA MUNICIPAL

ENRIQUE KEMPFF MERCADO

Ubicación: Av. Monseñor Rivero, 1er anillo (Plazuela del Estudiante)
Atención: Lunes a viernes: 08:00 a 16:00 horas

ph: GAD SCZ

Centro principal de lectura de la ciudad. Encontrarás una importante colección de libros, así como también de una hemeroteca, un archivo digital, salas de actividades y otros espacios dedicados a la difusión literaria. La Biblioteca Municipal "Enrique Kempff Mercado" funciona desde hace más de 40 años, pero oficialmente atiende en el edificio de la plazuela del Estudiante desde fines de los años 90.

AVIÓN PIRATA

Ubicación: Av. Uruguay, 1er anillo

ph: GAD SCZ

Si pasás por la zona de la Av. Uruguay, te encontrarás con el "Avión Pirata" de Santa Cruz. La denominación de su nombre se debe a la historia que hay detrás de este avión. En julio del 1961, una aeronave "misteriosa" fue obligada a aterrizar en el aeropuerto "El Trompillo". Este avión llevaba contrabando a diferentes países y lo hacía con varias paradas. Se trataba de un cuatrimotor "Constellation" con matrícula norteamericana. Fue capturada por la Fuerza Aérea Boliviana y su historia se sitúa entre una de las particularidades de la ciudad.

En julio de 1972, fue trasladado a la avenida Uruguay de la populosa zona del barrio "El Tao" para formar parte del nuevo parque "Boris Banzer Prada", más conocido como "Plaza del Avión Pirata". Desde entonces, ha funcionado como biblioteca, snack, agencia de viajes y turismo y ha sido 'adoptado', junto a las áreas que lo circundan, por empresas que se hicieron cargo de su mantenimiento. También se ha convertido en el punto de encuentro para las bandas que esperan a ser contratadas para tocar música regional oriental.

SAGUAPAC

Ubicación: Av. Rio Grande 2323
Atención: Horario de oficina

ph: GAD SCZ

La historia de esta gigante corporativa, data de finales de los años 30s', tiempo de lucha para el pueblo cruceño por el acceso al 11% de las regalías petroleras, sin embargo fueron20 años de espera para que se aplique esta normativa. Una vez aplicada, se crea a inicios de los años 60s' el Comité de Obras Públicas (COOPP), que comienza en 1973 a administrar los servicios de Agua Potable y Alcantarillado Sanitario. Aquí surge por primera vez SAGUAPAC, como un autarquía dependiente de este organismo. Este evento marca un hito histórico de desarrollo para Santa Cruz de la Sierra, rompiendo los esquemas de crecimiento que se le habían impuesto a esta región. Según datos actualizados al 2022, las métricas de SAGUAPAC indican que la cooperativa abastece de agua potable a 1.412.961 habitantes. No dejes pasar la oportunidad de conocer Santa Cruz, de sumergirte en el apogeo de su desarrollo. En 1978 se crea CORDECRUZ, quien absorbe este comité e impulsa mediante una consulta pública, la consolidación de la cooperativa de servicios básicos. Sin embargo es el 19 de junio de 1979 que SAGUAPAC asume esta responsabilidad con el pueblo cruceño.

CRE

Ubicación: Av. Busch, esq. Honduras
Atención: Horario de oficina

ph: GAD SCZ

CRE es la Cooperativa más grande del mundo en cuanto a número de asociados pues aglutina a más de medio millón de socios.

Todo comenzó en el año 1900, cuando la empresa cinematográfica "Moreno y Cla", instaló un motor generador para usar electricidad al proyectar películas, sembrando esa semilla de necesidad entre todos los cruceños. Sin embargo, no hasta el año 1915 que el entonces alcalde, licitó la iluminación de la ciudad de manera pública, algo que se convirtió en un incentivo para que los empresarios inviertan en equipos de electricidad. Es así, que en 1923 comienza a funcionar la primera planta de generación eléctrica, en el lugar conocido como la Maestranza, abarcando un perímetro de electrificación de la Plaza principal a la del Mercado Central, instalando alumbrado público como primera conexión. En Santa Cruz, estaba a cargo la empresa Servicios Eléctricos Santa Cruz (SELSAC). Sin embargo, los vecinos notables y representantes de instituciones cruceñas, fundan un 14 de noviembre la Cooperativa Rural de Electrificación (CRE), en inmediaciones de la Alcaldía Municipal, fijándose como objetivos principal el brindar un servicio de calidad de energía eléctrica, con confiabilidad y compromiso de responder las exigencias de la población. Sin duda alguna, la fundación de la Cooperativa Rural de Electrificación, representa el inicio de lo que hoy como cruceños venimos construyendo; una región que avanza consolidándose como un centro de desarrollo económico, industrial y cultural.

COMITÉ CÍVICO PRO SANTA CRUZ

Ubicación: Calle Cañada Strongest #70

ph: GAD SCZ

El Comité Cívico Pro Santa Cruz es una institución emblemática en el departamento de Santa Cruz. Se fundó a las cinco de la tarde del 30 de octubre de 1950, en el salón de actos del edificio central de la Universidad Autónoma Gabriel René Moreno y a iniciativa de su Federación Universitaria Local. Desde entonces a la fecha, el Comité Cívico Pro Santa Cruz ha sido un actor fundamental en la historia y el desarrollo de la sociedad cruceña.

El Comité Cívico Pro Santa Cruz tiene como objetivos primordiales:

- ***Promover y defender, por todos los medios legítimos y legales disponibles, la unidad departamental, la democracia, la autonomía y nuestro sistema productivo como medio para alcanzar el desarrollo humano, cultural, social y económico de todos los habitantes del Departamento.***
- ***Precautelar, bajo la premisa del desarrollo sostenible, la racional explotación de sus recursos naturales y la protección del medio ambiente;***
- ***Preservar los valores morales, la identidad regional, y asumir la defensa de los derechos individuales y colectivos, para alcanzar el bien común.***
- ***Promover, con los pueblos indígenas oriundos del departamento de Santa Cruz y en ese marco, sus valores, usos y costumbres.***

A lo largo de su historia, el Comité Cívico Pro Santa Cruz ha liderado importantes movimientos en defensa de los intereses de la región, luchando por la autonomía y el desarrollo de Santa Cruz. Uno de sus hitos más destacados fue la demanda de la creación de un estatuto autonómico para el departamento, que finalmente fue aprobado en 2008, otorgando a Santa Cruz mayores facultades de autogobierno. La trascendencia del Comité Cívico Pro Santa Cruz en la sociedad cruceña es innegable, ya que ha sido un referente para la defensa de los derechos y la identidad de la región. Gracias a su labor, Santa Cruz ha logrado consolidarse como uno de los motores económicos y culturales de Bolivia. Si visitas Santa Cruz, no podés dejar de conocer la historia y el legado del Comité Cívico Pro Santa Cruz, una institución que ha dejado una huella imborrable en la sociedad cruceña.

CRISTO REDENTOR

Ubicación: Entre Av. Cristo Redentor, Cristóbal de Mendoza y Monseñor Rivero

ph: GAD SCZ

SÍMBOLO DE HOSPITALIDAD, FÉ E IDENTIDAD DE LOS CRUCEÑOS!

ph: Fundación Hombres Nuevos

El monumento "Cristo Redentor", con 7.8 metros de altura y de brazos extendidos y mirada serena, es uno de los primeros que tuvo Santa Cruz de la Sierra. Es considerado un símbolo para los cruceños, siendo uno de los más destacados exponentes de la fe católica y lugar donde se desarrollan un sinnúmero de actos de lucha cívica, convirtiéndose en testigo y escenario de grandes hitos históricos.

Esta escultura fue realizada en bronce por el escultor cochabambino Emiliano Luján Sandoval en la ciudad de La Paz. Se trasladó de§ forma fragmentada a Santa Cruz de la Sierra en 1961. Se erigió durante la conmemoración del IV Congreso Eucarístico Nacional, a solicitud de los promotores del evento, a cargo de Luis Rodríguez Pardo. Fue adquirido con fondos recaudados por la Asociación de Damas Cruceñas residentes en La Paz y el Comité de Obras Publicas Prefectural.

La inauguración oficial fue el 10 de agosto de 1961, siendo hasta hoy la mayor escultura de bronce que se haya ejecutado en el país. La actual apariencia de cemento se debe al recubrimiento realizado durante su restauración. La elegante esbeltez de su figura de brazos levantados, enfatizada por el pedestal del hormigón armado en el que se asienta, lo convirtió en uno de los hitos urbanos de la ciudad. Ha sido declarado Patrimonio Cultural Material del Estado en el 2013.

CATEDRAL METROPOLITANA

BASÍLICA MENOR DE SAN LORENZO

Ubicación: Plaza 24 de Septiembre, acera sur

Atención :
(oficina y mirador) Lunes a sábados: 9:00 a 12:00 / 15:00 a 18:30
Domingos: 15:00 a 18:00 (solo mirador)

Iglesia abierta Lunes: 7:30 a 11:00 / 15:00 a 19:00
Martes a viernes: 7:30 a 12:00 / 15:00 a 19:00
Sábados: 7:30 a 8:30 / 15:00 a 19:00
Domingos: 6:30 a 12:00 / 17:00 a 20:30

Misa Lunes a viernes: 8:00 / 18:30
Sábados: 8:00 / 18:00
Domingos: 7:00 / 9:00 / 11:00 / 18:00 / 19:30

Museo Lunes a viernes: 9:00 a 12:00 / 15:00 a 18:00
*Durante las misas no hay visitas turísticas

ph: GAD SCZ

Si caminás por el centro de la ciudad, en el corazón mismo del Centro Histórico, te encontrarás con una obra extraordinaria, cargada de espiritualidad que expresa la historia y la fe religiosa del Oriente Boliviano: La Catedral Metropolitana de Santa Cruz de la Sierra o también llamada Basílica Menor de San Lorenzo Mártir. Es el principal templo católico de la ciudad y el segundo mayor templo de Bolivia, que reemplazó a la antigua catedral de madera. Su fachada de estilo barroco, te dejará maravillado desde el primer momento en que la veas.

Al entrar, podrás observar sus bóvedas de madera, las mayores del continente, que dignifican su interior clásico. El altar mayor posee recubrimientos de plata repujada, originales de las Misiones Jesuíticas del siglo XVIII. Se destaca su fachada, la segunda más grande de América y sus torres en estilo neoclásico, con resabios del barroco, que anteceden las tres naves. Asimismo, parte de su atractivo son las imponentes torres de ladrillo de color tierra en las cuales se encuentran la campana y el reloj que se conservan desde el año de su edificación.

Su construcción inicia en 1839, bajo el diseño del arquitecto francés Felipe Bertrés. Monseñor Santistevan decide terminar la obra y en 1904 contrata a León Mousnier, otro francés, que la concluye en 1915. Se consagra como nueva catedral en agosto de ese año. La Catedral fue restaurada integralmente entre 1968 y 1983 y durante este proceso se removió el revoque de cal y arena de las fachadas y los campanarios. Se dejó al descubierto la belleza del ladrillo especialmente cocido para destacar cada detalle del edificio. En 1988, durante la visita que hizo a la ciudad el papa Juan Pablo II, se le otorga el rango de Basílica Menor de San Lorenzo Mártir. Pero la belleza de la catedral no se limita solo a su arquitectura, sino que también alberga importantes obras de arte sacro distribuidos en cuatro salas y una pinoteca, que podrás observar en el "Museo Catedralicio Mons. Carlos Gericke Suarez", ubicado al interior de la misma catedral. Si querés conocer más sobre la historia y el arte sacro de la Basílica Menor de San Lorenzo, la Catedral Metropolitana de Santa Cruz de la Sierra, te sugerimos realizar un paseo por el interior de la iglesia y visitar el mirador turístico que se encuentra en el acceso a las torres desde donde podrás admirar la ciudad.

ph: GAD SCZ

ph: GAD SCZ

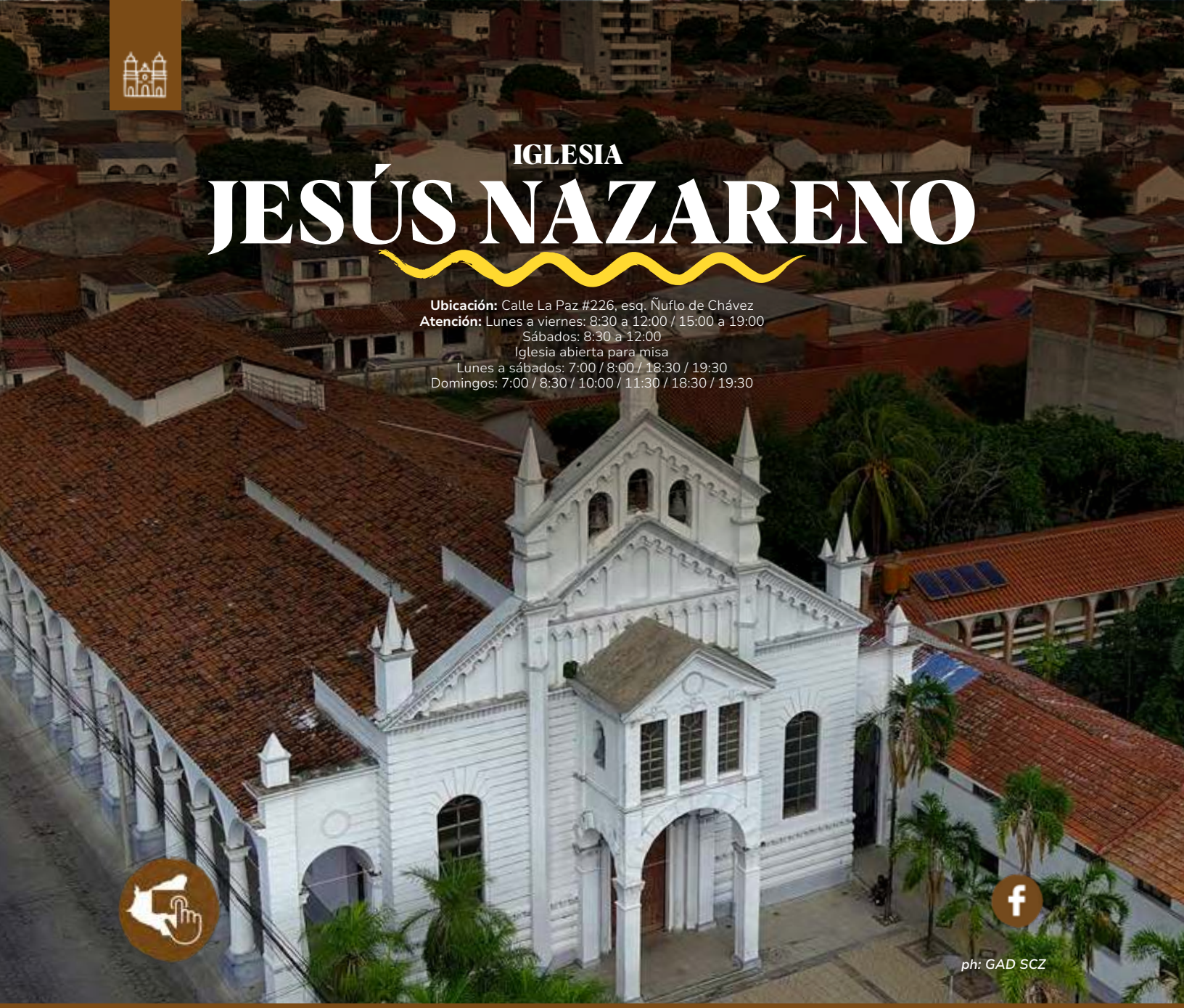

IGLESIA

JESÚS NAZARENO

Ubicación: Calle La Paz #226, esq. Ñuflo de Chávez
Atención: Lunes a viernes: 8:30 a 12:00 / 15:00 a 19:00
Sábados: 8:30 a 12:00
Iglesia abierta para misa
Lunes a sábados: 7:00 / 8:00 / 18:30 / 19:30
Domingos: 7:00 / 8:30 / 10:00 / 11:30 / 18:30 / 19:30

ph: GAD SCZ

Construida a finales del siglo XVII como oratorio del cementerio de la ciudad, era conocida como la Capilla de la Misericordia; además, se celebraban bautizos y matrimonios, según los registros. Al trasladarse el viejo panteón, se convierte en Parroquia Jesús Nazareno, instituyéndose a la Virgen del Carmen como su patrona. En 1880 se construye, según el modelo maderero que también aplicaron los jesuitas, en las Misiones de Chiquitos y Moxos, sin embargo, hasta hoy continúa siendo conocida como La Capilla. Entre 1899 y 1905 se amplían y se reforman completamente las tres naves, siguiendo los lineamientos de la arquitectura ecléctica, con base al neogótico italiano. Esta obra fue diseñada y ejecutada por el constructor italiano Simone Marchetti, con la colaboración del Franciscano Camilo Agrazar. El templo fue la primera obra eclesiástica de magnitud levantada en Santa Cruz, gracias a la solvencia económica del auge de la goma. Se destacan la gran fachada, la elegante galería lateral de arcos de medio punto sobre columnas toscanas y las bóvedas de madera, que están debajo de la cubierta maderera. Entre 2013 y 2020, con el apoyo del Municipio, se realiza una tarea integral de restauración, que recupera la policromía original de las bóvedas de madera, con más de 100 años de antigüedad. Se restauran la cubierta, las galerías y el altar mayor. Este proceso logró devolver la dignidad espacial a este patrimonio cultural de Bolivia, respetando su estilo ecléctico de inspiración italiana en sus detalles neogóticos y clasicistas.



IGLESIA

SAN FRANCISCO

Ubicación: Calle Aroma, esq. Arenales
Atención: Lunes a viernes: 8:00 a 12:00 / 14:30 a 18:30
Sábados: 8:00 a 12:00
Iglesia abierta
Todos los días: 6:00 y 18:00 (una hora antes de cada misa)
Misa: Lunes a sábados: 7:00 / 19:00
Domingos: 7:00 / 9:00 / 11:00 / 19:00

ph: GAD SCZ

La actual iglesia de San Francisco es la única que no reemplaza a un antiguo edificio maderero, siendo construido originalmente por la Orden Franciscana entre 1856 y 1860. Estuvieron a cargo de la obra, el español Manuel Viudez y los italianos Damián Conti, Basilio Bruzó y Pedro Unía, convirtiéndose en la primera iglesia cruceña en ser ejecutada íntegramente en ladrillo y cal. Fue, también, la primera en ser resuelta con columnas clásicas sosteniendo bóvedas falsas de madera y su campanario fue el primero de la ciudad. Sufrió varios cambios en los que participó el prior Camilo Agrazar, que también trabajó en las obras de la Jesús Nazareno y la Catedral. Su arquitectura neoclásica, de inspiración italiana, posee una portada a modo de espadaña, que resulta fundamental en la historia cruceña, pues sus columnas toscanas inspiraron a los horcones de galería de la ciudad. Construida originalmente como hospicio, la actual casa conventual fue un albergue para los misioneros encargados de los pueblos misionales de Guarayos y de Chiquitos, durante la segunda mitad del siglo XIX y principios del siglo XX. Los trabajos de restauración del convento y de la iglesia empezaron en 1986 y concluyeron en 1990. Es Patrimonio Nacional. De todos los templos cruceños, es la edificación religiosa más antigua de la ciudad. Aunque otras parroquias y la Catedral fueron creadas previamente, sus edificios son posteriores a esta iglesia, cuyo atrio exalta su elegante frontispicio y campanario.



PARROQUIA SAN ROQUE

Ubicación: Calle Velasco, esq. Monseñor Salvatierra
Atención Oficina Parroquial: (calle Monseñor Salvatierra # 244, entre Velasco y Colón) Lunes a viernes: 9:00 a 12:00 / 15:00 a 18:00 - Sábados: 9:00 a 12:00

Misa: Lunes a sábados: 19:00 - Domingos 7:00 / 9:00 / 17:30 / 19:00
Iglesia abierta: Todos los días 30 minutos antes de la misa
Confesiones: Lunes a domingos (media hora antes de la misa)

ph: GAD SCZ

Es uno de los templos más tradicionales de la ciudad, ubicado en el antiguo barrio Chaparé. En 1843, el filántropo Andrés Salvatierra promovió la construcción de una capilla en honor a Nuestra Señora del Patrocinio, que se inauguró en 1850. Se convierte en parroquia en 1858, en honor a San Roque, y se decide construir un nuevo templo, impulsado en 1882 por el filántropo Teodoro Sánchez Bustamante. Él encarga al italiano Carlos Caldario y al austriaco David Cronenbold, la construcción de la actual iglesia, que es consagrada en agosto de 1892. Es la única iglesia cruceña que responde al modelo maderero virreinal o colonial, con tres naves definidas por esbeltas columnas de madera y paredes de barro, generando un gran espacio interior. La fachada historicista, con campanario al centro, fue varias veces modificada convirtiéndose en un hito urbano reconocido por la comunidad. A fines del siglo XX, tras varios esfuerzos parciales, los parroquianos de San Roque restauran el templo y la casa parroquial. Gracias a su singular tipología maderera misional, con sus corredores o galerías madereras laterales, es sede del Festival Internacional de Música Renacentista y Barroca Americana Misiones de Chiquitos, desde 2000.

PARROQUIA
SAN ANDRÉS

Ubicación: Calle Charcas # 73, esquina calle Beni **Atención:** Lunes a sábados: 7:00 a 19:30 **Misa:** Lunes a sábados: 8:00 y 19:30 Domingos: 8:00 / 9:30 / 11:00 / 18:00 / 19:30

Entre 1844 y 1849 se construye la primera iglesia de San Andrés, financiada por el monseñor José Andrés de Salvatierra en las proximidades de la laguna El Arenal. Es el más nuevo de los templos academicistas cruceños, siendo el último en ser construido con muros de ladrillo asentados en cal. Aunque su lenguaje arquitectónico es neorromántico, el espíritu neocolonial se hace evidente en su volumen, interior y detalles ornamentales. En 2019 se lo enriqueció simbólicamente con un retablo de madera inspirado en los templos misionales de estilo barroco.

CAPILLA
LOS HUÉRFANOS

Ubicación: Calle Monseñor Salvatierra, entre René Moreno e Independencia.

Construida para el orfanato por Don José Mercado Aguado. Lleva el mismo nombre del filántropo cruceño, ya que fue edificada gracias a su generosidad. Su hijo, Nemesio Mercado, delego la obra al padre Daniel Rivero, quien fue más tarde obispo, apoyando en la concretización de esta edificación. El asilo es también denominado instituto y lo administran los padres de La Salle, desde 1949. En 1894 se encargó el diseño de la escuela al ingeniero Domingo Ofreddi de la ciudad de Salta (Argentina). El edificio es de diseño ecléctico y presenta una solución clasicista austera. Desde un principio funcionó la escuela para los huérfanos (en su fachada se lee Escuela de Artes y Oficios). Con la llegada de los hermanos de La Salle, se hizo el colegio que, posteriormente, se trasladaría al segundo anillo y se quedaría con el nombre de Arzobispo Daniel Rivero (antes llamado Ovidio Barbero). El fin era atender a los huérfanos y estudiantes externos. Por la buena acústica, desde 2004, la Capilla es una de las sedes del Festival Internacional de Música Renacentista y Barroca Americana Misiones de Chiquitos.

TEMPLO
NUESTRA SEÑORA DE LA MERCED

Ubicación: Calle España, esquina Ayacucho **Misa:** Lunes a Sábados: 7:00 / 19:00 Domingos: 7:00 / 9:00 / 11:00 / 19:00 **Atención:** Lunes a Viernes: 8:30 a 12:00 / 14:30 a 18:00 Sábados: 9:00 a 12:00

El templo perteneció al antiguo convento de los Mercedarios, fundado por el Fray Diego de Torres, a finales del siglo XVI. Fue incendiado en 1817, como reacción local al apoyo de los Mercedarios y por la causa de la Independencia de Bolivia. El templo maderero antiguo, que fue reemplazado por el actual de arquitectura neogótica, fue bendecido solemnemente por el obispo local monseñor Santistevan. Desde 1981 hasta 1985 el jesuita Francisco Flores reparó el templo y en la restauración se decidió retirar el revoque y dejar el ladrillo visto mostrando la calidad artesanal de sus detalles, tanto interiores como exteriores. Desde 1994 hasta 1996 el jesuita Javier Sierra restauró el claustro y las dependencias parroquiales. Su gran nave es cubierta por la única bóveda ojival de la ciudad, que genera un espacio de jerarquía, gracias a los lucernarios que la iluminan lateralmente.

IGLESIA
LA MANSIÓN

Ubicación: Calle Monseñor Salvatierra # 435 **Atención:** Lunes a Jueves: 8:30 a 12:30 / 14:30 a 18:30 Viernes: 8:30 a 17:00 **Misa:** Lunes a Sábados: 6:00 Martes y Jueves: 18:30 Viernes: 11.30 / 17:30 Domingos: 7:00 / 10:00 / 19:00

La Mansión, cuyo nombre completo es Centro Carismático Católico de Evangelización, inicia sus actividades en 1973, con los padre estadounidenses Crisóstomo Geraets y Daniel Roach de la Orden de Predicadores. Ante el aumento de los feligreses se construyó el primer pahuichi de forma rústica, con capacidad para 600 fieles. Luego, se edificaron otros seis pahuichis hasta que, en 1984, en base al proyecto de la arquitecta Mary Gladys 'Gugui' Roda, se inicia la gran estructura de 2.117 metros, concluida en 1987; con capacidad para 4.800 feligreses sentados. Se utilizaron materiales tradicionales como la madera, sobre todo tacuara en los techos y asientos. Su carácter arquitectónico le da un atractivo singular, sumado a su particular manera de realizar las celebraciones eucarísticas.

IGLESIA MISIONAL

SAN OSCAR ROMERO Y SANTA MÓNICA

Ubicación: Plan 3.000 (Plaza El Mechero)
Atención: Lunes a viernes: 8:30 a 12:00 / 15:00 a 18:00

ph: GAD SCZ

Es la primera iglesia de estilo jesuítico que se construye en la ciudad de Santa Cruz de la Sierra. Es similar en dimensiones y diseño a la iglesia de la localidad de San Javier, aunque también se rescatan elementos del barroco y misionales de otros templos de la Chiquitania. Se inició su construcción en 2010 y se inauguró en 2016, cuando ya era arzobispo el monseñor Sergio Gualberti. Esta capilla pertenece a la parroquia Hombres Nuevos (Arquidiócesis de Santa Cruz de la Sierra). En su interior se pueden apreciar 14 columnas de madera, de 46 metros de largo, que decoran el ambiente; creando tres naves, una principal y dos laterales. Estas columnas sostienen la estructura de la cubierta, sin necesidad de clavos. Las pilastras fueron talladas en Concepción, así como el diseño de la pintura plasmada en sus paredes. El trabajo estuvo a cargo de artistas de este municipio, que lograron replicar el arte jesuítico de la Chiquitania. En el ingreso se encuentra un campanario, que también tiene características barrocas y hay un órgano del siglo XIX y las estaciones de vía crucis talladas en madera. Este templo fue uno de los escenarios del Festival Internacional de Música Barroca y Renacentista Americana Misiones de Chiquitos. Es la principal iglesia de la populosa zona del Plan 3.000.

ALTAR PAPAL

Ubicación: Av. Monseñor Rivero, esq. 2do anillo (Plaza de las Banderas)

ph: CNN

El Altar Papal lo construyó el Municipio cruceño para la segunda visita del papa en Bolivia. Desde allí, el 9 de julio de 2015, el papa Francisco I ofició la misa ante el pueblo cruceño. Tiene una arquitectura inspirada en el estilo misional chiquitano y construida con columnas labradas por artesanos de Concepción. Es un altar revestido en mica y con detalles propios de las antiguas misiones jesuíticas. La gran estructura maderera de tejado, a dos aguas, de 14 metros de altura en la cumbrera, se levanta sobre un podio de 200 metros cuadrados. Desde allí, se ofició la misa papal ante más de un millón de feligreses y esa concentración fue emitida por televisoras internacionales, como CNN. El altar está ubicado a los pies del monumento al Cristo Redentor. Es jerarquizado por la plaza de las Banderas (conjunto paisajístico). Este espacio, que recuerda la visita del sumo pontífice a Santa Cruz de la Sierra, es utilizado desde entonces para actividades culturales y religiosas. La Ley Municipal Autonómica N° 106 lo declaró Patrimonio Cultural, Arquitectónico, Monumental e Histórico Municipal.

ph: CNN

PLAZUELA DEL
CEMENTERIO

Ubicación: Intersección de la Av. Argomosa, con las calles Arenales, Barrón y Bolívar

ph: GAD SCZ

Plaza rodeada de árboles tradicionales de la región, como ser los Toborochis, que en los meses de agosto y septiembre florecen y se ven hermosos. Desde esta plaza se puede observar al frente el cementerio general de la ciudad. Es una zona muy transitada por vehículos y mucho transporte público. Es un punto de descanso cuando se está de pasada hacia el centro de la ciudad, donde, en los días de calor, podés refrescarte con un delicioso raspadillo, hielo troceado o rallado con jarabe de sabores variados. También, podés encontrar otros refrescos tradicionales como somó, mocochinchi, entre otros. Cerca de la plaza hay una variedad de tiendas de flores y regalos y justo a lado del cementerio general se encuentra el "Paseo de las Flores", donde podés comprar flores naturales en cualquier época del año.

PLAZA DE
AVIONES

Ubicación: Av. Santos Dumont, 2do Anillo, Aeropuerto El Trompillo

ph: GAD SCZ

En la acera oeste del aeropuerto El Trompillo, cerca del 2do anillo, la Fuerza Aérea Boliviana ha dispuesto un espacio para los amantes de las Aeronaves. En la Plaza de Aviones se pueden ver diversos aeroplanos desde helicopteros, aviones de combate hasta aviones comerciales, todos de larga data utilizados por la misma FAB.

PASEO DE

NOTABLES

CEMENTERIO GENERAL DE SANTA CRUZ

Ubicación: Avenida Viedma y rodeado por las calles Arenales,

ph: GAD SCZ

Darse una vuelta por los pasillos del Cementerio General de Santa Cruz de la Sierra, es pasear por la historia, entre notables que han dejado su huella en la política, la cultura o el deporte. Melchor Pinto Parada, Andrés Ibáñez, Noel Kempff Mercado, "Roly" Aguilera, Willy Bendeck, Hugo Banzer Suárez y el "Camba Sota", son algunos de los nombres famosos que saltan a la vista desde su última morada, no solamente por la majestuosidad de sus mausoleos, sino por lo que ellos hicieron en vida. Sin duda, se trata de un lugar que guarda mucha historia que merece ser conocida y, sobre todo, valorado por la sociedad actual y por las futuras generaciones. Por esta razón, en la gestión 2023, el Gobierno Municipal de Santa Cruz de la Sierra, impulsó el proyecto denominado "Paseo de Notables", con el objetivo de recordar que dejaron su huella en la comunidad cruceña y nacional. Es un recorrido turístico y patrimonial que invita a los visitantes a conocer de primera mano los mausoleos de las personalidades cruceñas. En cada mausoleo o sepultura fue colocada una tarjeta con el código QR para que el visitante, escanee y mediante su celular sea direccionado a un sitio web, donde encontrará información detallada sobre la vida y obra de cada personaje. Los visitantes también tendrán la información en su equipo móvil de quienes están sepultados en los más de 50 pasillos de este cementerio. Todo será direccionado mediante Google Maps. Para que los visitantes tengan un panorama general del Paseo de Notables, en el ingreso principal existen mapas, que pueden guiar a visitantes que llegan por primera vez. En cuanto a su historia, el Cementerio General es el cementerio oficial más antiguo de la ciudad, se destaca por acoger las sepulturas de las primeras familias cruceñas, así como por la belleza de sus mausoleos, paseos y senderos. Fue creado en 1826 y empezó a ser utilizado en 1834. Fue declarado Patrimonio Histórico de Santa Cruz de la Sierra en 2013.

ph: GAM SCZ

PLAZUELA CALLEJAS

Ubicación: Entre las calles Warnes y Cobija

ph: GAD SCZ

La plazuela "Callejas", denominada como el "Centro de América del Sur", por arquitectos, filósofos, poetas y escultores de la Escuela de Arquitectura de la Universidad Católica del Valparaíso, Chile.

ph: Actualidad SCZ

El grupo realizó una investigación, allá por los años 60, donde recorrieron Sudamérica de borde a borde y concluyeron que el punto medio se ubica en este tradicional pase cruceño. Este centro recreacional es un legado de la familia Callejas, Froilán Callejas, un patriarca que construyó su casa quinta con un pozo de agua y que a lo largo de los años se fue consagrado como el lugar de encuentro de los carnavaleros que era anunciado por el pregonero, un camba a caballo. Actualmente es un centro referencial e histórico de Santa Cruz y continúa siendo el lugar de encuentro de grupos de amigos y comparsas que celebran el carnaval. Asimismo, este espacio es enriquecido por una variedad de actividades culturales y artesanales que rescatan las tradiciones y el espíritu hospitalario de la ciudad. Este lugar ha sido remodelado recientemente. Se han colocado banderillas de orientación y distancias a ciudades del mundo, que se prestan para hacer de telón de fondo. Además, esta antigua plazuela tiene una Cruz, que, aunque no tiene capilla, cada 3 de mayo se reza el rosario y la novena. La plazuela Callejas y sus alrededores, engloba tradición e historia y cobija, quizás a uno de los barrios de antaño expuesto a la modernidad, que todavía queda en el centro de la ciudad; trayendo mucha nostalgia para aquellas personas que han visto los cambios en la ciudad, pues resume la Santa Cruz de antaño, con su arquitectura colonial y las pulperías del siglo pasado. En este rinconcito, aún se puede respirar tranquilidad y recargar energías en una de sus bancas mientras se continua con el viaje.

PLAZUELA
BLACUTT

Ubicación: Intersección de la Av. Velarde, con las calles C. H. de Salazar, René Moreno y Soliz de Olguín

ph: GAD SCZ

Plaza Blacutt, más conocida como "La Plazuela Blacutt", se encuentra en el centro sur de la ciudad, a sólo tres cuadras del estadio Ramón Tahuichi Aguilera. Es un punto de encuentro para las familias y amigos que disfrutan de este espacio con áreas verdes rodeado de árboles. Para los más pequeños, hay opciones para alquilar, por unos minutos, autitos eléctricos en los que pueden pasear por la plaza y divertirse en familia. Se encuentra rodeado por diferentes opciones de restaurantes y supermercados. Por las noches está rodeado de puestos de comida callejera y los fines de semana se programan ferias de artesanos y emprendedores en las que se puede encontrar cosas únicas a un buen precio.

PLAZUELA DEL
ESTUDIANTE

Ubicación: Intersección de la Av. Monseñor Rivero, Busch y Cañoto

ph: GAD SCZ

Conocida como la "Plazuela del Estudiante", alberga al mayor centro de lectura de la ciudad, la primera Biblioteca Municipal de Santa Cruz. Tiene un espacio amplio donde se realizan conciertos y en los últimos años, se ha convertido en un punto de encuentro de concentraciones culturales, cívicas, deportivas y un espacio para diferentes tipos de ferias y exposiciones. Se encuentra rodeado de grandes árboles que dan sombra a sus visitantes.Se encuentra prácticamente cerca a la Monseñor, un boulevard con opciones gastronómicas y cafecitos con horneados típicos. En días de calor, se sabe ver los tradicionales raspadillos, hielo troceado o rallado con jarabe de sabores variados, que hacen pasar la sed. Por las noches, si tenés hambre, podés encontrar en sus alrededores puestos de comida callejera.

PARQUE ARENAL

EL PRIMER PARQUE URBANO DE LA CIUDAD

Ubicación: Calle Beni, esq. Caballero



ph: GAD SCZ

El Parque “El Arenal”, enclavado hoy en pleno centro de la ciudad, representa una remembranza de la Santa Cruz de antaño, pues la laguna natural que se encuentra en su parte central, siempre ha existido.

Según cuentan varios historiadores cruceños, por la época de la fundación de Santa Cruz, los vecinos la conocieron como “Los Aguados del Piton”, por la gran cantidad de plantas que había en los alrededores, cambiando posteriormente de nombre al actual, por las grandes cantidades de arena que la rodeaban. Sus aguas estaban servidas por la corriente, casi permanente, que escurría de la hoyada que manaba de forma continua y formaba un pequeño arroyo que bordeaba la ciudad. Copaba parte del primer anillo la actual avenida Uruguay, hasta la altura de Los Cusis, hoy calle Beni y Uruguay. Una parte seguía hacia el Tao y la otra hacia el Sur y hallaba sus estanques en la vieja laguna de El Arenal, la cual, además de recibir las corrientes pluviales, sus rebalses eran vertidos hacia la zona del naciente, llevando de esta manera los bajíos del llamado Pozo grande, que después se lo llamó Los Pozos.

Datos del siglo XIX, muestran que era un abastecimiento de agua cercano a la ciudad para el consumo de animales domésticos y pascana de los viajeros que llegaban del norte; un lugar de recreo donde los niños acudían a nadar y pescar y las mujeres a lavar ropa. Allí también abrevaban los sedientos bueyes, caballos y mulas que aprovisionaban la ciudad desde las provincias vecinas. La construcción del parque El Arenal se hizo en diferentes etapas. Surgió como parque en 1965; en el lugar se instalaron luz eléctrica, agua potable y se plantaron árboles de varias especies, lo que dio una mejor imagen al lugar. En el año 1967, se empezó la obra de ingeniería y regulación hidráulica impulsada por el ilustre ingeniero Roly Aguilera.

ph: GAD SCZ

ph: GAD SCZ

El mural que está en la isla, titulada “La Gesta del Oriente Boliviano”, fue realizado por el artista Lorgio Vaca, entre los años 1968 y 1971. Es un gran relieve cerámico policromado y vidriado que narra la epopeya de los Llanos Orientales, desde la época anterior a la conquista hasta nuestros días. Fue durante esta etapa que se incorporó el museo de la isla y un restaurante que le dieron un movimiento moderno al parque. Hasta principios de los años 90, el parque El Arenal aún mantenía sus sirenas y los visitantes podían dar vueltas en botes pequeños que permitían navegar dentro de la laguna. Actualmente, el parque El Arenal es un paseo popular y tradicional de la ciudad. Podés conocer el mural restaurado del artista Lorgio Vaca y disfrutar de la vegetación que rodea el parque mientras se pasea.

CAMBÓDROMO

Ubicación: Av. Mutualista, entre 4to y 8vo anillo

ph: GAD SCZ

Uno de los mayores espacios peatonales al aire libre de Santa Cruz y el país, en donde podrás encontrar muchas actividades para explorar y disfrutar:

- ***Vivir la experiencia del "Gran Corso Cruceño".***

Una de las principales finalidades para construir el "Cambódromo" fue para ser escenario del corso, conocida también como la "Fiesta Grande los Cruceños" y tener un lugar más organizado para vivir este gran jolgorio. Si tenés la oportunidad, no te perdás esta gran fiesta, siendo todo un espectáculo lleno de alegría, brillo y música.

- ***Asistir a eventos y festivales culturales, folcloricos, desfiles cívicos, entre otros.***

Uno de los aspectos destacados del Cambódromo es la oportunidad de presenciar los eventos culturales, cívicos, ferias, festivales de danzas, entradas folclóricas, paradas militares, ferias interprovinciales, conciertos etc., que muestran el rico patrimonio cultural del departamento y del país.

- ***Disfrutar de la música y actuaciones en vivo***

El Cambódromo suele albergar conciertos y actuaciones de música en vivo. Si sos fanático de la música tradicional o prefieres los

géneros más contemporáneos, seguramente encontrarás algo que se adapte a tus gustos. Estas actividades se realizan de acuerdo a un calendario y cronograma previamente planificado.

- ***Practicar deporte y pasar tiempo en familia***

El Cambódromo se ha convertido en un espacio donde las personas se dan cita para hacer actividades físicas como correr o manejar bicicleta. Asimismo, las familias aprovechan este gran espacio para pasar tiempo en familia, siendo los más pequeños los que más disfrutan, haciendo uso de los parques infantiles. El Cambódromo, tiene un significado histórico, ya que su construcción tuvo la finalidad de conmemorar el patrimonio cultural de la ciudad y promover la participación comunitaria. El nombre "Cambódromo" deriva de la combinación de "Camboya" y "desfile" (desfile en español), reflejando el ambiente animado y el espíritu festivo de Santa Cruz. Se inauguró el 1 de marzo de 2014. Cuenta con más de 40 hectáreas, que se extienden sobre cuatro kilometros situados entre el cuarto y octavo anillo de la ciudad. Tiene una capacidad para 30.000 personas.



PAURITO

CAPITAL DEPARTAMENTAL DEL SOMBRERO DE SAO

Ubicación: Distrito 14

ph: Paurito Te Espera

La tradicional localidad de Paurito es un pequeño pueblo del departamento de Santa Cruz que se encuentra ubicado al suroeste de la ciudad, distante a 30 kilómetros. Es un lugar tranquilo, pacífico y hospitalario, haciendo que quienes visiten este lugar quieran quedarse. Fue fundado el 1 de febrero de 1621 y fue poblado por familias españolas que venían a refugiarse del asedio de los chiriguanos. Fue declarada en octubre del 2018 por la Asamblea Legislativa Departamental de Santa Cruz, como la Capital Departamental del Sombrero de Saó, considerando la elevada y variada producción artesanal que elaboran sus pobladores mediante el aprovechamiento del Sao, y la importancia cultural y representativa que simboliza para los cruceños el "Sombrero 'e Sao" elaborado por artesanos cruceños. Esta localidad tiene actividades culturales y religiosas muy arraigadas en su población. Entre ellas está la festividad de "San Pantaleón", que se celebra cada 27 de julio. Cuenta la historia, que Pantaleón fue un médico durante el imperio romano, que convertido al cristianismo profesó la fe y por defender sus creencias muere decapitado derramando su sangre amarrado a un árbol de olivo, el cual se dice floreció al instante. Se le da el rango de Santo, denominándose "San Pantaleón", el Santo médico. Una de las familias que introduce la celebración en Paurito en el siglo XIX, es la familia Domínguez, una de las familias más antiguas del lugar y devotos a este santo, por lo que hacían la fiesta conmemorativa con la respectiva novena y misa en su día. En la década de los 70, el Santo fue llevado al templo del pueblo y posteriormente en los años 80, a iniciativa del Comité Cívico de Paurito se lo llevó al hospital, donde se encuentra hasta el día de hoy. Actualmente, el hospital de Paurito tiene el nombre de "Centro de Salud Municipal San Pantaleón" y su festividad es celebrada en todo el pueblo, teniéndolo como su santo patrono. Por lo tanto, la celebración de San Pantaleón en Paurito es parte de la cultura de los pueblos cruceños. Otra de sus festividades es la de su patrona, "Nuestra Señora de la Candelaria", cuya celebración es cada 2 de febrero. Se rememora la presentación de Jesús en el Templo de Jerusalén después de su nacimiento y la purificación de María. También, dependiendo de la época del año y sujeta a un cronograma, se realizan otras actividades como ferias turísticas, de emprendimiento, donde se muestran obras de arte de los artesanos, mayormente realizados con la planta de sao. Por último, tenés que darte una vuelta por su plaza principal, admirar su iglesia y de retorno a la ciudad, comprar pan casero y unos deliciosos horneados típicos.

MONTERO HOYOS

EL DISTRITO MÁS ANTIGUO DE SANTA CRUZ DE LA SIERRA

Ubicación: Distrito 15, a 48 kilómetros de la ciudad de Santa Cruz

Montero Hoyos fue fundada el 25 de marzo de 1938, teniendo un significado histórico relevante para el departamento de Santa Cruz, porque dentro de la jurisdicción del distrito municipal de Montero Hoyos, se encuentra la comunidad San Lorenzo Real de la Barranca, que fue el lugar de la segunda fundación de Santa Cruz de la Sierra, por Suarez de Figueroa y Soliz de Olguín, un 13 de septiembre de 1590. Entre los lugares turísticos que tiene, se encuentra la plaza principal, la iglesia San Miguel de Arcángel, la mencionada comunidad San Lorenzo de la Barranca (donde fue la segunda traslación de Santa Cruz) y el río Grande, en donde los visitantes pueden bañarse o realizar pesca deportiva. Una de sus actividades turísticas más importantes, es el aniversario del municipio, que se celebra cada 25 de marzo. Las actividades que se realizan son ferias productivas, de salud, desfiles cívicos, eventos deportivos, carreras pedestres y una verbena popular. Cabe destacar que este distrito es un lugar de recreación y descanso para las personas que lo visitan desde otros lugares. En cuanto a su actividad económica, su gente se dedica especialmente a la producción de hortalizas, yuca, caña, soya y productos como: panes y quesillos, así que si estás de visita por estos lados, podés llevarte para degustar pan casero, horneados típicos, manjar blanco, quesillo, chicha de maíz, que son productos que podés encontrar a diario. Este distrito a la actualidad acoge a 15.000 habitantes y se encuentra a 48 kilómetros de la ciudad capital y a 5 kilómetros de la localidad de Pailas. Tienen como vecinos a Cotoca, Warnes y Pailas.

COMUNIDAD TIPOY

Ubicación: Carretera Paurito, Km. 17.9

Uno de los pueblos más antiguos de Santa Cruz ubicado sobre la carretera que conduce a Paurito. Se fundo en el 1766 y es poblada por etnias guaraníes. Su nombre, Tipoy, hace referencia a la vestimenta femenina propia de los guaraníes De manera jocosa, se dice que en este pueblo aún se baila al ritmo de la tamborita y la comida se come con cuchara de palo.

EL PALMAR DEL ORATORIO

RINCONCITO DE LA SANTA CRUZ DE ANTAÑO

Ubicación: Distrito 13

Si querés recordar a la Santa Cruz de antaño, tenés que visitar Palmar del Oratorio que se encuentre ubicado al sur de la ciudad. En este lugar, podrás conocer una antigua casona que data de hace 150 años, con sus ventanales y los horcones que caracterizan a las tradicionales viviendas de Santa Cruz. Según cuentan, es una de las zonas más antiguas de Santa Cruz, de aproximadamente unos 200 años de existencia. Fue llamado "Palmar del Oratorio" porque en la época de la colonia, los españoles llegaban al lugar para orar.

FESTIVAL DE MÚSICA RENACENTISTA Y BARROCA AMERICANA

"MISIONES DE CHIQUITOS"

Ubicación: Santa Cruz de la Sierra, Porongo,

ph: GAD SCZ

El Festival de Música Renacentista y Barroca Americana "Misiones de Chiquitos" es un evento cultural de gran importancia que se celebra anualmente en las misiones jesuíticas de Chiquitos en Bolivia. Este festival reune a músicos y artistas de renombre internacional que interpretan música barroca y renacentista en un marco histórico y arquitectónico único. El origen de este festival se remonta al año 1996, cuando un grupo de músicos bolivianos decidió rendir homenaje a la música barroca que se había preservado en las misiones jesuíticas de Chiquitos. Desde entonces, el festival ha ido creciendo en popularidad y prestigio, atrayendo a artistas de todo el mundo y convirtiéndose en uno de los eventos culturales más importantes de América Latina. Desde sus inicios en el año 1966 a la actualidad se van celebran varias versiones, siendo la de 2024 la XIV versión. Cada año, el festival presenta una variada programación de conciertos, conferencias, talleres y actividades culturales, que tienen lugar en las impresionantes iglesias barrocas de las misiones jesuíticas de

Chiquitos. Los visitantes tienen la oportunidad de disfrutar de la música de compositores como Vivaldi, Bach, Handel y Telemann, interpretada por músicos de renombre internacional y por las orquestas locales. Además de la música, el festival también ofrece la posibilidad de conocer la historia y la arquitectura de las misiones jesuíticas de Chiquitos, que fueron declaradas Patrimonio de la Humanidad por la UNESCO en 1996. Estas misiones, construidas en el siglo XVII, son un ejemplo único de la fusión entre la cultura europea y la indígena, y constituyen un legado invaluable de la historia colonial de América Latina. El Festival de Música Renacentista y Barroca Americana "Misiones de Chiquitos" es una experiencia cultural inolvidable que combina la música, la historia y la arquitectura en un entorno mágico y cautivador. Una visita a este festival es una oportunidad única para sumergirse en la riqueza cultural de América Latina y para disfrutar de la belleza de las misiones jesuíticas de Chiquitos.

ph: GAD SCZ

ph: GAD SCZ

ph: GAD SCZ

TURISMO DE NATURALEZA

Santa Cruz de la Sierra

ph: GAD SCZ

PARQUES URBANOS

En los últimos años, por iniciativa del Municipio de Santa Cruz de la Sierra, se han recuperado espacios públicos convirtiéndolos en zonas verdes de esparcimiento que incentivan el contacto con la naturaleza, pasar tiempo en familia, realizar actividades recreativas y ejercicio físico. Estos parques cuentan con paseos peatonales, canchas de voleibol de playa, parques infantiles, churrasqueras, ciclovías y canchas deportivas. Además, se encuentran rodeados de diferentes especies de árboles nativos, entre mangos, achachairúces, motoyoeses, totaises y otros; los cuales han sido sometidos a un tratamiento para su embellecimiento y proporcionan una gran sombra refrescando a los visitantes, que toman un descanso en algunas de sus bancas. En su interior también hay disponible baños públicos y tiendas donde podés comprar alguna merienda y bebida para saciar el hambre y la sed. Por otro lado, en estos parques generalmente se organizan diferentes tipos de ferias, festivales, y son puntos de partida y llegada para las carreras pedestres que se organizan a lo largo del año en la ciudad, convirtiéndose en puntos de fiestas deportivas. Los parques se encuentran a disposición de la ciudadanía y su ingreso es completamente libre.

LOS MANGALES I

Ubicación: Intersección de la avenida El Palmar (radial 19), con las calles Ricardo Arias, Plácido Sánchez

ph: GAD SCZ

LOS MANGALES II

Ubicación: Intersección de la avenida Beni, con las calles Lucía Mercado y Mercedes Saucedo

ph: GAD SCZ

LOS MANGALES III

Ubicación: Intersección de las avenidas Roca y Coronado, Roque Aguilera (tercer anillo interno) y José Estenssoro (tercer anillo externo)

ph: GAD SCZ

LOS MANGALES "PIRAI"

Ubicación: Intersección de la avenida Piraí, con las calles 1 y 4 Hermanos (pasando el cuarto anillo)

ph: GAD SCZ

PARQUE AUTÓNOMICO "4 DE MAYO"

Ubicación: Cuarto anillo entre las avenidas Roca y Coronado y Hernando Sanabria

ph: GAD SCZ

PARQUE URBANO

Ubicación: Intersección de la Av. Santa Cruz, con las calles Mariano Arrien, Tte. Mamerto Cuéllar y la Av. Argentina.

ph: GAD SCZ

ph: GAD SCZ

¿Querés relajarte, hacer deporte o simplemente pasear? Visitá el Parque Urbano, un lugar que con sus amplias áreas verdes, senderos arbolados es un punto de descanso en medio del bullicio urbano. Es considerado pulmón de la ciudad debido a la gran variedad de especies de árboles y arbustos. Cuenta con 2.300 árboles de 113 especies y 600 arbustos.

ph: GAD SCZ

Ofrece un agradable espacio para realizar actividades de entretenimiento y deportivas. Cuenta con un anfiteatro, ciclovías, veredas pavimentadas y algunos senderos de tierra. Está abierto a toda hora, pero en la tarde y la noche aumenta la concurrencia y se puede observar a personas haciendo alguna actividad física y otros pedaleando en sus bicicletas tanto en el interior como en la parte externa. En la zona del anfiteatro, lo utilizan a manera de pista de patinaje; "skaters" de todas las edades muestran sus destrezas y habilidades para volar sobre las tablas.

ph: GAD SCZ

Las familias van con sus niños para disfrutar de los parques infantiles y los vecinos aprovechan el espacio para pasear a sus mascotas. También, hay campeonatos de futsal y de básquet.

En el acceso del lado oeste se encuentra el Monumento Cumbre de las Américas, un monumento formado por dos grandes torres de ladrillo. Cerca de este espacio, grupos de jóvenes acuden para ensayar y practicar sus bailes, que van de distintos géneros, entre hip-hop y folclóricos, mientras que los grupos de ballets practican las coreografías de sus danzas, cautivando a quienes visitan el parque. Además, en el parque se realizan frecuentemente eventos culturales, conciertos al aire libre y ferias gastronómicas, por lo que siempre hay algo interesante que ver o hacer. En la parte exterior del ingreso principal se encuentran pequeñas cabañas de motacú, donde se venden refrescos típicos de la región, como agua de coco, somó, chicha, mocochinchi y copoazú.

Anteriormente, el parque perteneció a la Empresa Nacional de Ferrocarriles del Estado, donde se albergaba una pequeña estación para el uso de pasajeros con destino a Brasil o Argentina. En resumen, el Parque Urbano de Santa Cruz es un lugar único que combina la naturaleza, deporte, cultura y diversión en un solo lugar. ¡No te lo puedes perder!

UN LUGAR PARA APRENDER Y DISFRUTAR DE LA NATURALEZA

Desde el momento en que ingresés al Jardín Botánico, no importa donde dirijás la mirada, siempre te encontrarás en contacto directo con la naturaleza y sobre todo con algo nuevo que aprender. Aquí podrás apreciar una gran diversidad de vegetación selvática y aves. El lugar está dedicado a la investigación científica, ejecuta programas permanentes de investigación y educación para la promoción de una cultura ambiental en distintos niveles de la población, orientados a la preservación, restauración, uso sostenible de las plantas y del medioambiente en general y conservación de la flora nativa. También ofrece paseos guiados, un mirador, orquidiario, rutas para recorrerlo a pie o en bicicleta, áreas de camping, churrasqueras, un auditorio, parques infantiles e incluso podrás comprar plantines y abonos orgánicos. Iniciando el paseo en el jardín, podés seguir los senderos trazados, las colecciones de tajibos, toborochis, bromelias, cactus, rosas del desierto, y plantas frutales nativas, como el guapurú, guapomó, cupesí y achachairú, entre otros, te van embarcando en un viaje de aprendizaje y disfrute de la naturaleza. Para ello, cada nuevo espacio, que alberga una colección específica, cuenta con la señalética respectiva donde se explica sobre la especie y el número de muestras con las que se cuenta en el jardín.

Dentro de las diferentes colecciones que hay en el Jardín Botánico, las orquídeas tienen un lugar especial: el orquidiario, un ambiente cerrado que te traslada a un hermoso paisaje natural rodeado de orquídeas, plantas nativas, un río que atraviesa todo el espacio, y una pequeña cascada. Este lugar privilegiado se debe en gran parte a que cuentan entre sus muestras con "La Bailarina", una variedad nativa que fue declarada la flor símbolo de los festejos del Bicentenario y de los 450 años de la fundación de la ciudad por el Concejo Municipal de Santa Cruz de la Sierra. Cada una de las especies que están en las distintas colecciones ha sido seleccionada por ciertas particularidades, como su rareza, su distribución restringida, su grado de vulnerabilidad o si está en cierto peligro de extinción. Después están las especies de cactus que son endémicas, es decir que sólo existen en ciertas zonas de Bolivia y su reproducción es muy restringida.

Es por eso que todas estas especies que están en las colecciones y que tienen cierto grado de vulnerabilidad o de rareza están sometidas a un programa de investigación y reproducción. En cuanto a sus características, el Jardín Botánico tiene una extensión de 217 hectáreas, en la que, con un solo recorrido, tendrás experiencia de conocer tres de los ecosistemas más representativos del departamento.

Su propósito es conservar y exhibir la gran diversidad florística vegetal y animal de Santa Cruz, pues se proyecta como una referencia ecológica única. Posee más de 500 especies de flora, doce especies de mamíferos y más de 200 especies de aves. Sus 217 hectáreas se dividen en dos áreas: la de conservación y la de enriquecimiento. En el área de conservación, que ocupa casi un 90% de la superficie, convergen tres unidades vegetales: el bosque chiquitano, el bosque subtropical y el bosque chaqueño; en tanto que en el área de enriquecimiento se encuentran los jardines, viveros, herbarios, laboratorios, parque infantil, la laguna, el orquidiario, el cactario y las áreas de camping y esparcimiento.

Entre las recomendaciones para visitar el lugar:

- Podés llevar agua y comida, y hacer tipo picnic. Siempre con el cuidado de no ensuciar el lugar
- Usa protector solar y repelente para insectos
- Podés llevar tu mascota, siempre y cuando utilices una correa. Recordá que es un espacio abierto con diversidad de animales silvestres.

En relación a su historia, el jardín botánico fue creado el 25 de septiembre de 1985 por el profesor boliviano Noel Kempff Mercado, con la intención de conservar las plantas de los ecosistemas acuáticos bolivianos y los de la región de Santa Cruz de la Sierra. Sin duda alguna, el Jardín Botánico es un lugar que tenés que visitar si querés estar en contacto con la naturaleza que caracteriza a esta zona del país.

CURICHI LA MADRE

TESORO NATURAL DE LA CIUDAD

Ubicación: Av. Piraí entre cuarto y quinto anillo.
Atención: Lunes a viernes 08:00 a 16:00 horas

ph: GAD SCZ

ph: Área protegida Curichi la Madre

Si estás en la ciudad de Santa Cruz, tenés que sumergirte en la maravillosa biodiversidad del Parque Urbano de Preservación Ecológica "Curichi la Madre". Es un espacio verde único que se encuentra dentro de la ciudad y donde, con visitas guiadas, podés recorrer sus senderos exuberantes y conectar con la fauna y flora que la rodea. Tiene tres senderos habilitados, donde se puede encontrar diversas especies de plantas y árboles características de esta zona oriental, como palosanto, curupaú, mara y tacuara. También podés encontrar 70 metros de puentes colgantes y un espectacular observatorio con mirador y unas escaleras en forma de caracol. Lo increíble de este lugar es su ubicación, ya que ni siquiera tenés que salir de la ciudad para visitarlo.

ph: Área protegida Curichi la Madre

En sus 49 hectáreas, refugia a más de 225 especies de fauna silvestre y 147 especies de flora, siendo el hábitat natural de osos perezosos, capibaras, monos, ardillas, tortugas, jochis, aves y serpientes entre otras especies. Cuando visites el parque, no podrás ver todas las especies, ya que dependerá de la temporada del año y la hora en que estés visitando el parque, pero con suerte podrás avistar una media de cinco especies, entre animales y aves. Es considerado entre los 80 humedales urbanos más completos del planeta. está compuesto por cinco curichis o cuerpos de agua, dos son estacionales y tres permanentes.

ph: GAD SCZ

Su ubicación en plena urbe cruceña lo convierte en un sitio vital para la preservación y regulación del ecosistema de la ciudad, ayudando a controlar las temperaturas, amortiguando los vientos y purificando el aire. Por otro lado, como se había descrito al inicio de estas líneas, en sus senderos podés encontrarte con plantas a las que debes evitar tomar contacto. En varias regiones de Santa Cruz, crece una planta llamada “ortiga”, que aquí se la conoce como “pica pica”, es una planta que más allá de sus propiedades curativas es de cuidado. Hay que evitar que sus hojas tomen contacto con la piel, pues generan un ardor doloroso y de allí también la razón de su nombre: ‘pica pica’. Es una especie endémica de la zona. Otra planta de cuidado y que la podés encontrar con frecuencia en el Curichi La Madre es el “palo santo”, que puede llegar a crecer hasta los 12 metros. A diferencia de la ortiga, el peligro no está en sus hojas, sino en las hormigas que conviven en su corteza.

ph: Área protegida Curichi la Madre

Por lo tanto, te dejamos las siguientes recomendaciones para que visités este maravilloso punto verde de la ciudad:

- Tener cuidado de no tocar o apoyarte en una de estas plantas (palo santo y pica pica).

- Usa zapatos cómodos; blusa, polera o camisa con manga larga y pantalón largo.

- No olvidar gafas de sol y un buen repelente para los mosquitos.

- También se recomienda por ningún concepto, arrojar o dejar alimentos a los animales para no alterar su modo de vida.

Ahora sí, disfrutá de la paz, la belleza y el aprendizaje que puede brindarte la naturaleza, sin afectarla en el “Curichi La Madre”.

PARQUE URBANO

LAGUNA GUAPILO

Ubicación: Av. Virgen de Cotoca noveno anillo
Atención: Lunes a domingo: 06:00 a 22:00

ph: Carlojvlog

Diseñado para regular el drenaje pluvial y controlar inundaciones en la zona este de la ciudad de Santa Cruz de la Sierra, el parque "Laguna Guapilo" se encuentra a 8,9 km al este de la ciudad de Santa Cruz de la Sierra.Tiene una superficie de 50 Has, que incluye una laguna artificial de 36 Has. y el resto está compuesto por árboles y arbustos. Alrededor de la laguna se pueden observar árboles de cupesí, espino blanco y penoco, que son especies predominantes dentro del área. De igual manera, presenta especies como: tajibo, toborochi, gallito rojo, gallito rosado y algunas plantas herbáceas.

ph: GAM SCZ

Estas características, lo convierten en un hábitat clave que permite el establecimiento de diversas especies de flora y fauna, tanto acuáticas como terrestres residentes y migratorias, incrementando su valor paisajístico, además de contribuir a incrementar la calidad de vida y la práctica de actividades educacionales, recreativas y esparcimiento para los vecinos de la zona y visitantes que llegan al lugar.El parque se encuentra a disposición de la ciudadanía y su ingreso es completamente libre.

ph: Santa cruz experiencia tours

ph: Daniel Alarcón

La Reserva Privada del Patrimonio Natural (RPPN) "Las Garzas" fue constituida en 2005 y se encuentra ubicada en el suroeste de la capital cruceña. Esta reserva destaca por su imponente laguna, que se origina a partir de vertientes naturales en el sector noroeste del área. La creación de "Las Garzas" tuvo como principal objetivo la conservación de los ecosistemas naturales y biodiversidad de la región. Esta reserva abarca una variedad de ecosistemas, incluyendo bosques tropicales, humedales y ríos. Es especialmente conocida por ser un importante hábitat para aves.

ph: Franco Berton

ph: Franco Berton

Además de las garzas, se pueden avistar otras aves como el martinete pescador, garcetas, tangaras, entre muchas otras especies. Entre las actividades que se pueden realizar se incluyen la observación de aves, caminatas guiadas por senderos naturales, paseos en bote por los cuerpos de agua y la fotografía de la naturaleza. La reserva tiene como objetivo principal la conservación de la biodiversidad de la región, en particular de las especies de aves y su hábitat natural. Se realizan esfuerzos de conservación y educación ambiental para promover la protección de este ecosistema único.

ZOOLÓGICO

MUNICIPAL DE SANTA CRUZ DE LA SIERRA

Ubicación: Av. Marcelo Terceros Banzer, tercer anillo externo
Atención: Martes a domingo: 09:00 a 17:00 horas

ph: GAD SCZ

El Zoológico Municipal de Fauna Sudamericana Noel Kempff Mercado es un atractivo turístico único que, a través de sus guías, permite conocer la riqueza faunística que posee; además de llevar a cabo programas educativos para los estudiantes con el fin de informar las especies que existen en el zoológico. En sus casi siete hectáreas, el centro alberga 2.000 animales de 250 especies, entre ellas aves, mamíferos, reptiles, peces y demás animales nativos de Sudamérica. Se encuentra ambientado entre bellos jardines, donde podés conectar con la naturaleza y tener la oportunidad de conocer una extensa biodiversidad de especies autóctonas, considerada como una de las más completas de su género; además, podrás ver 93 tipos de árboles, entre los cuales se destaca el motoyoé, el árbol más viejo de la ciudad, que sobrevivió a todos los avatares del tiempo. Tiene 204 años. El Zoológico está compuesto por cuatro circuitos. El primero comprende las aves en peligro de extinción y el segundo está dividido en dos; acuario y aviario. Luego, se encuentra el área del jaguar, la granja del zoo, las islas de los monos. Por último, están los ambientes del cóndor, las serpientes, lo búhos, las cotorras y los armadillos.

Bolivia es el décimo tercer país con mayor biodiversidad al contar con un patrimonio faunístico avalado por eminentes especialistas del mundo. Una muestra extraordinaria de éste valioso recurso natural se halla en el Zoológico Municipal de Santa Cruz de la Sierra Fauna Sudamericana, institución que materializa los principios de conservación, defensa y estudio de nuestra riqueza faunística. Todo esto convierte al Zoológico Municipal de Santa Cruz de la Sierra, en el más importante del país y de Sudamérica. No dudés en darte un paseo por el zoológico y conocer la gran biodiversidad de fauna y flora que tiene nuestro departamento y el país.

Este es un recinto donde se encuentran diferentes animales de acuerdo a la época del año, dispone de una base sólida para que las especies puedan tomar el sol y el público visitante las pueda observar y un área acuática para facilitar la inmersión de las especies. Allí encontrarás mamíferos como el Lobito de Río, algunos reptiles como caimanes, tortugas y peces como carpas.

Se establecieron dos islas, una de dimensiones más grandes donde se albergan dos especies de monos, los monos araña y los monos cariblanca. Estos animales de hábitos diurnos, son arborícolas, rara vez bajan al suelo. En la isla más pequeña y con menos vegetación, viven los monos capuchinos que son menos sociables y más dominantes que los anteriores, ya que son más solitarios, viven en pequeños grupos o comunidades más reducidas.

Es un recinto enorme con una amplia superficie, la cual está cubierta por una malla. En su interior encontrarás una espesa vegetación y árboles de gran porte; allí podrás caminar por el sendero del aviario y disfrutar de la observación de cerca de 116 especies de aves como: Paraba 7 Colores, Paraba Azul y Amarillo, Bandurria, Socorí, entre otras. En este escenario podrás apreciar y disfrutar de manera natural de las aves en vuelo, el canto de algunas de ellas y su manera de alimentarse o acicalarse.

Consiste en una gruta con secciones o terrarios donde moran la mayoría de las especies de reptiles. Su nombre deriva de la palabra herpetos que significa "Serpiente" o reptil, siendo la herpetología una rama de la zoología que estudia a estos animales. La exhibición muestra serpientes fascinantes como: La Boa Constrictor, la Boa Arborícola, Boa Tornasol, Anaconda Amarilla, tortugas como: Peta Amarilla, Peta del Monte, iguanas y lagartos de la especie Caiman yacaré.

Orientada especialmente para niños; este espacio educativo y recreativo brinda a los visitantes la posibilidad de interactuar con los animales domésticos como vacas, cabras y algunos auquénidos, allí podrán alimentar a los animales de la granja y observar de cerca su comportamiento.

TURISMO
DE ENTRETENIMIENTO Y RECREACIÓN

Santa Cruz de la Sierra

ph: GAD SCZ

CARNAVAL

CRUCEÑO

Ubicación: Av. Mutualista, entre 4to y 8vo anillo

ph: GAD SCZ

Si buscás contagiarte de la auténtica alegría de Santa Cruz, tenés que vivir la experiencia de su carnaval. Reconocida como Patrimonio Cultural de Bolivia; el "Carnaval Cruceño" es una de las fiestas más esperadas del año. Se destaca por ofrecer una amplia variedad de eventos y actividades que se celebran antes de las fechas oficiales del carnaval. Cada celebración se caracteriza por tener música, baile y derroche de alegría que contagia a todos. La agenda del carnaval empieza meses antes, con el anuncio de la " Reina del Carnaval ", quien será la persona que acompañará a la comparsa coronadora y a todo el pueblo cruceño a celebrar el carnaval. En cuanto a la programación de las actividades y eventos, es todo un espectáculo colectivo y festivo que tienen un cronograma que varía de acuerdo a los objetivos y la temática que defina la comparsa coronadora y la coyuntura por la que esté atravesando el departamento y el país.

PRE CARNAVALERAS

Comienza un mes antes, son llamadas también "precas". Participan comparsas encabezadas por la reina del Carnaval. En estas precas, los grupos folclóricos se lucen con sus danzas, coreografías y trajes típicos, brindando un espectáculo lleno de energía y ritmo. Cada "preca" tiene una temática. El recorrido se realiza por las calles del centro histórico de la ciudad.

ph: GAD SCZ

CORONACIÓN DE LA REINA DEL CARNAVAL

Una semana antes de los eventos carnavalescos, se realiza la coronación de la reina, en un evento lleno de color, música y baile, siendo todo un espectáculo que muestra la alegría que caracteriza a Santa Cruz. Desde 1937, que fue primer año que el carnaval cruceño eligió una "Reina del Carnaval"; la figura y el protagonismo de la reina ha sido la misma. Ella es el centro de la fiesta, todos los honores son para su persona y representa no solo a la belleza de la mujer cruceña, sino a la alegría del pueblo camba y a su cultura popular. Van ocho décadas desde que se eligió a la primera reina del carnaval, y todas tienen rasgos en común, su belleza y alegría que derrocharon durante su reinado. La soberana es más que una figura bonita, es el símbolo del Carnaval Cruceño. Es admirada y querida, y su presencia es solicitada en todas las fiestas, desde la más ostentosa hasta la más sencilla.

CORSO INFANTIL

Los más pequeños también tienen su espacio en el Carnaval. Tienen su propio corso, denominado "Corso Infantil", donde niños y niñas se dan cita para divertirse entre música, espumas y globos. También tienen su propia Reina y Comparsa Coronadora.

EL GRAN CORSO CRUCEÑO

El punto climax del Carnaval Cruceño es el "Corso", un desfile lleno de música, color y creatividad, que se realiza en el Cambódromo, al ritmo de la banda y la tamborita. En el recorrido saltan las comparsas desbordando colorido con fantasías y carros alegóricos que transportan a sus reinas. Cada comparsa tiene su propio estilo y vestimentas características, con trajes elaborados y coloridos. Casi siempre se trata de rescatar motivos regionales, o hacer críticas sociales, parodias o sátiras políticas. El espectáculo adquiere su máxima fastuosidad cuando ingresa la Reina del Carnaval con toda su corte constituida por los integrantes de la comparsa coronadora.

ph: Comparsa Ociosos

LOS 3 DÍAS DE MOJAZÓN

El frenesí continúa los siguientes tres días después del corso: domingo, lunes y martes; días en que la población baila y se divierte en las calles céntricas de la ciudad jugando con agua, pintura y espumas, viviendo momentos de total alegría.

CARNAVALITO

El tradicional Carnavalito marca el fin de los festejos de la "Fiesta Grande". Se vive una fiesta costumbrista con el entierro del muñeco, que representa la despedida de esta fiesta. El Carnaval Cruceño es sin duda alguna uno de los principales atractivos turísticos que tiene la ciudad de Santa Cruz de la Sierra. Su importancia cultural radica en la preservación y transmisión de las tradiciones cruceñas a las nuevas generaciones, fortaleciendo así el sentido de identidad y pertenencia.

CENTROS COMERCIALES

Si algo no puede faltar en tu viaje a Santa Cruz de la Sierra es una visita a los centros comerciales que tiene la ciudad, con una amplia oferta de opciones donde podrás pasar horas disfrutando de compras, comida y entretenimiento en un solo lugar. La región metropolitana de Santa Cruz no ha sido ajena a los procesos de globalización que han sucedido en las grandes ciudades y zonas urbanas y tal es el caso de la presencia de importantes centros comerciales impulsados por la visión emprendedora del empresariado cruceño. Estos centros comerciales aglutinan las más importantes marcas a nivel global y nacional, tanto de ropa, perfumes, joyas, zapatos, artefactos y artículos para el hogar, tecnología, gastronomía y otros. Asimismo, la mayoría de los centros comerciales, tienen la oferta de patios de comidas con una extensa oferta culinaria, que va desde comidas de marcas locales, como también la presencia de grandes franquicias gastronómicas internacionales. ¡Hay para todos los gustos! Por otro lado, también ofrecen otros servicios complementarios como supermercados, farmacias, gimnasios, salas de cine, eventos dirigidos para la familia con una agenda semanal de acuerdo a cada época del año, parques infantiles, salas de juegos, servicios de telefonía y bancos con cajeros automáticos para comodidad de sus visitantes y amplios parqueos. Cada centro comercial tiene su característica que lo hace único y particular y que pone a Santa Cruz al nivel de países de primer mundo en la oferta del retail y de mall. En resumen, Santa Cruz de la Sierra es un destino perfecto para los amantes de las compras, con una amplia variedad de centros comerciales que ofrecen todo lo que puedas imaginar. ¡No dudés en incluirlos en tu itinerario y disfrutá al máximo de tu viaje!

ph: GAD SCZ

VENTURA MALL

Ubicación: Av. San Martín, 4to anillo
Atención: Locales Comerciales: De Lunes a Sábados de 10:00 a 22:00
y Domingo de 11:00 a 22:00

ph: GAD SCZ

Ventura Mall es el mayor complejo comercial del país. Es un centro comercial moderno con suficientes tiendas para satisfacer las necesidades de una ciudad en crecimiento. El lugar es ideal para quienes buscan hacer compras de todo tipo de marcas internacionales y compañías nacionales, desde artículos deportivos, ropa, zapatos, representantes de venta de autos, cosméticos, entre otras. El centro comercial alberga un supermercado, farmacia, áreas de entretenimiento familiar con bowling, videojuegos, auto chocadores y un cine, que, para la comodidad de los cinéfilos, es el primer complejo multisalas del país, cuenta con 13 salas de cine, distribuidas en salas VIP, medianas y grandes. Además, cuenta con un amplio patio de comida y un boulevard en exteriores

ph: GAD SCZ

ph: GAD SCZ

que ofrecen una gran variedad de opciones y restaurantes, ideales para comer algo después de una larga jornada de compras y entretenimiento. Por otro lado, una de las grandes ventajas que ofrece Ventura Mall, son sus locales de servicios como agencias de viaje, telefónicas y bancos, pudiendo hacer estas gestiones en horarios no convencionales. Igualmente, cuenta con amplios parqueos en exteriores y en subsuelos para la comodidad de quienes visiten el centro comercial. Toda esta oferta, hace del Ventura Mall, un lugar completo para ir en familia o con amigos.

Otra opción ideal para pasar un día de compras en Santa Cruz es en “Las Brisas Centro Comercial”. Ofrece una amplia oferta comercial y de entretenimiento, con una variedad de locales comerciales de marcas nacionales e internacionales, con franquicias de prendas de vestir, zapatos, cosmética, artículos deportivos, artículos para el hogar, juguetes para niños entre otras marcas. Asimismo, tiene un complejo de nueve salas cine, un supermercado, un área de juegos infantiles, un gimnasio, un patio de comida y un boulevard de restaurantes en exteriores, con ofertas gastronómicas para todos los gustos. También está el servicio de un banco donde podés hacer tus gestiones en el caso de necesitarlo en otros horarios no convencionales. Para la comodidad de sus visitantes cuenta con parqueo techado.

Ubicado en la zona sur de la ciudad, Megacenter ofrece una sala juegos, patio de comidas, restaurantes, bares, tiendas comerciales, gimnasio, discoteca, comercios y servicios financiero, telefónicas entre otros, asistidas por un parqueo propio de varias plantas, lo convierten en una cómoda opción de entretenimiento para las familias cruceñas. Uno de los principales hitos de este centro comercial, fue el haber sido el pionero en presentar el primer cine multisalas de Bolivia.

Se define como un espacio en el que la moda, la gastronomía y la vida social se fusionan para dar a sus visitantes una experiencia única y agradable en un ambiente con un diseño paisajístico y entorno vanguardista para pasear, realizar compras, hacer negocios, disfrutar de una deliciosa gastronomía, compartiendo veladas con amigos y la familia. Cuenta con un gimnasio, un área de juegos para los más pequeños, una oferta de restaurantes para paladares exigentes, entre cafeterías gourmet, heladerías, chocolaterías con terrazas al aire libre, en la que también encontrarás restaurantes de alta cocina con diferentes tipos de comida en espacios con cocina abierta para generar una experiencia única entre el chef y el cliente. Para la comodidad de sus visitantes cuenta con un amplio subsuelo como zona de parqueo.

El Centro Comercial “Casco Viejo” es uno de los centros de compra tradicionales de la ciudad. Actualmente, ofertan artículos del hogar, tiendas de ropa, dispositivos tecnológicos, videojuegos, artistas del tatuaje entre otras ofertas. También, allí podés encontrar la biblioteca de la Sociedad de Estudios Geográficos e Históricos de santa cruz, con una valiosa colección a disposición de investigadores. El lugar es perfecto para fotografiarse, si es que uno quiere representar el estilo arquitectónico cruceño, ya que sus galerías amplias con pilastras de madera tienen una estética muy destacable. El edificio fue construido en la segunda mitad de la década de los ‘80 y fue inaugurada el 7 de octubre de 1988. Su construcción respeta y rememora las antiguas casonas coloniales de la Santa Cruz de antaño.

Centro comercial recientemente inaugurado. Ubicado en la zona este de la ciudad, próxima a la Feria de Barrio Lindo. Cuenta con una amplia oferta de locales comerciales, un supermercado, patio de comida, área de juegos para niños, salas de cines y una amplia zona de parqueo. Pretende consolidarse como un centro comercial con una excepcional experiencia de compras y un destino para el ocio y la diversión.

Si estás en Santa Cruz un miércoles o un sábado, estás de suerte, ya que estás en días de “feria”; esta expresión común en Santa Cruz hace referencia a los días de atención de la “Feria de Barrio Lindo”, que ofrece una amplia variedad de productos, donde encontrarás realmente de todo, desde ropa, calzados, electrodomésticos, muebles, juguetes, herramientas, comestibles y un amplio etcétera, es parte de la oferta que tiene esta feria popularmente conocida.Es uno de los lugares más frecuentados a la hora de comprar al menudeo y a por mayor, especialmente durante la temporada navideña. La Feria de Barrio Lindo tiene una amplia historia en Santa Cruz, funcionando en el siglo XX en el barrio del mismo nombre ubicado en las cercanías de la Av. Brasil y 2do anillo. A partir del año 1999 se trasladó a su actual ubicación donde creció al ritmo de la Metrópolis cruceña, convirtiéndose hoy en la Feria más grande del país con más de 18 Hectáreas de Feria entre sus diferentes comerciales. Como un dato adicional, si vas a la feria, no olvidés que regatear el precio o “pedir rebaja” es una costumbre al momento de comerciar.

IC NORTE

Ubicación: Av. Busch, tercer anillo
Atención: Lunes a Domingo 07:00 a 22:00

IC Norte es una cadena de supermercados que ofrece otros espacios y servicios complementarios como patio de comida con una amplia oferta culinaria, locales comerciales, un espacio de juegos para niños y un gimnasio. Dispone de una zona de parqueo para sus visitantes.

CIUDAD INDANA

Ubicación: 3er anillo entre Avenidas Piraí y Radial 19
Atención: Lunes a Domingo 09:00 a 22:00

Ubicado en la zona sur, se encuentra el centro comercial Ciudad Indana, que se caracteriza por tener tiendas sectorizadas. En la planta baja están los negocios de tecnología. En su primer piso, además del patio de comidas y la sala de juegos, se encuentran los comercios de moda y belleza. También cuenta con oficinas de servicio público, como el Servicio General de Identificación Personal (Segip), cuya presencia ha incrementado el flujo de público que busca realizar trámites en ambientes modernos, cómodos y con opciones de entretenimiento accesibles.

CENTRO COMERCIAL CAÑOTO

Ubicación: Av. Cañoto, esq. calle Buenos Aires
Atención: Lunes a sábado: 09:00 a 20:00

Uno de los primeros centros comerciales que ha tenido la ciudad de Santa Cruz ha sido el Centro Comercial Cañoto, un centro comercial que abrió sus puertas en los años ochenta y resultó ser toda una novedad para la época, ya que presentaba un ambiente descontraído donde además de poder hacer compras se podía pasear y compartir momentos en familia. Este centro comercial aún continúa vigente y ya lleva una larga tradición en el mercado cruceño.

SHOPPING BOLIVAR

Ubicación: Calle Bolívar y 24 de Septiembre
Atención: Lunes a Domingo: 09:00 a 19:00

Es un centro comercial con una oferta principalmente tecnológica, de dispositivos móviles y otros artefactos tecnológicos. Asimismo, presenta una oferta de comida en sus terrazas teniendo importantes locales como Irish Pub, que ya forma parte de la tradición en la oferta culinaria cruceña. Un aspecto importante a resaltar es que está construido sobre un edificio que guarda las características de las antiguas casonas coloniales de la Santa Cruz de antaño.

CENTRO COMERCIAL NORTE

Ubicación: Tercer anillo, entre Av. Alemana y Av. Mutualista
Atención: Lunes a Domingo: 09:00 a 21:00

Un centro destinado principalmente a la oferta de tiendas de ropa para mujeres, varones, niños, accesorios; salones de belleza, spa, agencias de viaje entre otros. En su centro tiene una pequeña plaza con una cafetería para tomarse un cafecito y una merienda, mientras se descansa después de hacer las compras. Dispone de un parqueo en la terraza.

RAMÓN "TAHUICHI" AGUILERA COSTAS

Ubicación: Entre las avenidas del Ejército Nacional, Ana Bárbara y Chóferes del Chaco

ph: GAD SCZ

El escenario deportivo más emblemático del departamento y el segundo más grande de Bolivia con una capacidad para 38 mil espectadores. Se encuentra a una altura sobre el nivel del mar de 429 msnm. Es hogar de los clubes de la Liga de Fútbol Profesional Boliviano, donde oficia como local Royal Pari, Blooming y Oriente Petrolero; estos últimos, cuyos encuentros entre ellos, generan el denominado Clásico Cruceño, que suele atraer a grandes multitudes de hinchas. El recinto también es el estadio local de varios clubes de la Asociación Cruceña de Fútbol en el torneo regional de Segunda División Boliviana. Inaugurado en 1940, el estadio ha pasado por varias refacciones y expansiones, la más notoria siendo la que tuvo lugar en 1996-1997, en preparación para la Copa América. El estadio también fue uno de los escenarios principales de la Copa América 1997 y los Juegos Bolivarianos de 1993. La selección nacional de fútbol de Bolivia también juega partidos amistosos allí regularmente. En 1986, el estadio 'Tahuichi' Aguilera dio cabida al partido que la selección nacional jugó ante su similar de Brasil por las eliminatorias para el Mundial de 1986. En cuanto a su historia, , se empezó a construir el 28 de enero de 1938 y fue estrenado un 25 de mayo



de 1940. Cuando fue terminado recibió el nombre de Estadio Departamental de Santa Cruz. A partir de esa etapa, este campo deportivo fue cambiando en sus características y estructura, pero permanentemente albergó los campeonatos organizados por la Asociación Cruceña de Fútbol y fue sede de los equipos cruceños que disputaron los campeonatos nacionales, entonces denominados Copa Simón Bolívar. A partir de 1977 fue utilizado por los clubes locales que formaron parte de la Liga del Fútbol Profesional Boliviano. Entre 1968 y 1970, fueron ampliadas las graderías del sector general donde los relatores de la época transmitían los partidos en improvisadas cabinas de madera. En 1972 el Estadio Departamental cambió de nombre por el del piloto e ídolo del automovilismo Willy Bendek, en su memoria tras su trágica muerte en un accidente durante una prueba nacional que se organizó en 1971 sobre el actual segundo anillo de circunvalación. Los logros nacionales e internacionales de la Academia 'Tahuichi' Aguilera hicieron que en 1979 el estadio volviera a cambiar de nombre por el de Ramón Aguilera Costas, figura de antaño del fútbol local y padre del entonces fundador y presidente de la exitosa Academia, Rolando Aguilera Pareja.

CLÁSICO CRUCEÑO

ph: Club Blooming

Ya sea que peleen un título, el descenso, la Copa Libertadores o el "7mo puesto", el clásico cruceño, que enfrenta a los equipos de Oriente Petrolero y Blooming, siempre estará lleno de pasión, alegría, cánticos y color. Es uno de los duelos más convocantes de Bolivia y por esta razón, la prestigiosa revista británica FourFourTwo, lo ha catalogado entre los 50 mejores clásicos del mundo. El equipo Oriente Petrolero fue fundado por los trabajadores de Y.P.F.B (Yacimientos Petrolíferos Fiscales Bolivianos), el 5 de noviembre de 1955. Nació con el nombre de Petrolero, agregando posteriormente Oriente para ganar simpatizantes de la región. Han apodado al club como los refineros y también como los verdolagas. Por su parte, el equipo de Blooming fue fundado el 01 de mayo de 1946 y es conocido también como la Academia Cruceña. En relación a la rivalidad entre ambos equipos, que se convirtió de pronto en la madre de las batallas, no existe un momento preciso que indique el inicio de esta rivalidad. Hinchas, exdirigentes que disfrutan este partido hace varias décadas, ninguno precisa el momento, pero coinciden en que este duelo empezó a ser "el clásico" a secas a fines de los años sesenta, año que coincide con una polémica que pudo haber dado el inicio definitivo a esta rivalidad. Tuvo que ver con la lesión del arquero celeste Erwin Frey en un encontronazo con el atacante argentino Silvio Rojas, de Oriente, en el cual el argentino le produjo una fractura en el brazo al futbolista del cuadro celeste. Se cree que este altercado fue lo que dio origen a la rivalidad entre los dos equipos. De todas maneras,

el origen de la rivalidad no es fácil decirlo, lo importante es que está vivo y que despierta la pasión de su hinchada, Blooming y Oriente, Oriente y Blooming son una marca registrada cruceña. Adicionalmente, el superclásico cruceño, además de ser un espectáculo, tiene un muy importante sentido de pertenencia en Santa Cruz, ya que, en todas sus ediciones, es el único partido donde se entona inicialmente el himno cruceño y el local, tanto como el visitante, se esfuerzan por hacer un recibimiento mejor que en el partido anterior. Es más, en la semana previa al "clásico", es una semana en la cual todos los círculos sociales de Santa Cruz, se menciona, al menos una vez, los diferentes argumentos que esgrimen uno y otros hinchas, de cuál equipo será el "gran ganador" del clásico. Han pasado los años y el clásico se volvió más clásico, más picante, con barras que se hacen sentir de verdad. Ambos equipos han sido importantes actores en el escenario local saliendo campeones en múltiples ocasiones y teniendo importantes participaciones en copas internacionales como la Copa Libertadores y Sudamericana; además de ser semilleros de varios de los más destacados jugadores del país como Milton Melgar, Joselito Vaca, Juan Carlos Arce... Así que, si tu visita por la ciudad coincide con este espectáculo deportivo, y sos un apasionado del fútbol, no podés dejar de asistir y vivir la experiencia de uno de los mejores 50 clásicos del mundo.

ph: Club Blooming

ph: Club Blooming

VILLA OLIMPICA

Ubicación: Entre 4to. Y 5to. Anillo, entre las avenidas Santos Dumont y Avenida Olímpica

ph: GAD SCZ

Al sur de la ciudad, en una extensión de aproximadamente 160 hectáreas de área verde, se conserva un gran espacio dedicado a las prácticas de múltiples disciplinas deportivas. Se trata de la denominada Villa Olímpica "Abraham Telchi", en honor a su meritorio impulsor en los años 70 del siglo pasado, donde en la actualidad se ha logrado concentrar diversas disciplinas con un alto nivel de competencia.

Polígono de tiro deportivo, con ambientes para la enseñanza y práctica de esta disciplina en todas sus modalidades.

Escenario relativamente nuevo es el estadio de atletismo dotado de pista reglamentaria de tartán, graderías, áreas para la práctica de las diferentes modalidades, zona de calentamiento y oficinas. Cerca del lugar está el escenario de béisbol y sóftbol con cancha reglamentaria.

El complejo de ráquet cuenta con varias canchas reglamentarias donde se han disputado torneos internacionales, pues tiene graderías y oficinas. En el lugar también se encuentran canchas de fútbol con césped natural y sintéticas, además de canchas de fútbol de playa.

Frontones para la práctica de raqueta y pelota frontón. Un circuito reglamentario de bicicross, donde también hay graderías y oficinas. El picadero para competencias de hipismo rural también tiene su espacio y un velódromo que ya albergó competencias internacionales.

Motodromo con pista reglamentaria para cross y enduro, tiene graderías, torre de control y oficinas de la Asociación Departamental de Motociclismo Santa Cruz. Algo similar tiene el kartódromo, donde se realizan competencias oficiales.

Piscina olímpica con 10 carriles y otra pileta para clavados, además de graderías y vestuarios, entre otras obras.

CAPACIDADES DE AFORO

- Estadio de atletismo: 3.500 espectadores aprox.
- Piscina olímpica: 1.500 espectadores aprox.
- Escenario de bicicross (BMX): 100 espectadores aprox.
- Escenario de raquetbol: 100 espectadores aprox.
- Escenario de karting: 200 espectadores aprox.
- Escenario de motociclismo: 200 espectadores aprox.
- Escenario de pelota frontón: 100 espectadores aprox.
- Escenario de canchas césped sintético: 400 espectadores aprox.
- Escenario de squash: 50 espectadores aprox.
- Periodicidad de uso que tiene: Diario – eventos programados

ÁREAS SANITARIAS

Cuenta con 30 baterías de baños para damas y varones en todo el complejo deportivo.

CAMERINOS: cuenta con 10 camerinos

- Escenario de Raquetbol 2 camerinos
- Estadio de atletismo 2 camerinos
- Piscina olímpica 2 camerinos
- Canchas de pasto sintéticos 4 camerinos

GRAN PREMIO INTEGRACIÓN DEL ORIENTE

Ubicación: Largada se realiza en el Cambodromo

El Gran Premio Integración del Oriente nació en 1979 como una necesidad de unir a los pueblos del Oriente Boliviano abriendo caminos a través de una competencia automovilística y más que todo cumplir con el lema que identificaba en la época que era "hacer automovilismo es mejorar los caminos, es hacer patria". Desde entonces, se ha consolidado como una de las carreras mas importantes y esperadas de todo el calendario automovilístico

en Santa Cruz y la más emblemática del país y cuya largada, en los últimos años, se ha realizado en las instalaciones del Cambodromo. Existen diferentes categorías (motos, coches, UTV y 4×4) y cada una tiene su respectivo campeón que obtiene el título como los mejores del Gran Premio Integración del Oriente y entrarán a la historia. Lógicamente, que como en todas las competencias, siempre hay un ganador de la clasificación general, que es el mejor de los mejores. Participan alrededor de 60 pilotos quienes son los que entran a la ruta, entre máquinas de dos y de cuatro ruedas y recorren generalmente gran parte de la Chiquitania: comenzando por Cotoca, pasando por Ascensión de Guarayos, San Javier, Concepción, San Miguel de Velasco hasta terminar en Montero.

CODASUR SANTA CRUZ

Ubicación: Largada se realiza en el Cambodromo

El Rally Santa Cruz es el mayor y más importante evento de automovilismo deportivo en Bolivia, forma parte del Campeonato Sudamericano de Rally FIA – CODASUR, donde participan los mejores pilotos de rally de Paraguay, Argentina, Uruguay, Brasil, Ecuador, Chile, Perú y los mejores pilotos de Bolivia. En los últimos años ha tenido como cuartel general y parque de operaciones el Cambodromo Santa Cruz, donde se realiza la competencia durante tres días recorriendo caminos de los municipios de Santa Cruz de la Sierra, Montero, Colpa Bélgica, Warnes, La Guardia y El Torno.

ESTADIO DE REAL SANTA CRUZ

Ubicación: Tercer Anillo, Av. San Aurelio

El Estadio Real Santa Cruz, es un recinto deportivo propiedad del Club Real Santa Cruz, ubicado en la ciudad de Santa Cruz de la Sierra, Bolivia. Fue inaugurado el año 1997 como un campo alternativo al Estadio Ramón Aguilera Costas con motivo de la realización de la Copa América llevada a cabo en Bolivia aquel mismo año. Cuenta con capacidad para 14 000 espectadores y acoge los encuentros que disputa como local el Club Real Santa Cruz, uno de los clubes fundadores de la Liga Profesional del Fútbol Boliviano. Sus instalaciones también son sede de importantes eventos, conciertos y espectáculos; entre los artistas que se han presentado, está Marco Antonio Soliz, Marc Antothy, Vicente Fernández, Maná, entre otros.

SEDE DE BLOOMING

Ubicación: Octavo anillo, Avenida Prolongación Beni

Está ubicado en la zona norte de la ciudad de Santa Cruz de la Sierra, con una superficie de 10 hectáreas. Se constituye como una de las mejores sedes deportivas del país, la misma fue un regalo de uno de los presidentes más importantes que ha tenido el club, Roberto Paz Limpias.Consta de 6 canchas: 1 profesional para el primer plantel, 1 profesional para la sub-19, 1 de fútbol 8 para la sub-17, 2 de fútbol 7 para la sub-15 y sub-13, respectivamente y la última que también es de fútbol 7 que es utilizada por los socios patrimoniales del club. Además, cuenta con un Coliseo cerrado de 5 mil espectadores donde se hace la práctica de distintas disciplinas deportivas.

COLISEO POLIDEPORTIVO

DE LA UNIVERSIDAD AUTÓNOMA GABRIEL RENÉ MORENO UAGRM

Ubicación: Avenida Busch N° 980 entre Av. Santos Ortiz y lado INEGAS

La Universidad Autónoma Gabriel René Moreno tiene el coliseo polideportivo más grande de la región metropolitana, tiene una capacidad para albergar más de cinco mil personas; una infraestructura inaugurada en octubre del 2016. Es un escenario de alta competición para que los estudiantes realicen sus prácticas deportivas, fue construido en una dimensión de 6.178 m2 con todas las medidas reglamentarias.

COLISEO GILBERTO PARADA

Ubicación: Calle Ingavi entre calle Vallegrande y Calle Sara

Un coliseo histórico de Santa Cruz, que ha sido la principal sede para las disciplinas de básquet y voleibol en el departamento. Cuenta con unas canchas de parque que son ampliamente requeridas, conocidas o frecuentadas por diferentes generaciones de deportistas que han pisado estas canchas destacando en campeonatos locales y nacionales. Aquí también se encuentra la sede más importante de la disciplina del ajedrez, una escuela de muchos años, así como también de karate y un gimnasio. Todas las disciplinas mencionadas tienen una permanente oferta para practicarlas, accesibles a todos los bolsillos; algunos son brindados desde por el Gobierno autónomo Departamental de Santa Cruz y diferentes otras escuelas. Este coliseo es parte del complejo deportivo llamado Gilberto Menacho, en honor a uno de los hombres que, juntos a otros amantes del deporte de los años 60, decidieron comprar ese terreno en la calle Ingavi (centro de la ciudad) para que allí la juventud haga deporte de manera organizada. El básquet fue la primera disciplina que allí se practica. Después el complejo deportivo fue construyéndose por fase, pues cada vez se sumaban más disciplinas en el lugar: ajedrez, esgrima, vóleibol y pesas, entre otras.

MARATÓN ADIDAS

Ubicación: Cambódromo cuarto anillo

Es una de las carreras más esperadas del año y uno de los eventos pedestres más importantes de Bolivia, que convoca a una ola de 5.500 corredores del todo el país, atrayendo también a corredores internacionales que buscan desafiar sus límites y disfrutar de una experiencia única en las carreras de larga distancia y carreras pedestres. Esta carrera es las maratones de Miami y Buenos Aires. El evento tiene cuatro categorías de competición para damas y varones, 42k, 21k, 10k y 5k, siendo por lo tanto toda una fiesta deportiva. Desde su segunda versión (2016), la prueba inicia y finaliza en el Cambódromo y el recorrido pasa por diferentes puntos representativos e icónicos de la ciudad: El Cristo Redentor, la Plaza 24 de Septiembre, Parque Urbano, la estatua de la Madre India, entre algunos lugares para mencionar. La Adidas maratón de Santa Cruz de la Sierra está certificada, la autentificación fue otorgada por la Asociación Internacional de Federaciones de Atletismo (IAAF), que es el organismo rector de este deporte en el mundo, juntamente con la Asociación de Maratones Internacionales y Carreras de Distancias (AIMS), que se encarga de fomentar y promover las carreras de distancia larga.

CABAÑAS RÍO PIRAÍ

Ubicación: Av. Roca y Coronado, 5to anillo

ph: GAD SCZ

Las cabañas del Río Piraí es un lugar turístico en la zona oeste de la ciudad de Santa Cruz de la Sierra donde podés encontrar y degustar diferentes platos típicos de la región como ser el locro de gallina, majao, keperí, picante de pollo, además de masitas y horneados típicos como el cuñapé, sonso, empanada de queso, de carne, de charque y de pollo, pan de arroz, roscas de maíz, masaco de plátano y yuca, tamal al horno y a la olla.

ph: GAD SCZ

Adicionalmente a la gran variedad de comida típica, las cabañas cuentan con diferentes actividades como pasear en cuadratack en circuitos a través del río y montar a caballo. Los días de atención de este lugar es de lunes a domingo y cuenta con parqueo para sus visitantes.

En relación a su historia, las cabañas del río Piraí se fundó en 1962 con unas 25 cabañas y fueron trasladadas luego del turbión del Río Piraí de 1983 al lugar en donde se encuentran. El lugar se ha convertido en un paseo tradicional para los viajeros que pasan por la zona y para los habitantes de la ciudad. En cuanto a las características de las cabañas, son de motacú, tienen horno de leña, y sus calles son de tierra, haciendo algo muy característico de la tradición cruceña.

El mes de septiembre es el aniversario de las cabañas del Río Piraí y todos los fines de semana se lo celebra con distintos festivales incluyendo una degustación de los horneados típicos de la región.

CHAPLIN SHOW

Atención: De acuerdo a programación
Ubicación: Av. Marcelo Terceros Bánzer, Tercer anillo, N° 202

ph: Chaplin Show

"Chaplin Show" es un espectáculo humorístico conformado por talentosos y reconocidos intérpretes, quienes son los encargados de dar vida a los distintos cuadros de humor, basados en la cotidianidad y coyuntura local. Varios son los personajes que desfilan por el escenario durante el espectáculo. Un show muy dinámico que se presenta en el Teatro de Chaplin Show, el cual acompaña la experiencia "Chaplinera", con más de 38 años de carrera humorística, Los fundadores eligieron el nombre de "Chaplin Show" inspirados en la figura de Charles Chaplin, un símbolo del humorismo y el cine mudo. El primer espectáculo se llamó "Viva la Amistad" que se estrenó el 28 de agosto de 1985. A partir de entonces la historia de Chaplin Show se resume en una extraordinaria unión entre los artistas y espectadores de la ciudad.

SHOW DE MIER

Atención: De acuerdo a programación
Ubicación: Calle Ricardo Jaimes Freire, esquina Enrique Finot, Hotel Toborochi (Zona Equipetrol), Segundo anillo.

ph: Show de Mier

"Show de Mier" es un espectáculo de comedia que hizo su debut en el 2018; tiene un excelente elenco de teatro humorístico, cuyos creadores tienen años de experiencia en la carrera humorística en Santa Cruz y en el país.

CENTROS DE CONCIERTOS Y SHOWS MUSICALES

En los últimos años, la ciudad de Santa Cruz de la Sierra, se ha convertido en la sede de los grandes conciertos, con una amplia variedad de espectáculos de diferentes géneros musicales para disfrutar con los amigos y la familia, por lo que existen diferentes espacios con la infraestructura, capacidad y logística para albergar la realización de este tipo de espectáculos y shows musicales.

Entre algunos de los artistas que han brindado su espectáculo en tierras cruceñas, podemos mencionar Maná, Shakira, Marc Anthony y Daddy Yankee, entre otros.

ph: Luis Vega

ph: Sonilum Arena

Se autodefinen como un referente en la industria del espectáculo en Bolivia. En sus instalaciones se han realizado conciertos como el de Carlos Vives, Luis Fonsi, Ana Gabriel, el aclamado DJ Martin Garrix, los Fabulosos Cadillacs, Los Auténticos Decadentes, entre otros.

Espacio de 18.000 metros cuadrados para el desarrollo de eventos musicales. Se han realizado conciertos, festivales de música electrónica, como el Ultra Bolivia, DJ Hardwell, Life in Color, entre otros.

Empresa dedicada a la organización de eventos musicales, teatrales, festivales de danzas y conciertos internacionales. Cuentan con un área de patio de comidas, donde se puede compartir con los amigos o familiares algun snack o "piqueo" previo al ingreso del concierto o evento que esten asistiendo. Adicionalmente, tienen camerinos totalmente cómodos, seguros y adecuados para que los fanáticos tengan una experiencia directa con sus artistas que entrarán en escena. Cuentan con tres áreas de parqueo para comodidad de todos los asistentes. En sus instalaciones se han realizado festivales de música internacional y nacional, como la Cumbia Fest, punto de "parqueo" para comparsas carnavaleras, entre otros.

ph: Casa Grande

CASA GRANDE

Ubicación: Av. Beni, entre 6to y 7mo anillo

Espacio de entretenimiento con oferta gastronómica, eventos y espectáculos. Se han realizado conciertos como el de Alicia Villarroel, llegales, Pipe Bueno, Diego Ríos, entre otros.

ph: Arena 26

ARENA 26

Ubicación: Radial 26, Sexto anillo

Espacio donde se llevan a cabo, variedad de eventos, como conciertos, festivales, eventos corporativos e institucionales. Se han realizado conciertos como el de Juanes, Bacilos, Huey Dunbar, Los Totora, entre otros festivales de música.

ph: Hard Rock Café

HARD ROCK

Ubicación: Ventura Mall, Boulevard Gastronómico, Av. San Martín, Cuarto Anillo
Atención: Domingo, lunes, martes, miércoles: 12:00 a 00:00 Hrs. Jueves: 12:00 a 01:00 Hrs. Sábado y domingo: 12:00 a 02:00 Hrs.

La franquicia, famosa en todo el mundo por su música, su atmósfera y sus productos, se encuentra ubicada en la ciudad en el boulevard gastronómico del centro comercial Ventura Mall. Es sede de veladas, conciertos en vivo, eventos empresariales e institucionales. Cuenta con una tienda, rock shop, y otros seis ambientes: una terraza, un área de bar, el restaurante, zona vip 1, zona vip 2 y la terraza vip.

ph: JlsiFuentes

FERIA DE LAS

ALASITAS

Ubicación: 7mo al 8vo anillo del Cambodromo

Más de 2.000 artesanos llegan de todo el país para ofertar sus artesanías en miniatura para niños y grandes en la "Feria de las Alasitas"; una feria anual tradicional donde artesanos exponen una variedad de miniaturas que están al alcance de todo bolsillo. La tradición establece que uno compre una miniatura artesanal de lo que más le haga falta en el año que cursa para convertirlo después en algo grande y real. Esta creencia se convierte en una de las principales motivaciones para visitar y hacer compras en la feria de las Alasitas. Esta fiesta tradicional originaria de La Paz, se realiza en todo el país, pero en cada lugar se desarrolla en diferentes épocas del año, teniendo su propia particularidad. En Santa Cruz, ha encontrado su espacio y costumbre, teniendo una connotación más comercial que religiosa. Se realiza en las inmediaciones del Cambodromo en el mes de septiembre, coincidiendo con el mes aniversario de Santa Cruz, extendiéndose hasta el mes de octubre, creando durante su tiempo de exposición, unas semanas de magia y alegría para aquellos que se aventuran en la muestra. Participan artesanos de Santa Cruz y de otros departamentos; muchos llevan más de medio siglo siendo parte de esta feria. Cada año los artesanos prometen presentar grandes novedades en miniatura, adaptándose a las tendencias actuales. Por ejemplo, se puede encontrar alcancías en forma de "emojis" que son usados en mensajes electrónicos o también con detalles tecnológicos como los hashtags, para que la gente se lleve lo que le guste. Sin embargo, las estrellas de esta feria son sin duda las miniaturas, las pequeñas réplicas meticulosamente elaboradas de objetos de deseo: casas, autos, diplomas, billetes y más. Así que si tenés la oportunidad de visitar la feria de las Alasitas, no dudes en comprar alguna de estas miniaturas, quizás de acuerdo a la creencia, puede que se haga realidad. En cuanto a la gastronomía, las Alasitas son todo un festín para los sentidos. Podés degustar pacumuto, silpancho, empanadas y otros platos típicos en un ambiente que va desde el humo de las comidas típicas bolivianas hasta el aroma de los sahumerios que queman las caseras. También podés encontrar juegos tradicionales, que nunca pasan de moda. Desde el tiro al blanco hasta el lanzamiento de vasos con una pelota, estos juegos te desafiaran a probar suerte y habilidad y aunque sabes que es difícil ganar, la competencia con tus amigos y familiares añade un toque especial de emoción. Por otro lado, están las luces características de los juegos mecánicos que ilumina el cielo nocturno de Santa Cruz. Los niños corren emocionados para hacer fila y subirse a los autitos chocadores, a la rueda de la fortuna o los barcos vikingos que son también parte de esta singular feria y que sin duda es una buena oportunidad para llevar a los pequeños de la casa a divertirse. La feria artesanal en Santa Cruz es mucho más que un evento. Es una ventana a la rica cultura boliviana y a la conexión con sus raíces indígenas. Para algunos, es la búsqueda de objetos en miniatura que puedan ayudar a cumplir sus sueños; para otros, es simplemente una oportunidad de pasar un rato agradable en compañía de familiares y amigos.

TURISMO DE NEGOCIOS

Santa Cruz de la Sierra



ph: GAD SCZ

EQUIPETROL

Ubicación: Av. San Martin, entre segundo y cuarto anillo

ph: GAD SCZ

El barrio Equipetrol es el centro empresarial y comercial más importante de la ciudad, además del más cotizado por los inversionistas, tanto por ser zona residencial como por las actividades comerciales, donde se encuentran las tiendas más exclusivas, al igual que los locales de gastronomía y establecimientos hoteleros. Podés recorrer la avenida San Martín, su arteria principal, desde el segundo hasta el cuarto anillo. Sobre ella y en sus calles aledañas, encontrarás muchas tiendas, hoteles cinco estrellas, restaurantes, cafés, supermercados y centros comerciales. En esta zona notarás el imparable crecimiento de la ciudad, con varias obras de gran magnitud que están en plena construcción; pero, ***¿qué hace que esta zona sea tan atractiva para la actividad comercial y las inversiones?***

Gran oferta de servicios: Es una zona muy cercana al centro de la ciudad, y no tiene nada que envidiarle en cuanto a comodidades. Cuenta con una completa oferta de servicios, no solo comercial, también de ocio y universidades, lo que le da un ritmo cultural propio de una gran ciudad.

Estándar de vida elevado: Hoteles, restaurantes y tiendas de lujo, además de proyectos que apuntan al segmento más exigente y brindan lo último en tecnología, que hacen de Equipetrol una zona con un estilo de vida cosmopolita y de alto nivel.

Seguridad: Los problemas de seguridad en Santa Cruz se contrarrestan en Equipetrol con la presencia de guardia privada, y la tecnología aplicada a edificios y barrios privados.

Grandes proyectos inmobiliarios: En los últimos años irrumpieron grandes proyectos inmobiliarios que han cambiado totalmente el perfil de esta zona. Por ejemplo, la plaza empresarial Manzana 40, con sus dos torres de 30 pisos cada una, con oficinas de 56 a 960 metros cuadrados, con 810 parqueos, para unos 660 propietarios; también, está el edificio Green Tower Santa Cruz, levantada en dos torres sobre 7.300 m2 de terreno y 100 mil m2 de construcción. El "triángulo del oro" es el nombre que ha dado la prensa a esta zona que abarca incluso el área residencial de la zona Urubó, ubicada al otro lado del río Piraí a través del a través del Puente Mario Foianini.

ph: Green Tower

ph: GAD SCZ

En relación a la historia de este singular barrio, según el escritor Aure Terán Bazán, los terrenos de Equipetrol en el pasado estaban destinados al pastoreo de ganado vacuno y a la caza de perdices, chaicitas y penis. Fue urbanizado desde principios de los años 70 como barrios Los Tajibos y Guapay, aunque pervivió Equipetrol, que era el nombre de una empresa dedicada a la actividad petrolera. Alrededor de este barrio se construyó, en 1976, el hotel Los Tajibos, que llevaba el nombre real del barrio, siendo durante muchos años el primer establecimiento hotelero de cinco estrellas en la capital cruceña. Luego fue constituido el hotel Yotaú, que se destaca por su arquitectura llena de terrazas con plantas y palmeras. En la última década las casonas han dado paso a los edificios de gran altura tanto para viviendas como para oficinas. La Universidad Autónoma Gabriel René Moreno ha construido la Facultad de Ciencias del Hábitat. También hay edificios de otras universidades, como la Utepsa y la Udabol. En resumen, la zona de Equipetrol tiene la perspectiva de convertirse en el centro de operaciones empresariales no solo a nivel Santa Cruz, sino de todo Bolivia, por todo el dinamismo económico y comercial que representa y si estás en la ciudad, no dudes en darte una vuelta por esta zona.

CAINCO

Ubicación: Esq. Calle Cochabamba y Calle Saavedra
Atención: Lunes a Viernes de 08:00 a 12:00 y de 15:00 a 18:30

ph: GAD SCZ

Pocas instituciones han acompañado a Santa Cruz en su desarrollo como lo ha hecho CAINCO. Institución visionaria que siempre ha estado a la vanguardia del país, promoviendo el desarrollo de Santa Cruz, su integración nacional e internacional y apuntalando el crecimiento económico y la producción. Generadora de oportunidades para hacer empresas y gestionar negocios; que ha desempeñado un rol crucial para posicionar la iniciativa privada como motor de desarrollo. También, ha promovido el espíritu del cruceño, creativo, arriesgado, innovador, luchador, constante y perseverante. Es una institución que, gracias al prestigio forjado en sus más de 100 años de vida institucional, se ha convertido en un referente en el campo económico, tanto para el sector privado como el sector público.

Ha sido y es promotora de la creación de instituciones. Ha impulsado la creación de la Cooperativa Rural de Electrificación (CRE), que brinda este servicio a la ciudad y a sus provincias, satisfaciendo una sentida necesidad sobre todo para el desarrollo de la actividad empresarial que ha marcado el crecimiento de Santa Cruz. En ese mismo contexto es que se gesta en el seno de la Cámara, la Cooperativa de Teléfonos Automáticos de Santa Cruz (COTAS), que ha sido uno de los puntales del desarrollo de la región con un servicio moderno que también impulsó la región. Además, la visión de CAINCO ha ido más allá de lo empresarial; en 1984, en un acto de rebeldía para el momento, fundó la Universidad Privada de Santa Cruz (UPSA), conformando una casa de estudio para formar profesionales que contribuyan al desarrollo del departamento y de Bolivia. Por otro lado, es importante destacar, la labor que ha realizado CAINCO en aglutinar a los empresarios y emprendedores de las diversas actividades económicas y apoyarlos con los servicios de capacitación, vinculación comercial e internacional a través de ruedas de negocios, misiones empresariales a otros países y en todo lo relacionado al incremento de los negocios con el fin de apoyarlos para que se logre cantidad y calidad en la producción para el consumo nacional y la exportación. CAINCO, como institución empresarial vio la luz, el 15 de febrero de 1915, donde quince empresarios cruceños unían sus voluntades para crear la Cámara de Comercio de Santa Cruz ante los testigos de la Gobernación en el marco del Palacio de Gobernación. Eran los 15 primeros asociados a la Cámara y en sus firmas transmitían el espíritu de unos caballeros adelantados a su tiempo. Desde entonces, esta institución viene haciendo lo que mejor sabe hacer, cuna y semilla de proyectos trascendentales para Santa Cruz y el país y mostrando que la iniciativa privada es fundamental para el desarrollo del país.

ph: Cainco

CAO

Ubicación: Av. Roca y Coronado (Predios de FEXPOCRUZ)
Atención: Horario de Oficina

ph: CAO

Institución que agrupa a asociaciones de agricultores, pecuarios y agroindustriales. Asocia a más de 70 mil productores del Departamento de Santa Cruz; de los cuales el 70% son pequeños productores, 24% medianos y el 6% grandes, además representa a más de 100 mil unidades productivas de Santa Cruz. Su misión es promover el desarrollo de las cadenas agro productivas en el ámbito nacional.

ASOCIADOS A CAO

ANAPO Asociación de Productores de Oleaginosas y Trigo

FEDEPLE Federación Departamental de Productores de Leche

F.C.S.C. Federación de Cañeros de Santa Cruz

Ingenio Azucarero Guabirá S.A.

ADA Asociación de Avicultores de Santa Cruz

ASOHFRUT Asociación Departamental de Horticultores

ASOCAÑA Sector Agroindustrial de la Caña

Ingenio Sucroalcoholero Aguaí S.A

ASOCRALE Asociación de Criadores de Razas Lecheras

ADEPOR Asociación Departamental de Porcicultores

SOCA Asociación de Productores Cañeros

Unagro Corporación

FEGASACRUZ Federación de Ganaderos de Santa Cruz

PROMASOR Asociación Nacional de Productores de maíz, sorgo, girasol, frejol y cultivos alternativos

Unión de Cañeros Guabirá

ASOCEBU Asociación Boliviana de Criadores de Cebú

CADEX

CÁMARA DE EXPORTADORES, LOGÍSTICA Y PROMOCIÓN DE INVERSIONES DE SANTA CRUZ

Ubicación: Calle Domingo Banegas N° 3901
Atención: Horario de Oficina

Institución que representa a todas las empresas dedicadas a las exportación de bienes y servicios

ph: Cadex Santa Cruz

CADECOCRUZ

CÁMARA DE LA CONSTRUCCIÓN DE SANTA CRUZ

Ubicación: Av. Santos Dumont, entre 3er y 4to anillo N° 3223
Atención: Horario de Oficina

ph: GAD SCZ

Institución que aglutina a empresas constructoras y afines al rubro de la construcción. Brindan servicio de certificación, soporte, capacitación e intermediación con el Estado, con la finalidad de construir Bolivia con empresas bolivianas.

RUEDA DE NEGOCIOS

INTERNACIONAL BOLIVIA

Ubicación: Esq. Calle Cochabamba y Calle Saavedra

La Rueda de Negocios Internacional Bolivia se realiza cada año en el mes de septiembre y en el marco de la Feria Internacional de Santa Cruz – Expocruz. Se ha convertido en uno de los principales eventos multisectoriales de Latinoamérica, donde se dan cita empresarios de alrededor de 20 diferentes países, de más de 50 sectores. Tiene una duración de 3 días, en los cuales se sostienen reuniones para hacer nuevos contactos, introducir su negocio en el ámbito internacional, encontrar socios y/o proveedores, conocer las nuevas tendencias y tecnologías, detectar nuevas oportunidades de negocios, etc. Asimismo, se puede encontrar varias posibilidades para hacer crecer una empresa o proyecto, ya que reúne a demandantes previamente seleccionados e interesados en encontrar compradores, proveedores o socios. Participar de esta rueda de negocios, no sólo ofrece la oportunidad de ampliar el portafolio de contactos a escala local, nacional e incluso internacional, sino que también permite comparar las actuales demandas del mercado en cuanto a volúmenes y precios, y evaluar el interés que genera un producto o servicio. Nace a principios de los años 90, cuando Santa Cruz se abría a la modernidad, gestada por la creatividad, trabajo e iniciativa de la Cámara de Industria, Comercio, Servicio y Turismo de Santa Cruz – CAINCO. Es una de las

ph: Cainco

actividades que más progreso ha dado al desarrollo de Santa Cruz; de ella nacieron muchas empresas y se cerraron negocios muy importantes para la evolución económica del país. A lo largo de los años, este evento multisectorial ha evolucionado más allá de ser una simple reunión empresarial, se ha convertido en un faro de oportunidades que ha tejido una red de más de 200,000 encuentros de negocios a lo largo de su trayectoria. Es un testimonio vivo de su impacto en la economía y el tejido empresarial de la región. Ofrece a las empresas la oportunidad de forjar relaciones globales, explorar nuevas alianzas y expandir sus horizontes comerciales. ¿A quiénes beneficia? A productores y fabricantes, importadores y exportadores, proveedores, distribuidores, comercializadores, agentes comerciales, prestadores de servicios, inversionistas.

ph: Cainco

FEPSC

Federación de Empresarios Privados de Santa Cruz

Ubicación: Calle Rene Moreno N° 258 (Piso 9)
Atención: Horario de Oficina

Institución que congrega al empresariado cruceño. Es el interlocutor y facilitador del diálogo ante las instancias públicas y privadas nacionales e internacionales.

CAMEBOL

Cámara de mujeres empresarias de Bolivia

Ubicación: Radial 26, Calle Padre Ceferino
Atención: Horario de Oficina

Organización que agrupa a mujeres con una actividad económica productiva, tanto emprendedoras y empresarias, naturales como jurídicas, establecidas en el departamento de Santa Cruz y en otras regiones del país.

CADEG

Cámara Gastronómica de Santa Cruz

Ubicación: Av. Las Américas N°7
Atención: Horario de Oficina

Representa al sector gastronómico del departamento. Su visión es promover y apoyar el desarrollo de la industria gastronómica que está conformada por los restaurantes de Santa Cruz, promoviendo políticas y regulaciones favorables para el desarrollo del sector. Busca la promoción de la gastronomía local, formación, generación de redes y colaboración entre los miembros para el intercambio de conocimientos, experiencias y mejores prácticas.

JUVENTUD EMPRESA

Asociación de Jóvenes Empresarios y profesionales de Santa Cruz

Ubicación: Calle René Moreno N° 258, Piso 9
Atención: Horario de Oficina

Institución que representa a emprendedores y profesionales menores de 40 años que apuestan por el progreso del país, a través de su visión emprendedora. La comunidad cuenta con más de 400 jóvenes de todo el país con quienes se reúnen frecuentemente en networkings, tertulias con personajes influyentes, masterclasses y eventos que son relevantes para el ecosistema emprendedor.

CADEPIA

Cámara Departamental de la Pequeña Industria y Artesanía

Ubicación: Av. Alemana, entre segundo y tercer anillo, calle Motacú, N°2470
Atención: Horario de Oficina

Institución de representación de micro, pequeña y mediana industria de los sectores de Orfebres, Alimentos, Maderas, Confecciones, Artesanías, Tejas y Ladrillos, Cueros, Químicos y No Metálicos, Metalmecánicos, así como también de las zonas periurbanas y provincias como Montero, Camiri, El Torno, Yapacaní, y Guarayos del Departamento de Santa Cruz.

CADEHCRUZ

Cámara Hotelera Departamental de Santa Cruz

Ubicación: Av. Marcelo Terceros Bánzer N° 305
Atención: Horario de Oficina

Agrupa, representa a propietarios de entidades Hoteleras del departamento de Santa Cruz. Su objetivo es defender los intereses del sector e impulsar y promover el desarrollo del hotelería y el turismo.

FEXPOCRUZ

CENTRO DE CONVENCIONES

Ubicación: Avenida Roca y Coronado, 3er anillo externo
Atención: Lunes a Viernes 8:00 - 12:30 y 14:30 - 18:30

ph: GAD SCZ

Es una institución boliviana, que se ha convertido en la plataforma de intercambios comerciales y sociales más grande de Bolivia y la vitrina comercial por excelencia. No es simplemente una organizadora de ferias, sino un centro de convenciones para desarrollar todo tipo de eventos empresariales. Genera escenarios donde emprendedores, empresarios y visitantes conectan, creando experiencias memorables y resultados de desarrollo para toda la sociedad. La Fexpocruz, es quien organiza unas de las ferias multisectoriales más importantes del país, la Expocruz y otras ferias empresariales sectoriales y protocolares, entre seminarios, simposios y todo tipo de eventos sociales. Su visión es ser los mayores generadores de oportunidades de Bolivia. Fue fundada en 1962 por las dos instituciones productivas más representativas de Santa Cruz, y destacadas tanto a nivel Bolivia como a nivel internacional: la Cámara Agropecuaria del Oriente (CAO) y la Cámara de Industria, Comercio, Servicios y Turismo de Santa Cruz – Bolivia (CAINCO).

ph: Fexpocruz

EXPO LECHE

Feria de Leche

Ubicación: Avenida Roca y Coronado, 3er anillo externo
Fecha: Abril *Las fechas de las ferias están sujetas a modificaciones sin previo aviso.

La principal muestra de la industria lechera que reúne a los principales productores y empresas del sector. Es una plataforma para quienes trabajan con productos lácteos y buscan ampliar sus redes de contactos y dar a conocer sus productos a empresarios y visitantes destacando los beneficios de la leche.

COSMO BEAUTY BOLIVIA

Feria Internacional de Estética y Peluquería Profesional

Ubicación: Avenida Roca y Coronado, 3er anillo externo
Fecha: Marzo *Las fechas de las ferias están sujetas a modificaciones sin previo aviso.

Es una feria de belleza con un nutrido programa de actividades, que incluye cursos de capacitación en cada área, demostraciones al vivo, congresos de profesionales internacionales, campeonatos, talleres, desfiles y shows magistrales. El objetivo es mostrar las últimas tendencias en estética, medicina estética, spa, además de la exposición de novedosos productos y servicios de las empresas expositoras.

EXPOPET

Feria de Accesorios y Actividades de Mascotas

Ubicación: Avenida Roca y Coronado, 3er anillo externo
Fecha: Marzo *Las fechas de las ferias están sujetas a modificaciones sin previo aviso.

Es el espacio donde los amantes de los animales de compañía encuentran lo mejor en productos y servicios para sus mascotas. En este evento los visitantes conocen lo mejor en actualización para profesionales, embellecimiento de mascotas, y participan de concursos caninos.

FICAD

Feria de la Construcción Arquitectura y Diseño

Ubicación: Avenida Roca y Coronado, 3er anillo externo
Fecha: Marzo *Las fechas de las ferias están sujetas a modificaciones sin previo aviso.

Destaca lo mejor del rubro ante miles de visitantes en un ambiente de modernidad y versatilidad. Este evento permite que el interesado compare precios y marcas para construcción y diseño en un mismo escenario, además de participar de actividades académicas relacionadas a la arquitectura

EXPOFOREST

Feria Integral del Bosque Bolivia

Ubicación: Avenida Roca y Coronado, 3er anillo externo
Fecha: Marzo *Las fechas de las ferias están sujetas a modificaciones sin previo aviso.

En este evento se destaca lo mejor de la industria maderera en una muestra donde empresas del sector exhiben muebles, servicios, herramientas y todo lo relacionado con este material. Dentro de esta muestra se llevan a cabo concursos y actividades con profesionales del sector.

EXPOAUTO

Feria Automotriz

Ubicación: Avenida Roca y Coronado, 3er anillo externo
Fecha: Marzo *Las fechas de las ferias están sujetas a modificaciones sin previo aviso.

La feria automotriz de Santa Cruz reune a las principales concesionarias del país y presentan modelos y precios únicos de feria en 5 días de negocios y tecnología automotora. En este evento los visitantes conocen de primera mano, vehículos de todas las gamas, accesorios, materiales y todo lo relacionado a la industria.

FERIA DEL LIBRO

FERIA INTERNACIONAL DEL LIBRO DE SANTA CRUZ

Ubicación: Avenida Roca y Coronado, 3er anillo externo

ph: GAD SCZ

Es un encuentro literario y participativo donde se presentan libros, se desarrollan conversatorios, teatros, lecturas infantiles y actividades para toda la familia. En este evento el visitante encuentra una amplia variedad de material literario de diferentes géneros con una importante presencia de editoriales y escritores nacionales e internacionales.

EXPO REAL ESTATE

FERIA DE INVERSIONES INMOBILIARIAS

Ubicación: Avenida Roca y Coronado, 3er anillo externo. **Fecha:** Mayo*Las fechas de las ferias están sujetas a modificaciones sin previo aviso.

El evento donde desarrolladoras inmobiliarias y urbanizadoras presentan una amplia oferta de proyectos inmobiliarios de diferentes formatos y con precios exclusivos de feria. Dentro de esta feria se realiza el Congreso de Desarrollos e Inversiones Inmobiliarias.

AGROPECRUZ

FERIA AGROPECUARIA INTERNACIONAL DE SANTA CRUZ

Ubicación: Avenida Roca y Coronado, 3er anillo externo **Fecha:** Abril*Las fechas de las ferias están sujetas a modificaciones sin previo aviso.

La feria pecuaria más importante del país; se presentan animales de alta genética, remates de elite, juzgamientos internacionales. Esta es la plataforma por excelencia para potenciar la calidad de los ejemplares cruceños y para generar negocios entre empresarios ganaderos, contribuyendo notablemente a la economía de la región.

EXPOGRÁFICA BOLIVIA

FERIA INTERNACIONAL DE PRODUCTOS GRÁFICOS

Ubicación: Avenida Roca y Coronado, 3er anillo externo **Fecha:** Abril*Las fechas de las ferias están sujetas a modificaciones sin previo aviso.

Es el evento más importante del sector gráfico, donde se reunen empresas nacionales e internacionales, proveedores y visitantes interesados en potenciar e innovar en la industria gráfica. Este es el único punto de encuentro del mercado en el país y se realiza dentro de Bolivia Textil.

EXPOTELEINFO

EXPOSICIÓN INTERNACIONAL DE TELECOMUNICACIONES Y TECNOLOGÍAS

Ubicación: Avenida Roca y Coronado, 3er anillo externo **Fecha:** Junio/Agosto*Las fechas de las ferias están sujetas a modificaciones sin previo aviso.

En este espacio el visitante encuentra nuevos formatos de negocios, innovadoras propuestas de tecnología que transforman los negocios y sus alcances en beneficio de los diferentes participantes del mercado mientras que los exponen, educan y penetran en un mercado en continua expansión.

SPECIALTY COFFEE EXPO

Ubicación: Avenida Roca y Coronado, 3er anillo externo **Fecha:** Julio*Las fechas de las ferias están sujetas a modificaciones sin previo aviso.

Es un evento que reúne a profesionales de toda la cadena de producción de café en un ambiente donde se destaca lo mejor de esta industria. Los baristas más reconocidos del país y expositores cafeteros comparten con los visitantes en un ambiente de fraternidad, participación y negocios.

COMIC CON

FERIA INTERNACIONAL DE CÓMICS

Ubicación: Avenida Roca y Coronado, 3er anillo externo **Fecha:** Abril*Las fechas de las ferias están sujetas a modificaciones sin previo aviso.

Es el escenario donde la ''comunidad friki'' comparte concursos de cosplayers y atracciones vinculadas a esta temática. Esta es una gran exhibición donde se ofrecen revistas, objetos, computadoras y productos originales de personajes de la televisión, del cine y los juegos a escala mundial. Entre los expositores hay gente relacionada a los cómics, videojuegos, películas, coleccionismo, ilustración, música y otros ámbitos del mundo geek.

FESTIVAL DE VINOS Y QUESOS

Ubicación: Avenida Roca y Coronado, 3er anillo externo **Fecha:** Junio*Las fechas de las ferias están sujetas a modificaciones sin previo aviso.

Es un evento especializado que reúne a productores vitivinícolas, lácteos y de fiambres, además de representantes de bodegas nacionales e internacionales. Hay shows musicales, encuentros de negocios y lo mejor de expositores del rubro en un ambiente de fraternidad y celebración.

EXPOCRUZ

¡SÍMBOLO DEL DESARROLLO CRUCEÑO!

Ubicación: Avenida Roca y Coronado, 3er anillo externo

ph: Unitel

Expocruz es parte de la identidad de Santa Cruz. Es el símbolo del empresariado, de la fuerza productiva de Santa Cruz y de Bolivia, de los que trabajan e invierten, arriesgando, creyendo en el país y sus potenciacilidades. Se ha arraigado de tal manera en el consciente colectivo de la población, que todos esperan que llegue septiembre para disfrutar de él. Las noches de feria son una buena costumbre que a la par revelan el empuje de una región que en las últimas décadas se ha convertido en un verdadero motor económico, capaz de ponerse al hombro un país de 10 millones de habitantes como Bolivia. En sus diez noches de trajín, luces y comercio, Expocruz genera un movimiento económico que bordea los $us 100 millones. Por otra parte, el sector empresarial cuenta con la Rueda de Negocios como otro espacio de interacción que logra intenciones de negocios por al menos otros $us 200 millones más. Con todo ello, septiembre, mes en el que se desarrolla la feria, se ha convertido en un mes de verdadero dinamismo comercial, cuyo epicentro nacional está en el predio ferial asentado sobre la avenida Roca y Coronado. Esta feria multisectorial, una de las más completas de América Latina, es el escenario donde se reúnen todos los sectores productivos del país y de la región, logrando apreciar la voluntad del empresariado boliviano por seguir produciendo. La Expocruz juega un papel primordial ya que es la puerta que vincula a los productores con los potenciales compradores a través de la búsqueda de mercados, expansión y comercialización. Es la primera feria internacional y mayor centro de negocios de Bolivia afiliada a la Asociación de Ferias Internacionales de América (AFIDA) y a la Unión de Ferias Internacionales (UFI) con sede en París, máximas asociaciones gremiales a escala mundial de ferias y exhibiciones, que garantizan y respaldan la calidad y seriedad del evento.

ph: Unitel

En cuanto a sus orígenes y creación, comenzó en 1962 como una Feria Ganadera en el predio de la Facultad de Veterinaria de la Universidad Autónoma Gabriel René Moreno. En ese entonces el objetivo era mostrar los experimentos genéticos llevados a cabo por los estudiantes universitarios del último año. Luego, tras el éxito de la primera, la segunda versión de 1964 fue impulsada por destacados empresarios de la época que prestaron sus servicios y brindaron su apoyo, incluso arriesgando su propio capital, para ampliar la muestra y dar un carácter de negocio al evento.

ph: Unitel

En 1965, la tercera muestra ferial se amplió a más sectores económicos y se institucionalizó su organización. Se acordó la incorporación de los sectores de comercio, industria y artesanías, y se estableció un comité organizador, entre ellos la Cámara Agropecuaria del Oriente (CAO) y la Cámara de Industria, Comercio, Servicio y Turismo (CAINCO). Luego de realizada la cuarta versión de la muestra ferial en 1966, y debido a la gran demanda por parte de expositores, la CAINCO y la CAO se asociaron para adquirir un terreno destinado a un campo ferial con una extensión de 90,440 m2. Luego de dos años que tomaron las obras de acondicionamiento (limpieza del terreno, instalación de servicios básicos, y construcción de vías acceso), en 1968 se inaugura la quinta versión de la feria exposición de Santa Cruz adquiriendo ahora un carácter multisectorial e internacional con la participación de delegaciones de Argentina, Brasil, Chile y Alemania, a la par que aumentaba la participación expositores locales y del interior del país. La Fexpocruz y todo lo que se desarrolla a su alrededor, Rueda de Negocios, Turismo, servicios de Hoteles y Restaurantes, entre otros, significa para Santa Cruz y Bolivia un evento de suma importancia en términos de movimiento económico, y es, sin lugar a dudas, un símbolo del desarrollo y el espíritu emprendedor de hombres y mujeres visionarios que han venido consolidando un espacio para hacer negocios, generar riqueza e incrementar el bienestar. Esta es la verdadera faceta de la Feria Exposición que cada septiembre de desarrolla en Santa Cruz, y que ayuda a que Bolivia muestre una imagen positiva al mundo, como un referente de desarrollo empresarial.

ph: Unitel

PARQUE INDUSTRIAL

EL PRIMER PARQUE INDUSTRIAL DE BOLIVIA

Ubicación: Entre el cuarto y séptimo anillo , entre Av. Mutualista y Virgen de Cotoca
Atención: Horario de oficina

ph: GAD SCZ

Adelantándose previsoramente en muchos años al proceso industrializador; el denominado Parque Industrial "Ramón Darío Gutiérrez" ubicado en la zona noreste de la ciudad, se consolida como el primer y más grande parque industrial del país y se ha convertido en un referente industrial, que tiene la presencia de rubros manufactureros, agroindustriales, logísticos y servicios, encontrándose a la fecha un total de 807 industrias, 321 pequeñas y 486 medianas y grandes industrias. Esto la convierte en el epicentro de una gran actividad económica que genera puestos de trabajo y aporta al crecimiento económico del país. Inicio con una superficie de 962 ha., y actualmente se ha extendido a 1.031,56 ha. Entre una de sus principales ventajas de este parque es su ubicación estratégica, cerca de importantes vías de comunicación como la Carretera al Norte y el Aeropuerto Internacional Viru Viru. Esto facilita el acceso tanto a clientes nacionales como internacionales. Inició su construcción en el 1975, con el fin de atraer inversiones de origen interno y externo a este rubro dinamizador de la economía y concentrarlas en un área especial, dotándolas de todas las facilidades de infraestructura de transporte, energía, agua y alcantarillado, a costos mucho más bajos de lo que implicaría su dispersión desordenada en el centro y la periferia urbana.

TURISMO GASTRONÓMICO

Santa Cruz de la Sierra

ph: GAD SCZ

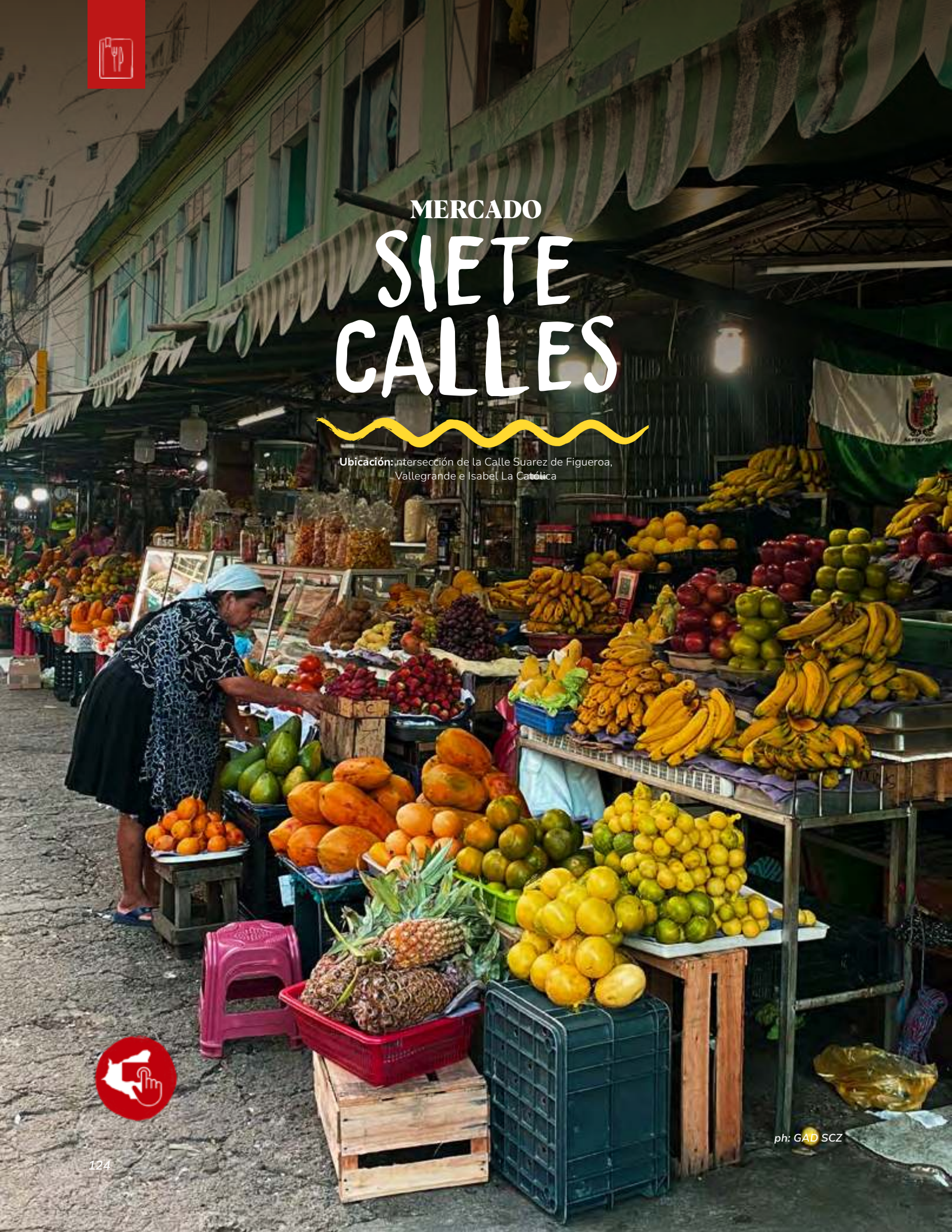

MERCADO SIETE CALLES

Ubicación: ntersección de la Calle Suarez de Figueroa, Vallegrande e Isabel La Católica

ph: GAD SCZ

Uno de los mercados más tradicionales de Santa Cruz, que forma parte de la identidad cruceña es el "Mercado Siete Calles"; en este mercado, podés encontrar abarrotes, comidas, bebidas, ropas, cosméticos y una inmensa variedad de telas. Son particularmente llamativos los puestos de frutas instalados sobre la calle Vallegrande. Otro aspecto interesante, es la oferta gastronómica que ofrece este mercado, como la comida vallegrandina, con los conocidos asaditos colorado, chicharrones, como también la oferta de su panadería en todas sus variedades, principalmente en las tardes. Asimismo, podés encontrar comida callejera tradicional, como los rellenos benianos, empanadas de quesos, de pollo, tamales curtidos y refrescos como el mocochinchi y somó, perfectos para combatir el calor en verano; y si sos amante de las pizzas, en una de las esquinas, podés degustar unas deliciosas y bastante conocidas pizzas al paso, mientras descansas de hacer tus compras.

En la misma zona se encuentran sandwicherías de larga tradición, como las "Gauchitas", que tienen una oferta en las mañanas y normalmente acaban sus productos antes del mediodía. Ya dentro del mercado, a la hora del desayuno, podés encontrar ollas de tojorí, baldes de tujuré, cuajadilla, jugos de fruta, salteñas, empanadas de queso. En resumen, cuando se trata de comida, el Mercado Siete Calles es muy conocido por intentar mantener y destacar los sabores de la cocina tradicional, aquella comida sencilla, sin muchos condimentos y con sabor de hogar.

ph: GAD SCZ

ph: GAD SCZ

En relación a su nombre, cuenta la historia que hace un siglo existía allí una séptima calle que arrancaba de la intersección de las tres calles Suarez de Figueroa, Vallegrande e Isabel La Católica, paralela a la prolongación de esta última, sin embargo, el dueño de los terrenos situados a ambos lados de la séptima calle, decidió cerrarla para consolidar su propiedad, sin que ninguna autoridad de la época se lo impida. Es por esta razón, que solo se puede enumerar seis calles que rodean al mercado.

En cuanto a su historia, se remonta a finales del siglo XIX y principios del XX. Para los años 50, empezaron a llegar los primeros comerciantes desde Vallegrande y Cochabamba. Aquellas personas comenzaron a vender sus productos en las arterias de tierra, en improvisadas chapapas (puestos precarios). Con el pasar de los años, las tierras fueron cubiertas por losetas y se construyeron puesto de material de construcción en donde actualmente trabajan. Algunos de los primeros centros comerciales o conocidos como shoppings fueron ubicados en esta zona y hasta hoy en día funcionan para oferta de vestidos y ropa para toda la familia, zapatos y demás artículos relacionados, bajo el formato de centros comerciales con pasillos internos y galerías adentro. Las familias acudían a estos puestos, para comprar el "estreno" (ropa) para las fiestas de navidad y fin de año. En definitiva, la zona del Mercado Siete Calles, más que un centro comercial, se ha convertido en la memoria colectiva de la ciudad.

LA CASA DEL CAMBA

Ubicación: Sucursal central, Av. Cristobal de Mendoza Barrio Petrolero N° 1365
Atención: Lunes a domingo: 11:00 - 22:30 Hrs.

ph: Casa del Camba

La historia de la Casa del Camba nace en Santa Cruz en 1986, cuando los esposos Juan Carlos Medina y Rosa Parada inauguraron su primer restaurante dedicado a la gastronomía regional. La pareja identificó que, en la ciudad no se disponía de un lugar que sirviera comida criolla de alta categoría. Por lo que, su restaurante se consolidó como uno de los mejores, gracias a la calidad y a la buena atención, y se convirtió en una parada casi obligatoria de los turistas. Con los años, La Casa del Camba se convirtió paulatinamente en un referente de la ciudad y fue modernizándose junto con ella. A sus ambientes llegaron músicos, actores, deportistas y autoridades de países de alrededor del mundo. El plato preferido es el majadito, que puede ser de charque o de pato, el primero se presenta tostado y el segundo batido. A este plato tradicional le sigue en popularidad el bufé típico que ofrece la posibilidad de elegir o combinar cuatro platos (majadito de pato, majadito de charque, keperí y el picante de gallina). Impulsados por su visión empresarial, en septiembre del 2009 inauguraron la "Casa del Camba Urubó", ubicada en una zona residencial y de gran crecimiento inmobiliario y económico de Santa Cruz. Esto marcó un hito en su historia, pues los catapultó como una empresa referente

ph: Casa del Camba

del rubro gastronómico, expandiéndose a otros departamentos del país a través de franquicias bajo el formato de sucursales "express" en supermercados y centros comerciales de Santa Cruz; Cochabamba, La Paz y El Alto. Asimismo, han firmado alianzas con otras empresas alimenticias para comercializar refrescos típicos de la región como chicha y mocochinchi en botellas.La Casa del Camba ha sabido mantener y preservar la cultura oriental gastronómica, posicionándose como un referente en la preparación y comercialización de los platos típicos de Santa Cruz. Así que si estás en la ciudad, tenés que probar su delicioso menú.

ph: GAD SCZ

ph: El Aljibe

El "Aljibe" abrió sus puertas en enero del 2009 y se trata de un proyecto gastronómico que combina lo más tradicional de la comida cruceña con la cultura, rescatando la gastronomía con identidad cruceña. Es un restaurante-museo donde, junto con lo más tradicional de los platillos típicos, se sirven recetas que se hallaban en proceso de extinción, que dan lugar a un menú que combina las preparaciones actuales como: Majao, Locro de gallina, Rapi al jugo y Keperi al horno, con los sabores rescatados de nuestro pasado como el Pastel de gallina, Sopa Tapada, Capirotada, Almondrote, Locro Carretero, Pipian, entre otros. El menú cuenta con seis variedades de sopa, trece variedades de platos fuertes, cuatro tipos de postre, cuatro de masitas típicas, varios refrescos y bebidas según la temporada. Se encuentra ubicado en el centro histórico de la ciudad, en una antigua casona que fue construida en 1880. Los ambientes han sido restaurados y albergan infinidad de objetos de antaño. Esta casa perteneció al alcalde Guillermo Menacho y a su esposa, Bella Carrillo, la primera diputada cruceña. El nombre que lleva este restaurante hace referencia a un depósito subterráneo donde se recoge y conserva el agua de lluvia o también la que se hace llegar de un río o de un manantial y en sus instalaciones se halla en el centro del patio un aljibe que nunca dejó de funcionar; esta particularidad fue el que le dio nombre al restaurante. Otra de las características llamativas del "El Aljibe" es que la cocina está a la vista de todos para que puedan asegurarse de la limpieza y calidad de los platos, y aun así no se perciben olores ni ruidos. Los propietarios han sabido aprovechar el espacio. Cuenta con seis ambientes: en el primero, además de mesas, hay productos artesanales como camisas chiquitanas, collares ayoreos y anillos de chonta que están a la venta. Además, venden comestibles como manjar blanco, mermeladas, tablillas, zucumbé y otros licores. Los otros ambientes tienen inspiración chiquitana y ayorea, y en ellos se pueden apreciar tallados, adornos y materiales de estas culturas. Además existe un salón con recuerdos de Gladys Moreno, la cantautora más importante de la musica cruceña donde se podrán ver diversos objetos personales.

ph: El Aljibe

ph: La Pascana

Si querés tener una vista panorámica de la ciudad mientras compartís algún platillo para comer, tenés que visitar "La Pascana" by Senses, que desde su terraza tendrás una de las mejores vistas de la ciudad. También encontrarás en otras de sus áreas, un café para disfrutar de un vaso de mocochinchi o de somó, además de horneados y comidas típicas y un restaurante gourmet. Estos espacios son parte de las áreas sociales abiertas al público del Hotel Boutique cinco estrellas, "La Pascana Senses". De acuerdo a sus gestores, este edificio se estructura en su contexto, tiene muchísima relación con la catedral y con las estructuras envolventes de la plaza, la galería y el estilo colonial, internamente explota el neomodernismo, pero respeta la arquitectura cruceña. De acuerdo a los historiadores, este histórico lugar, a finales del siglo XIX sirvió de barricada en la llamada Revolución de los Domingos y en 1920, se inaugura el "Plaza Hotel", y luego el Gran Hotel Centenario. En la década de 1940, el lugar pasa a manos de Carlos Amelunge, que la amplía con una terraza al aire libre y la denomina "La Pascana", que se convierte en punto tradicional de encuentro de todos los cruceños con bailes, fiestas, reuniones de deportes y de políticos. Su época de mayor esplendor fue en 1960, cuando era el lugar típico para la lectura de los populares bandos de carnaval y también escenario para grandes artistas nacionales e internacionales como Gladys Moreno y Los Panchos. Pasado los años, este punto de encuentro paso a la modernidad y ahora es el edificio de dos plantas, con espacios comerciales y turísticos, albergando en sus instalaciones un hotel, una cafetería y un restaurante. Pese a ello, sigue siendo un imán para todo aquel que quiere pasar un momento en familia o amigos. "La pascana" cambia, pero perdura a pesar de los cambios, en las distintas épocas es un sitio de reunión de los cruceños y de los turistas referencial de Santa Cruz.

ph: La Pascana

COMIDA TÍPICA
SUÁREZ

Ubicación: Calle Tao Nº 152 / Av. Cristobal de Mendoza, 2do anillo, entre Av. Alemana y Av. Beni.
Atención: Lunes a Viernes 11:30 a 23:00 Sábado y Domingo 10:00 a 00:00

Ubicado en la zona de los "agachaos" del Avión Pirata, el ahora restaurante 'Comidas típicas Suárez' es uno de los lugares más populares de la ciudad, si de comida criolla se trata. Este restaurante empezó en San Ramón, un municipio del departamento de Santa Cruz, a 175 km de la ciudad en el año 1978 y tiempo después se trasladaría a la ciudad de Santa Cruz. Comenzaron preparando milanesas y bifes, pero los consumidores fue tantos que abrieron un restaurante más grande para poder ofrecer una mayor variedad de platos y fue de esta manera que nació "El boliche de Arturo", un lugar donde hacían alto las flotas que iban al Beni, a Concepción o a San Ignacio, que, de acuerdo a sus fundadores, llegaron al restaurante personalidades como el profesor Noel Kempff Mercado, Jorge Tuto Quiroga y el general Hugo Banzer. Cuando se trasladaron a Santa Cruz, alquilaron en la zona del Avión Pirata, conocida como los "agachaos". Instalados en este lugar, el restaurante se popularizó bajo el nombre de "Comida Típica Suarez". En los últimos años han abierto nuevas sucursales bajo el formato de franquicia en distintos puntos de la ciudad y patios de comida. En su menú podés encontrar desde el tradicional majao hasta el famoso coto relleno, como también rapi al jugo, picante, ají de lengua, bife y milanesa.

HAMBURGUESERÍA RICS BURGER

Ubicación: Calle Cuellar, entre Calle Libertad y 24 de Septiembre
Atención: Lunes a sábado: 17:00 a 22:00 horas

Si de hamburguesas tradicionales se trata, las "Ric´s Burger" son la opción, que desde el 1980 mantienen su sabor de siempre, único, rico y como hecho en casa.

POLLOS CHUY

Ubicación: Calle Monseñor Salvatierra #267
Atención: Lunes a Viernes 11:30 a 14:30 18:00 a 23:00 Sábado y Domingo 11:30 a 23:00

En abril del 1977, María Luisa Landívar de Justiniano, cariñosamente conocida como Chuy abre el tradicionalmente conocido "Pollos Chuy", en su domicilio particular de la calle Manuel Ignacio Salvatierra, frente a la Iglesia San Roque, convirtiéndose en el primer local de lo que sería años después en una empresa gastronómica consolidada en Santa Cruz y en el país. La sucursal de la calle Manuel Ignacio Salvatierra sigue en funcionamiento y muchos de los comensales de los pollos a la broaster aseveran que allí es donde encuentran el mejor y más auténtico sabor del "Pollo Chuy". ¡Tenes que probarlo!

HELADERÍA CABRERA

Ubicación: Calle Ballivián casi esq. Calle La Paz.
Atención: Lunes a domingo: 7:00 a 22:00 horas

En los años setentas la Sra. Lidia Sanguino Vda. de Cabrera inicia la producción artesanal de distintos jugos de frutas tradicionales de la región que se comercializaban en la Calle Ballivián casi esq. Calle La Paz. Posteriormente, en la década de los ochentas el proceso se fue industrializando y mejoró la comercialización a través de carros de madera ubicados en distintos puntos de la ciudad. En los años noventa, se amplía la empresa con la producción de helados y la comercialización hacia provincias y otros departamentos del país. Actualmente es una empresa robusta llamada "Industrias Alimenticias Cabrera", con una planta de producción instalada en el Parque Industrial de la ciudad de Santa Cruz de la Sierra, con una oferta diversificadas de productos, que van desde helados en diferentes presentaciones, sabores y combinaciones a los típicos refrescos naturales y pulpas de frutas. Podes encontrar sus productos en su tradicional primer punto de venta, en la calle Ballivián, pero también en diferentes puntos de la ciudad, patios de comida y tiendas de barrios.

HAMBURGUESAS TOBY

Ubicación: Av. Cristóbal de Mendoza 2do Anillo
Atención: Lunes a viernes: 11:30 a 23:00 horas

¿Quién no comió una Toby? La mayoría de las personas que viven en Santa Cruz ha probado alguna vez las tan tradicionalmente conocidas hamburguesas "Tobby", cuya primera preparación se hizo en un pequeño local de la calle Sucre el 11 de octubre de 1981, y desde entonces su fama y sabor se ha extendido por los barrios cruceños llegando a estar presente en otros departamentos del país, centros comerciales, patios de comidas en formatos adaptados a los tiempos modernos, manteniendo su sabor único característico. ¡Si estás buscando probar una hamburguesa local y tradicional, tenés que probar esta hamburguesa!

ZONA DE LOS AGACHADOS DEL AVIÓN PIRATA

Ubicación: Zona del Avión Pirata, Calle Tao, primer anillo

La zona del Avión Pirata y el de las Petillas, ubicados por el primer anillo, en el sector noreste de la ciudad, se encuentra el tradicionalmente conocido lugar de los "agachaos", que, de acuerdo a la jerga camba, un agachao es un puesto de venta de comida con mesas y sillas instaladas en la acera de la calle, donde los comensales para evitar ser reconocidos, antiguamente agachaban la cabeza junto al plato y comían muy rápido. También, puede referirse al hecho de que estos puestos de comida no siempre contaban con las comodidades para sentarse y degustar los alimentos, por lo que se comía agachado e incómodo. Sea cual fuese la razón, lo cierto es que esta zona se quedó con el nombre de los "agachados" y se ha convertido en un referente de la gastronomía típica cruceña, en la cual podés encontrar una oferta variada de platos típicos como patasca, majao, picante de gallina y de lengua, rapi, cogote relleno, locro y Keperí.

MERCADO LOS BOSQUES

Y SU OFERTA GASTRONÓMICA DE PESCADOS

Ubicación: Av. Doble Vía La Guardia, Quinto Anillo y Calle Los Bosques **Atención:** Lunes a viernes: 11:30 a 23:00 horas

Si de variedad de pescados frescos, deliciosos y a la parrilla se trata; el mercado "Los Bosques" es el lugar indicado; aquí encontrarás una gran selección de pescados locales, como el pacú, surubí, sábalo, paiche que son perfectos para asar a la parrilla y deleitar tu paladar. Los puestos están con las parrillas y los pescados asándose a la vista de los comensales para poder elegir que pescado servirse. En relación a la guarniciones, podrás degustar los pescados con papa, mote y el infaltable ají. No perdás la oportunidad de vivir una experiencia gastronómica tradicional en el mercado "Los Bosques" y degustar los sabores auténticos de estos pescados. No te vas a arrepentir. ¡Buen provecho!

LAS TRADICIONALES NEGRITAS

DEL MERCADO LOS POZOS

Ubicación: Mercado los Pozos, Calle 6 de Agosto y Calle Quijarro

Las conocidas "Negritas de Mami Pitu" del mercado Los Pozos tienen un sabor inigualable que perdura en el tiempo y que atrae a sus fieles comensales a su pequeña caseta del mercado "Los Pozos", en busca de sus tradicionales negritas (morcillas), acompañadas de yuca hervida, ají de locoto y cebolla verde. Además se ofrece sándwich de chola, asadito colorado y escabeche beniano. Doña Petrona Hurtado, empezó su negocio hace varias décadas atrás, a las que involucró a sus nuera y nietas. Actualmente es uno de los lugares más emblemáticos y de los más visitados del tradicional centro de abastecimiento, ubicado en el casco viejo de la ciudad. La atención en el mercado comienza a las 6:30 de la mañana, las negritas al igual que el resto de los platos llegan bien calientes y recién salidos de la cocina. Doña Petrona, su nuera y nietas se levantan todos los días de madrugada a trabajar. Doña Petrona sigue al mando de la preparación de las negritas junto a su nuera, quien se encarga

de venderlas en el mercado. Sus nietas preparan asadito colorado, escabeche, sándwich de chola y escabeche beniano. Ellas venden en dos puestos que están en el sector de carnes. Ante la demanda de sus clientes, tuvieron que agrandar el menú, preservando el inigualable sabor que caracteriza a sus platillos. Degustar el menú de las "Negritas de Mami Pitu", es una experiencia gastronómica que no te podés perder estando en la ciudad de Santa Cruz de la Sierra.

RESTAURANT LA BARCA

Ubicación: Av. Cristóbal de Mendoza 2do Anillo
Atención: Lunes a viernes: 11:30 a 23:00 horas

"La Barca", un restaurante ubicado en la céntrica zona Siete Calles, fue inaugurado el año 1960 por Micaela Pérez y su esposo Felix Zeballos. Actualmente quienes lo administran son Florinda Zeballos (hija de ambos) y su esposo Jorge Caelo. Los propietarios afirman que uno de los motivos que hicieron que La Barca perdure en el tiempo y sea tan cotizado por antiguos y nuevos clientes, es la rapidez en la atención, la cantidad de comida que lleva cada plato y su buena sazón."La Barca" ha sido el lugar de encuentros políticos al ser uno de los primeros establecimientos dedicados a la gastronomía típica, las visitas de reconocidas personalidades de Santa Cruz eran constantes y siempre dejaban alguna historia que contar en un futuro.

SNACK LA LE LI LO

Ubicación: Calle Suárez de Figueroa Nº 20
Atención: Lunes a Viernes 07:30 a 20:00

Sabor y tradición, es lo que vas a encontrar en tu visita al Snack "La Le Li Lo Lu", un restaurante de comida rápida tradicional que ha sabido ganarse la preferencia de los cruceños con sus asaditos , revueltos de hígado y rebozados de panza y lengua, que se caracterizan por ser deliciosos y económicos. La actual propietaria, heredó de su madre, la fundadora, la receta estrella de la preparación de los asaditos que no varió en los últimos 30 años. Antes de abrir este snack, tenían un kiosco en el Estadio Ramón "Tahuichi" Aguilera de la ciudad, que a pedido de sus fieles comensales, en el 1990 se animaron a dar el paso de abrir un restaurante. En 2008 se mudaron a la calle Suárez de Figueroa, donde a pesar de la expansión, han tratado de mantener la esencia de La, Le, Li, Lo, Lu. Un aspecto que los caracteriza es que la atención es rápida y que los clientes se van satisfechos no solo con el sabor de la comida, sino con la atención familiar que se les brinda.

MERCADO NUEVO

Ubicación: Esq. Calle Sucre y Cochabamba
Atención: Lunes a domingo: 06:00 a 20:00 Hrs.

A pesar del nombre, el "Mercado Nuevo", es uno de los mercados más antiguos en Santa Cruz de la Sierra, el cual funciona desde 1943. Aunque fue remodelado recientemente, mantiene ese aire colonial y ceremonioso que lo caracteriza. Es el lugar ideal para degustar algunos de los sabores más tradicionales de la ciudad. Masaco, cuñapé frito, majadito batido, locro o el famoso revuelto de hígado, acompañado de un mocochinchi o un refresco de tamarindo, son solo una pequeña lista de las delicias que se pueden encontrar. En este mercado, los diferentes puestos son atendidos por diversas generaciones de familias quienes han heredado las recetas de sus abuelos. Un lugar donde la tradición se respira y se saborea todos los días.

MARIO HÍGADO

Ubicación: Esq. Calle Sucre y Cochabamba
Atención: Lunes a domingo: 06:00 a 15:00 Hrs.

"Mario Hígado" es el apodo que le pusieron sus clientes a Mario Cortez Suárez, aludiendo al "revuelto de hígado", platillo que él prepara y que lo ha convertido en un referente de la gastronomía popular cruceña. Tiene su puesto de comida en el "Mercado Nuevo", ubicado en Calle Sucre Esq. Cochabamba. Además de su famoso plato de "revuelto de hígado", también ofrece almuerzos, variedades de sopa y segundos. Se jacta de tener entre su clientela a expresidentes bolivianos, actuales parlamentarios, figuras del deporte y hasta reinas de belleza.

El Orquideario" es un Jardín de Orquídeas y Cafetería; un lugar único que mezcla la gastronomía, la naturaleza y la cultura, crea un ambiente acogedor y lleno de vida. En "El Orquideario", podés disfrutar de una amplia variedad de opciones dulces y saladas, desde el clásico tres leches hasta el majadito y la tarta de ricota, pasando por deliciosas tortas, brownies, flanes y tartas. Además, disfrutás de un buen café, té o bebida fría mientras te relajas en el jardín y admirás las hermosas orquídeas que rodean el lugar.

En las instalaciones del "Club 24 de Septiembre", se ofrece almuerzo con un menú de comida tradicional el cuál podés degustar en familia y con amigos. Más allá del menú, la verdadera experiencia es poder contemplar por los interiores este emblematico edificio con ambiente de antaño. El almuerzo podrás acompañarlo de música tradicional que acostumbra ponerse como ambiente. Toda una experiencia con la excusa de almorzar en plena Plaza 24 de Septiembre.

Se describen como un restaurante "a la bonne franquette" abierto desde 1989. Tienen un ambiente hogareño, acogedor, relajado al más puro estilo franco-suizo, donde podés disfrutar con amigos presentaciones musicales y disfrutar deliciosa comida internacional.

La Avenida Uruguay es un lugar tradicional cuando de carnes y restaurantes se trata; ubicada en pleno primer anillo de la ciudad, es un sitio al cual diversas generaciones de cruceños han asistido para deleitarse de un buen churrasco, un buen bife de chorizo, un buen cuadril, y los infaltables pacumutos de codorniz, acompañadas de deliciosas guarniciones y salsas caseras. Si bien la oferta culinaria se ha diversificado, ubicándose en diferentes puntos de la ciudad, la Avenida Uruguay es la zona referente de "churrasquerías", siendo un sitio de encuentro para celebrar cumpleaños, reuniones y agasajos en compañía de un buen churrasco y con una atención al buen estilo cruceño. En esta zona encontrarás una variedad de opciones para todos los gustos y bolsillos. Si estás en la ciudad, no dudés en visitar esta zona. ¡Buen provecho!

AVENIDA SANTOS DUMONT Y VELARDE

Ubicación: Avenida Santos Dumont, entre segundo y cuarto anillo y Avenida Velarde entre primer y segundo anillo.

ph: GAD SCZ

La “Zona Sur” de la Avenida Santos Dumont, entre segundo y cuarto anillo, es uno de los centros gastronómicos y de entretenimiento de la ciudad, con opciones como pastelería, heladerías, churrasquería, comida rápida; así como también algún otro local de entretenimiento como discotecas. Esta avenida principal, que conecta el centro con el sur de la ciudad, se ha convertido en un punto de encuentro para los habitantes de la zona sur de la metrópolis de Santa Cruz, ya que, en el segundo anillo, por ejemplo, se encuentra uno de los primeros y principales centros comerciales como el “Megacenter”. El nombre de la avenida hace referencia al “padre de la aviación” Alberto Santos Dumont, por lo que no es casualidad que en esta misma avenida se encuentre el Colegio Militar de Aviación y el Aeropuerto “El Trompillo”. Asimismo, a continuación de la avenida Santos Dumont, del segundo anillo hacia el primero, se encuentra la “Avenida Velarde”, que igualmente tiene una importante oferta de establecimientos gastronómicos como comida china, bufets y franquicias de comida internacional, como pizzas, cafés, bebidas y otros. Además, en esta avenida, se encuentra ubicada la “Plazuela Blacutt”, que, por las noches, encontrarás opciones de comida rápida al paso, como hamburguesas, lomitos, panchitos y los afamados choripanes.

AVENIDA BENI Y ALEMANIA

Ubicación: Av. Beni y Av. Alemania, entre segundo y cuarto anillo

Las Avenidas Beni y Alemania entre segundo y tercer anillo, se han convertido en una de las zonas de la ciudad con opciones gastronómicas para satisfacer los diferentes gustos y antojos de los comensales. Podrás encontrar restaurantes de comida marina, con exquisitos platillos de mariscos, ceviches, pescados a la plancha. Si sos más de hamburguesas, encontrarás locales que ofrecen diferentes tipos de hamburguesas para todos los gustos. Si lo tuyo es la carne, también encontrarás churrasquerías que satisfagan tus deseos. No podemos olvidar los clásicos pollos a la brasa o la broaster, acompañados de papas fritas, ensaladas y salsas tradicionales, siendo una opción ideal de comida rápida y sabrosa. En resumen, no dudes en visitar esta zona y deleitarte con todas las opciones gastronómicas que tiene para ofrecerte. ¡Buen provecho!

HOTELERÍA

Santa Cruz de la Sierra

ph: Hotel Camimo Real, Hotel Boutique D´Castilla, Los Tajibos, Hotel Marriott, Novotel y Alfonsina Hotel Boutique.

Santa Cruz de la Sierra cuenta con la mejor infraestructura hotelera de Bolivia. La variedad y amplia capacidad de su oferta, ayudada por otros factores, han posicionado a la ciudad como un destino estratégico a nivel regional para la realización de eventos internacionales, congresos y convenciones. La oferta turística de Santa Cruz es tan amplia que la convierte en el epicentro de la industria del turismo del país. En este sentido, el sector hotelero es uno de los rubros que constantemente realiza inversiones significativas, ya sea para mantener los estándares de calidad de acuerdo a las exigencias y estándares internacionales, así como también ofrecer servicios de vanguardia. Por ello, en los últimos años, en la ciudad de Santa Cruz de la Sierra, ha sido la sede de apertura de grandes cadenas hoteleras globales como el Marriot, Hampton By Hilton y Accor. Así también, se encuentran hoteles cruceños que tienen una destacada trayectoria como lo son el Hotel Los Tajibos, Camino Real, Hotel Cortez, Yotaú, entre otros.

ph: Los Tajibos

Los Tajibos Hotel, abrió sus puertas un 26 de febrero de 1975 y desde ese momento, ha sido testigo y protagonista del desarrollo de Santa Cruz y Bolivia. Inició operaciones con una estructura innovadora para la época, el hotel contaba en ese entonces, con ochenta habitaciones, en la actualidad se han convertido en 208 con una variedad de seis categorías para dar la comodidad a sus huéspedes. Executive, Pool View, Club Ejecutivo, Junior Suite, Executive Suite y Suite Presidencial. El crecimiento y experiencia durante todos estos años han permitido al hotel ser referente de la hospitalidad cruceña. Se encuentra distribuido sobre una superficie de 6 hectáreas con exuberante vegetación, en la zona de Equipetrol, al norte de la ciudad. Con el paso de los años Los Tajibos Hotel se ha caracterizado por marcar tendencias, tanto en el rubro de la hotelería como también en la innovación en gastronomía de alta cocina y eventos, con una infraestructura única con espacios amplios y horizontales, rodeados de naturaleza que permiten a los huéspedes y visitantes sentirse como si estuvieran fuera de la ciudad. A finales de 1997, se inauguró el Centro de Convenciones "El Conquistador", uno de los más grandes e imponentes del país, el cual cambió para siempre la manera de organizar eventos en Bolivia, ya que se trata del mayor centro de convenciones dentro de un hotel en el país. Por la parte gastronómica, Los Tajibos cuenta con 3 restaurantes propios: Jardín de Asia inaugurado el 2007, Piegari; franquicia argentina inaugurada el 2014 y La Terraza, remodelada el 2017. En ese mismo año, el hotel dio un paso muy importante en su historia y la de Santa Cruz. Modernizó su ingreso principal inspirado en el desarrollo cosmopolita de la ciudad. El nuevo lobby es un reflejo de la modernidad, globalización, elegancia y competitividad que se vive en el departamento. Los Tajibos es, sin duda, el hotel emblemático de Santa Cruz, el que define la personalidad de la región, con su verdor, frondosos árboles en su interior, corredores abiertos, canto de pájaros, y agua por todas partes. Cuando se inauguró hace casi 40 años, ya apuntaba a ser un hotel de primera por su ubicación y su estilo apropiado para el clima y con el correr del tiempo obtuvo de manera inobjetable sus cinco estrellas. La reina Sofía, jefes de Estado, políticos, artistas, se alojaron en las habitaciones de este tradicional hotel.

LOS TAJIBOS

A TRIBUTE PORTFOLIO HOTEL

Ubicación: Tercer Anillo Interno, Esquina Avenida San Martín N° 455
Atención: 24 Horas



ph: Los Tajibos

CORTÉZ

Ubicación: Avenida Cristobal de Mendoza N° 280

CAMINO REAL

Ubicación: Av. San Martín, Cuarto Anillo

MARRIOT

Ubicación: 4to Anillo y Av. San Martin S/N entre Radial 23 y Av. Las Ramblas

TAOS

Ubicación: Calle Pablo Sanz N° 9 Zona Equipetrol

Condominio

YOTAÚ

Ubicación: Av. San Martin N° 7,
Zona Equipetrol

SWISSOTEL

Ubicación: Av. La Salle Edif. Blu Costanera
N° 4500

CASA BLANCA

Ubicación: Av. Marcelo Tercero N° 205
Zona Equipetrol

NOVOTEL

Ubicación: Av. Roca y Coronado S/N
Zona Fexpocruz

Hotel Boutique
SENSES

Ubicación: Calle Rene Moreno N°247

TORRE

Ubicación: Av. El Trompillo N° 478 2do anillo

OSHO

Ubicación: Av. Cristobal de Mendoza S/N
Esq. C. Suarez Arana

Hotel Boutique
ALFONSINA

Ubicación: Calle Alfonsina Storni #12

Condominio
BUGANVILLAS

Ubicación: Av. Roca y Coronado Nº 901
Zona Fexpocruz

DELFINES

Ubicación: C. Dr. Pablo Sanz Nº 29, Entre Av. San Martin y Calle Dr. Victor Pinto

ARENAL

Ubicación: Calle Beni Nº340

Hotel Boutique
COSMOPOLITANO

Ubicación: C. Pari Nº 70, Entre C. Rene Moreno y C. Independencia

Hotel Boutique

KUSINITANA MISIONAL

Ubicación: Calle Independencia Esquina Ingavi N° 151

PLAZA 24

Ubicación: Calle Antonio Vaca Diez Esquina 24 de Septiembre N° 19

Suites Apart Hotel

TERRANOVA

Ubicación: 7mo nillo Avenida Cristo Redentor

Apart Hotel

MAI SUITES

Ubicación: Calle Los Pinos N° 522 Zona Sirari

Hotel Boutique

D'CASTILLA

Ubicación: Avenida Radial Castilla N° 3587
Barrio Las Palmas

CHAIRU

Ubicación: Calle Flamboyanes N° 137
Esquina Los Lirios

Apart Hotel

HOUSE INN

Ubicación: Calle Colon N° 643

HAMPTON

by Hilton

Ubicación: Avenida San Martin Esquina Calle
E Norte, Equipetrol

COTOCA

COTOCA

Provincia: Andrés Ibañez
Fundación: Aunque no se tiene registro alguno de su fundación, esta población surge a partir de la construcción y bendición del templo, el 15 de diciembre de 1799; lugar donde fue encontrada la imagen de la Virgen de Cotoca.

CLIMA

La temperatura máxima promedio es 29° C, principalmente en época seca desde los meses de agosto hasta diciembre, considerando que enero hasta marzo son épocas de lluvia.

DATOS GENERALES

Declarado "Patrimonio Cultural y Religioso de Bolivia" en el año 2003.

DATOS GEOGRÁFICOS

Ubicación: 20 kilómetros hacia el este de la ciudad de Santa Cruz de la Sierra.

Coordenadas: 17°45'14"S 62°59'49"O

Superficie: 606 km²

Altitud: 350 m.s.n.m.

DATOS DEMOGRÁFICOS

Gentilicio: Cotoqueño (a)
Población: (2023)[1]: 112.749 habitantes
Densidad: (2023): 186 hab./Km²

ECONOMÍA

Economía[2]: Las actividades económicas más importantes son manufactura y pecuario, que de acuerdo al Valor Bruto de Producción (VBP) del municipio representan el 48.3% y 23.57% respectivamente.

Sobresalen la agricultura, ganadería, caza, pesca y silvicultura. En la agricultura destacan los cultivos de algodón, soya, maíz, yuca, plátano y caña. La cerámica de Cotoca se caracteriza por su uso decorativo. Así mismo, tiene varias industrias como la fábrica de fierro de construcción y carretillas, fábrica de lonas, fábrica de tubos para electricidad, planta envasadora de leche y yogur. El turismo es otra fuente de ingresos para la población, sobre todo el turismo religioso por ser santuario de la Virgen de Cotoca[3].

Valor Bruto de Producción (VBP): 448 MM Bs.

---

[1] Encuesta de Estimación Poblacional de Santa Cruz 2023. Instituto Cruceño de Estadística
[2] Mapa de Complejidades, BDP 2019
[3] PTDI del Municipio de Cotoca 2015 – 2019

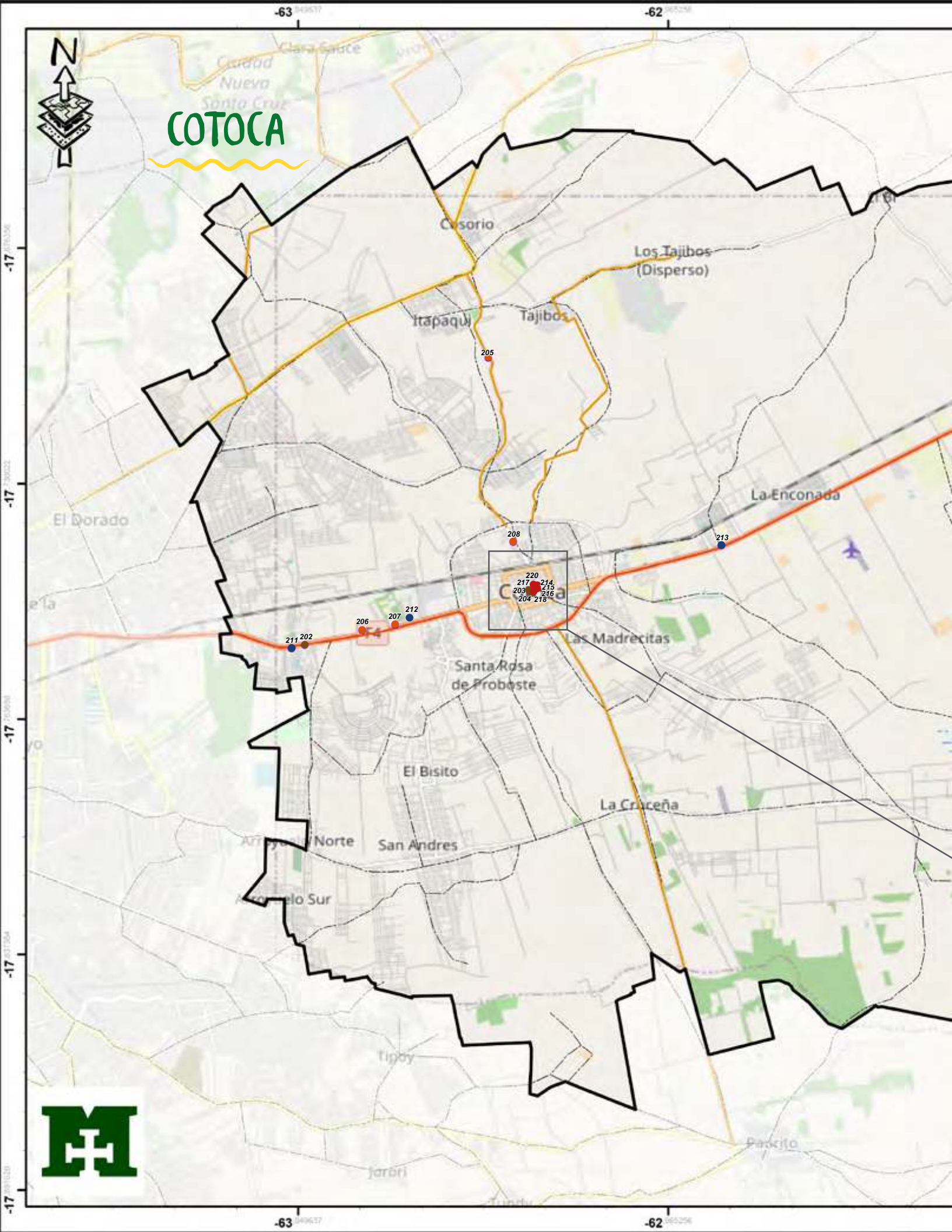
COTOCA
N
-63
-62
-17
Ciudad Nueva Santa Cruz
Clara Gaúce
Casorio
Los Tajibos (Disperso)
Itapaqui
Tajibos
205
208
213
La Enconada
El Dorado
220
217
214
215
203
216
204
218
Cotoca
212
207
206
211
202
Las Madrecitas
Santa Rosa de Probeste
El Bisito
La Criceña
Norte
San Andres
Arroyo del Sur
Tipoy
Jarbri
Pascito

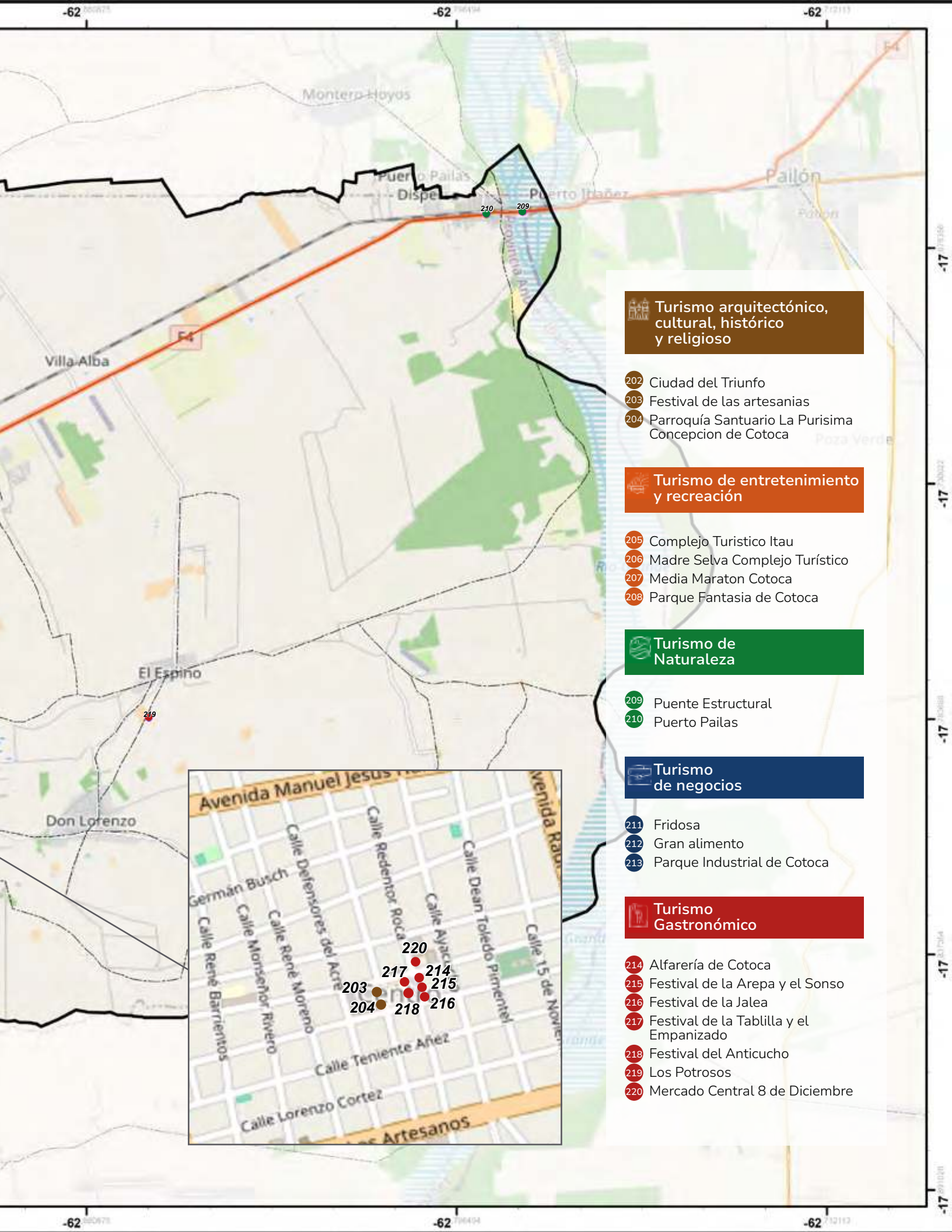

Turismo arquitectónico, cultural, histórico y religioso

- 202 Ciudad del Triunfo
- 203 Festival de las artesanias
- 204 Parroquía Santuario La Purisima Concepcion de Cotoca

Turismo de entretenimiento y recreación

- 205 Complejo Turistico Itau
- 206 Madre Selva Complejo Turístico
- 207 Media Maraton Cotoca
- 208 Parque Fantasia de Cotoca

Turismo de Naturaleza

- 209 Puente Estructural
- 210 Puerto Pailas

Turismo de negocios

- 211 Fridosa
- 212 Gran alimento
- 213 Parque Industrial de Cotoca

Turismo Gastronómico

- 214 Alfarería de Cotoca
- 215 Festival de la Arepa y el Sonso
- 216 Festival de la Jalea
- 217 Festival de la Tablilla y el Empanizado
- 218 Festival del Anticucho
- 219 Los Potrosos
- 220 Mercado Central 8 de Diciembre

SANTUARIO DE LA

PURÍSIMA CONCEPCIÓN

DE COTOCA

Ubicación: Plaza principal 8 de diciembre, entre Bolivar y Santa Cruz
Atención: Lunes a viernes: De 6:45 - 12 Hrs y de 14:00–20:00 Hrs.
Sábado: 6:45 a 20: 00 Hrs. Domingo: 6:30 a 20:00 Hrs.

ph: GAD SCZ

Conocido como el Santuario más importante de todo el oriente cruceño y donde se encuentra su Patrona, La Virgen Purísima Concepción de Cotoca. Este atractivo turístico, situado a 17 kilómetros de Santa Cruz de la Sierra y catalogado como uno de los lugares más visitados en la región, recibe alrededor de medio millón de habitantes entre el 7 y el 15 de diciembre de cada año. La historia de la devoción a la mamita de Cotoca se remonta al siglo XVIII. La leyenda cuenta la historia de tres esclavos mulatos que vivían en la hacienda Cortéz. Una noche, los esclavos fueron acusados de asesinar al capataz y por tal motivo, huyeron hacía el río Grande buscando resguardarse en la Chiquitania. Estando en medio de la nada, hallaron un pequeño refugio en el cual pudieron calentarse al calor del fuego. En busca de leña para su pequeña fogata, tropezaron con un tronco que, al ser golpeado por el hacha, sonó hueco. Los esclavos asombrados, notaron que del trozo de madera desprendía un destello y al observar con cautela, se encontraron con un rostro moreno que los miraba desde el interior.

ph: GAD SCZ

Asombrados y en plegaria, le pidieron a la imagen que les salvara la vida. Tanta fue su admiración que, pese al peligro, regresaron a la hacienda para contarle a su madre lo sucedido llevando con ellos la imagen sagrada. Al llegar descubrieron que el verdadero autor del crimen había confesado y ahora eran libres. Aquel milagro les había regalado una oportunidad y ahora tenían la misión de contar a todos la sobre esta majestuosa aparición, que con su amor cuidaba de los desamparados. No fue hasta que la hija del dueño de la Hacienda Cortéz, después de muchos años de tener la imagen en su poder, la entregó a Lorenza, madre de los mulatos, quien la pidió para tenerla como su devota y compañera. La mamita de Cotoca se hizo tan famosa por sus milagros que, en 1799 el deán Toledo Pimentel solicitó licencia al obispo Ochoa, residente en Punata, para la construcción de una parroquia. Esta parroquia es el hogar de la mamita de Cotoca, un santuario que día tras día, es visitado por los creyentes, quienes con fe y devoción, al encender una vela blanca, piden la bendición y protección de su patrona.

ph: Mystic Illustration y Fotografia

ROMERÍA

A COTOCA

Ubicación: Av. 4to anillo Virgen de Cotoca, Santa Cruz de la Sierra a Av. Santa Cruz, Cotoca

ph: El Deber

En Cotoca, cada año se lleva a cabo un evento de fe y devoción que atrae a miles de peregrinos: la Romería a Cotoca. Este evento religioso, profundamente arraigado en la tradición y la historia del departamento, ofrece una experiencia única para aquellos que buscan conocer la espiritualidad y la riqueza cultural de la región. Cada año, los fieles recorren 14 kilómetros desde el cuarto anillo de la ciudad de Santa Cruz de la Sierra, en busca de protección y para expresar gratitud a su patrona, la Mamita de Cotoca. Se estima que alrededor de medio millón de personas visitan el santuario a lo largo de la temporada de peregrinación. A través del tiempo, la romería ha evolucionado, enriqueciéndose con nuevas tradiciones y costumbres, pero su esencia sigue siendo la misma: rendir homenaje a la Virgen de Cotoca y renovar el compromiso de los devotos.

ph: El Deber

ph: GAD SCZ

El evento comienza aproximadamente a las cuatro de la tarde del 7 de diciembre, cuando miles de peregrinos emprenden un viaje desde distintas partes de Santa Cruz e incluso de Bolivia, caminando durante horas para llegar a los pies del santuario. Muchos llevan consigo ofrendas, velas y flores para honrar a la Virgen y solicitar su intercesión. Desde las cinco de la tarde, las vías de acceso se cierran a los vehículos, convirtiéndose en exclusivas para los peregrinos resaltando así la magnitud y el fervor de esta celebración católica. El 7 de diciembre comienza el día con el emocionante rezo de la novena alrededor 7:00 de la mañana. Por la tarde, a las 19:00 horas es la primera misa en presencia de la Virgen en el altar de la plaza. Esta misa es muy importante para los devotos de la Vigen, un momento especial dentro del santuario. A lo largo de la noche y la madrugada, se celebran las 10 eucaristías, marcando cada dos horas un momento especial de comunión y fe. Estas comienzan a las 10 de la noche del mismo día y terminan a las 7 la noche del día siguiente, del 8 de diciembre.

MEDIA MARATÓN

DE COTOCA

Ubicación: Desde Km 0 de Santa Cruz de la Sierra hasta plaza 8 de diciembre, Cotoca.

ph: Atlestar

El evento programado más antiguo y tradicional de nuestro departamento es la 'Media Maratón de Cotoca'. Organizado desde 1980 por la Asociación de Profesores de Educación Física, este acontecimiento consiste en una maratón pedestre que se lleva a cabo cada 7 de diciembre y reúne a muchos en un evento deportivo emblemático. Año tras año, cientos de personas convergen en este tradicional encuentro, unidos por un propósito común: pedirle bendiciones de bienestar y salud a la Mamita de Cotoca. Esta celebración no es solo una simple carrera de 21 kilómetros; también es un acto de devoción y conexión espiritual. Los participantes, motivados por la fe, recorren cada paso con determinación, conscientes del profundo significado de esta maratón. El evento marca el inicio de la romería al Santuario de Cotoca, un momento de gran importancia cultural y religiosa para los habitantes de la región. Sin embargo, este medio maratón no es exclusivo para creyentes, ya que también participan apasionados por correr (los autodenominados runners). Se estima que, a la fecha esta actividad ha convocado a más de 30 mil corredores a lo largo de los años.

ph: Atlestar

CIUDAD EL TRIUNFO

Ubicación: RN4, entre Cotoca y Pailón

ph: Ciudad El Triunfo

Entre los municipios de Cotoca y Pailón, se encuentra ubicado un proyecto cultural y turístico: Ciudad del Triunfo. Este innvoador proyecto marca un hito como la primera ciudad SmartLife (vida inteligente) en Santa Cruz y todo el país. Con una extensión de 300 hectáreas, esta ciudad del futuro está destinada a redefinir la forma en que vivimos y nos relacionamos con nuestro entorno. Su importancia es tal, que fue declarado Patrimonio Cultural y Ecoturístico de Cotoca mediante Ley Autonómica municipal No 039/2022. En Ciudad El Triunfo, se está construyendo el hogar ideal para más de 6.000 familias, distribuidas en 12 urbanizaciones cuidadosamente planificadas. Lo que distingue a Ciudad El Triunfo es su enfoque holístico hacia el bienestar de sus residentes y el cuidado del medio ambiente. Aquí, el arte, la cultura y la protección del entorno natural se entrelazan en el tejido mismo de la comunidad. Lugares como La Casa del Huerto y El Vivero Sembrarte no solo son espacios verdes, sino que también son motores de cambio, contribuyendo a la restauración del ecosistema local y promoviendo una vida más saludable y equilibrada. Una de las innovaciones más destacadas de Ciudad El Triunfo es La Cosecha del Agua, un proyecto revolucionario que recoge y aprovecha el agua de lluvia para su reutilización, promoviendo así la conservación de este recurso vital y fomentando prácticas sostenibles entre sus habitantes. Como no podía faltar, también encontrarás a tu disposición restaurantes, cafés y diversas ofertas gastronómicas que van desde los platillos típicos de la región, hasta presentaciones culinarias variadas.

ph: Ciudad El Triunfo

MERCADO CENTRAL

8 DE DICIEMBRE

Ubicación: Calle Redentor Roca, entre calle Cipiriano Gutierrez y calle Sucre.
Atención: Lunes a Domingos - 07:00 a 20:00

ph: GAD SCZ

El tradicional Mercado 8 de diciembre es una parada obligatoria para quien visita Cotoca y quiere degustar la sazón tradicional de el municipio. Al visitarlo encontrarás una variedad de platos destacados, como los irresistibles pacumutos y el majadito de pato, que prometen una experiencia gustativa única. Este pintoresco mercado no solo ofrece sabores auténticos, sino que también brinda una inmersión en la vida cotidiana y el encanto de este hermoso municipio. El bullicio de las conversaciones entre vendedoras, los intercambios de risas y charlas animadas llenan el ambiente, permitiendo que experimentés el diario vivir del pueblo cotoqueño.

ph: GAD SCZ

ph: GAD SCZ

Este mercado es parte del casco viejo de Cotoca y es, además, un referente para los oriundos de la región. Además, el mercado 8 de diciembre se prepara para recibir a todos los visitantes en cada uno de los festivales y acontecimientos que tiene el municipio, como sucede por ejemplo cada 7 de diciembre. Son un centenar de personas las que este mercado recibe a diario, estableciéndose como un punto céntrico para el comercio del pueblo y para sus habitantes. Es fácil entender a qué se debe la gran afluencia de gente, ya que al visitarlo, experimentarás la calidez y el servicio recargado de amabilidad. Ya sea que busques sumergirte en la vida cotidiana de Cotoca, adquirir recuerdos únicos o deleitarte con la gastronomía típica, este mercado es un destino imperdible.

ALFARERÍA DE COTOCA

Ubicación: Actividad realizada dentro del municipio de Cotoca

La alfarería en Cotoca es una actividad fundamental, formando parte de la identidad del pueblo cotoqueño hace años. Se cree que la población surgió en 1607, como una población nativa de origen chané-chiquitana, ya contaba con una cultura agrícola y alfarera reconocida por los españoles y criollos, quienes llamaron al lugar "pueblo alfarero". Antiguamente los residentes se dedicaban principalmente a elaborar los tradicionales cántaros, tinajas, cazuelas, macetas, chipenos, jarrones y otras piezas de utilidad para el hogar con barro cocido.

Si bien estas técnicas para la elaboración continúan siendo utilizadas, actualmente podrás encontrar piezas grandes y especiales, principalmente para usos decorativos cuyos diseños tienen una diversidad de fuentes u orígenes, adaptadas al gusto de los visitantes. Si te interesa la alfarería, Cotoca cuenta con un museo local que muestra piezas tradicionales, creado en 2017 por el Colegio "Beneméritos de la Patria".

FERIA DE LAS ARTESANIAS

Ubicación: Calle Flora de Natusch entre c/Rodolfo Añez y Av. Santa Cruz

Este festival expone la gran variedad de materiales, con los que se hacen estas artesanías, desde cerámica, madera y cuero hasta bijutería. En cada detalle, en cada textura y en cada color, las artesanías de Cotoca nos invitan a sumergirnos en un mundo de belleza auténtica y genuina. Las ferias se realizan a inicios de septiembre de todos los años en la víspera de la primavera. Desde los años ochenta, la alfarería en Cotoca ha sido muy importante. En dicha década, esta labor comenzó a tomar un rol protagónico en la población femenina, siendo una actividad productiva para el sustento familiar. A la fecha, las mujeres han enseñado este oficio de generación en generación, donde los visitantes son testigos silenciosos del talento y la dedicación de quienes las crean. Más allá de la producción de objetos, el sector artesanal en Cotoca representa una conexión profunda con la identidad cultural y el patrimonio de la región. En este sentido, su potencial trasciende lo económico, convirtiéndose en un motor de desarrollo y en un testimonio vivo del espíritu emprendedor y la creatividad del pueblo de Santa Cruz.

FESTIVAL DE LA JALEA COTOQUEÑA

Ubicación: Calle Flora de Natusch entre c/Rodolfo Añez y Av. Santa Cruz

Un evento único que celebra las delicias derivadas de la miel de caña: el Festival de la Jalea en Cotoca. Este festival es un espacio que promueve la comercialización y el disfrute de productos tradicionales, con una amplia gama de platos y bebidas típicas, además de la jalea de miel de caña, el producto principal. Cada 9 de julio los cotoqueños lanzan una cálida invitación para que tanto locales como visitantes se unan a la celebración este fin de semana. Una fiesta alegre acompañada de la melódica tamborita, danzas orientales y visitantes entusiastas que, además de degustar la jalea, también disfrutan del espectáculo. Actualmente, el festival se lleva a cabo en el frontis del mercado nuevo de Cotoca. No perdás la oportunidad de conocer la cultura y los sabores de la región en el Festival de la Jalea de Cotoca, una experiencia tradicional y culinariamente exquisita.

FESTIVAL DE LA AREPA Y SONSO

Ubicación: Calle Flora de Natusch entre c/Rodolfo Añez y Av. Santa Cruz

Desde hace una década, Cotoca celebra el Festival de la Arepa y el Sonso, un evento que busca resaltar una de las ofertas gastronómicas más representativas del municipio. Organizado por la Asociación productora "8 de diciembre", el festival atrae a múltiples visitantes para degustar los famosos sonsos y arepas, además de una variedad de platos regionales.

Para atender la demanda, los comerciantes del mercado emplean una gran cantidad de ingredientes: 10 arrobas de yuca y 40 kilos de queso que son utilizados para preparar los deliciosos sonsos y arepas. Cotoca te espera para que, junto a tu familia y amigos, experimentés la tradición y alegría en el Festival de la Arepa y el Sonso que este municipio, tiene para vos.

FESTIVAL DE LA TABLILLA Y EL EMAPANIZADO

Ubicación: Calle Flora de Natusch entre c/Rodolfo Añez y Av. Santa Cruz

En abril, el municipio de Cotoca celebra el Festival de la Tablilla y el Empanizado, atrayendo visitantes de toda la región. El evento, que comienza a las 10:00 hrs, ofrece una amplia variedad de tablillas típicas del municipio, amenizado por la tradicional tamborita, con juegos populares, danzas típicas y una hora de tablillas gratis. Organizado por la Asociación de Tablilleras "11 de septiembre" con casi 50 socias, este festival celebra la rica tradición culinaria de Cotoca, impulsando la actividad productiva y turística de la región.

FESTIVAL ANTICUCHO

Ubicación: Calle Flora de Natusch entre c/Rodolfo Añez y Av. Santa Cruz

La Feria del Anticucho, que se celebra entre octubre y noviembre, se distingue por el aroma de la carne asada que llena el aire mientras las personas disfrutan de diversos anticuchos. Se lleva a cabo en la plaza principal de Cotoca, atrayendo turistas del departamento que buscan una experiencia deliciosa. Además de la variedad de anticuchos, se elige a la reina entre las mujeres de la asociación, quienes organizan el evento. Para los habitantes de Cotoca y los visitantes, el Festival del Anticucho es una oportunidad para celebrar la identidad, fortalecer los lazos vecinales y compartir la riqueza cultural de la región.

LOS POTROSOS

Ubicación: Km 45, camino a comunidad Don Lorenzo

Los Potrosos es un plato tradicional de la comunidad Don Lorenzo, en Cotoca. Consiste en pacumutos de carne molida envueltos en hojas de plátano, cocidos a la parrilla y servidos con arroz o yuca. Este plato es el principal atractivo del Día de la Tradición, donde se puede degustar y participar en actividades tradicionales como carreras a caballo o motocicletas. Además, hay presentaciones de danzas típicas y la coronación de la reina de la tradición de Don Lorenzo.

PARQUE FANTASÍA

Ubicación: Cotoca. carretera Itapaqui
Atención: Lunes a Domingos - 07:00 a 20:00

ph: Parque Fantasía

El parque Fantasía se encuentra ubicado a 27 kilómetros de la capital cruceña, en el municipio de Cotoca. Este hermoso lugar es una alternativa ideal si buscás días de diversión y relajación en familia, pareja o con amigos. Este espacio tiene múltiples temáticas. Cuenta con una especie de ciudad miniatura en la que se encuentran diversas esculturas miniatura de lugares emblemáticos del mundo y la región, como La Catedral Metropolitana, el Cristo Redentor, casonas antiguas y hasta El Kremlin de Moscú, Rusia, entre muchos más. Cuenta con una variedad de parques para que niños de todas las edades puedan divertirse y realizar múltiples juegos. Tiene piscinas abiertas al público y áreas verdes que se usan como descanso, todo esto por un costo de tan solo 20 bolivianos. El parque cuenta con espacios para que realices churrascos al son de la música y podás disfrutar junto a tus seres queridos.

ph: Parque Fantasía

ph: Complejo turístico ITAÚ

Complejo turístico recreativo Itaú, es un establecimiento de hospedaje que busca brindar una experiencia de tranquilidad y descanso para quienes lo visitan. Se encuentra ubicado a 15 minutos de la plaza 8 de diciembre de Cotoca, con un camino de ingreso semi accesible. Ofrece a sus huéspedes una variedad de habitaciones en estructuras tipo de cabaña, además de contar con áreas de descanso recreativas, deportivas y de relajación. Con ingreso los 365 días del año y, además de una constante renovación de sus paquetes promocionales al público. Un dato interesante es que podés acceder a una membresía y tener la posibilidad de acceder con miembros de tu familia.

ph: Madre Selva

Ubicado a tan solo 10 minutos de la plaza principal de Cotoca, se encuentra el complejo turístico Madre Selva. Este encantador complejo es uno de los principales atractivos del municipio, ofreciendo un entorno perfectamente armonizado con la naturaleza, ideal para relajarte y desconectarte de la rutina los fines de semana o vacaciones. Cuenta con acceso a piscinas, amplios espacios de esparcimiento y opciones de alimentación para tu comodidad. Ofrece a sus visitantes una variedad de habitaciones de diferentes tamaños. Los precios están categorizados entre adultos y niños. El ingreso de una persona adulta tiene un costo de Bs 70, mientras que el de un niño es de Bs 40 (considerado desde los 3 a 10 años de edad. El acceso al sauna tiene un costo extra de Bs 20).

PUERTO PAILAS

Ubicación: Km 44, la puerta a Río Guapay

ph: Natalia Rivera

Esta encantadora localidad se encuentra situada en el municipio de Cotoca. Fundada el 23 de julio de 1843. La principal actividad económica de la localidad de Puerto Pailas es la pesca, siendo así esta localidad la principal productora de la región. Son más de 3.000 familias las que se benefician de esta actividad. Por ello, cada año, al terminar el mes de mayo, se lleva a cabo la mayor feria dedicada a este alimento, una celebración que refleja la pasión y el arraigo de la comunidad por esta actividad tan importante en su vida diaria. De igual se encuentra la estación de ferrocarriles que, si bien en la actualidad se encuentra abandonada, alberga una historia en sus rieles, demostrando los inicios del progreso y prosperidad de nuestro departamento. Es una localidad que aún conserva la identidad integral del pueblo cotoqueño, donde conocerás de cerca la humildad y hospitalidad de esta tierra. Viví la experiencia en Puerto Pailas.

PARQUE INDUSTRIAL

DE COTOCA

Ubicación: RN4, entre Cotoca y Pailón, pasando Km 5 desde Cotoca
Atención: Lunes a Viernes - 8:30 a 17:30

Conocido comercialmente como 'Parque Industrial Maccaferri LTDA', se ubica a solo 22 km de la capital del departamento de Santa Cruz, que se presenta como un polo de desarrollo económico y una muestra de la diversificación industrial de la región. El proyecto, de origen privado, contempló inicialmente una visión de 32 ha, que hasta ahora ha captado la atención de inversores de diversas partes de Bolivia, incluyendo Tarija, Cochabamba y La Paz. Este parque industrial en desarrollo, con 12 ha en uso, alberga una variedad de fábricas especializadas en la producción de bienes esenciales, como productos de limpieza, plásticos, tubos y materiales forestales destinados a la construcción. La diversidad industrial aquí es un testimonio de la capacidad del departamento de Santa Cruz para atraer y acomodar diferentes sectores del mercado. Las parcelas dentro del complejo se han vendido por precios que oscilan entre $280,000 y $600,000, dependiendo de la ubicación y el tamaño del lote. El Parque Industrial de Cotoca no solo refleja el crecimiento económico de Santa Cruz, sino que también ofrece amplias oportunidades de inversión.

GRAN ALIMENTO

EMPRESA DE INVESTIGACIÓN GENÉTICA

Ubicación: Km 17, Carretera a Cotoca.
Atención: lunes a sábado, 8:00 a.m. a 12:00 p.m. y de 2:30 a 6:30 p.m.

Ubicada en la próspera zona industrial de Cotoca, la empresa Gran Alimento se inauguró el 15 de septiembre de 2012 como una avanzada procesadora de soya. Esta planta ofrece un valor agregado a la producción agrícola del país. Con una capacidad de almacenaje de más de 30 millones de kilogramos de granos y un inventario promedio de US$15 millones, Gran Alimento se erige como un pilar industrial, brindando soluciones innovadoras y sostenibles para la seguridad alimentaria a nivel mundial. Descubre esta impresionante obra de desarrollo industrial y cuidado alimenticio.

FRIDOSA

Ubicación: RN 4, Cotoca, Santa Cruz – Bolivia.
Atención: Lunes a Sábado, 8:00 a.m. a 06:00 p.m.

Es una empresa emblemática en el departamento de Santa Cruz, ubicada en el municipio de Cotoca. Representa un pilar fundamental en el desarrollo industrial de la región. Con una trayectoria de excelencia y compromiso, esta empresa se ha consolidado como líder en la producción y distribución de alimentos en el sector de carne de res. Su moderna planta de producción, equipada con tecnología de última generación, garantiza la calidad y frescura de sus productos, que se han convertido en parte esencial de la dieta diaria de miles de hogares en toda Bolivia. Además de su contribución al sector alimentario, FRIDOSA se destaca por su compromiso con la sostenibilidad y el desarrollo comunitario, siendo un ejemplo de responsabilidad empresarial en la región.

PORONGO

ph: GAM Porongo
ph: GAD SCZ

PORONGO

Provincia: Andrés Ibañez
Fundación: 22 de febrero de 1714

DATOS GENERALES

Porongo representa un lugar típico de antaño, por mantener casi intactas sus costumbres. El vocablo "Porongo" se deriva de la palabra guaraní "poro", que era el nombre dado por los guaraníes al fruto de una planta trepadora que abundaba en la región. Este fruto de gran tamaño era secado y utilizado en las viviendas para conservar agua fresca o alimentos.

DATOS DEMOGRÁFICOS

Gentilicio: Porongueño (a)
Población[1]: (2023): 23.844 habitantes
Densidad: (2023): 25 hab./km²

CLIMA

Tropical húmedo – seco, con veranos muy cálidos y húmedos e inviernos secos y tibios-templados. Se observa la presencia de vientos predominantes del norte, sin embargo; con cierta frecuencia se presentan vientos del Sur por períodos cortos en épocas secas (surazos) con velocidades que alcanzan hasta los 80 km/hora.

DATOS GEOGRÁFICOS

Ubicación: 18,8 kilómetros hacia el oeste de la ciudad de Santa Cruz de la Sierra.

Coordenadas: 17°33´ y 17°57´ de Latitud Sur y los meridianos 63°12´ y 63°30´ de Longitud Oeste

Superficie: 938 km2

Altitud: 425 m s.n.m.

ECONOMÍA

Economía[2]: Las actividades económicas más importantes son la pecuaria y agrícola, que de acuerdo al Valor Bruto de Producción (VBP) del municipio representan el 48.83% y 21.37% respectivamente.

Sobresale la fruticultura, principalmente con la producción de mandarina y naranja. Abastece a la ciudad de Santa Cruz de la Sierra con el 50% de los cítricos que consume.[3]

Valor Bruto de Producción (VBP): 67 MM Bs.

---

[1] Encuesta de Estimación Poblacional de Santa Cruz 2023. Instituto Cruceño de Estadística
[2] Mapa de Complejidades, BDP 2019
[3] PTDI del Municipio de Porongo 2015 – 2019

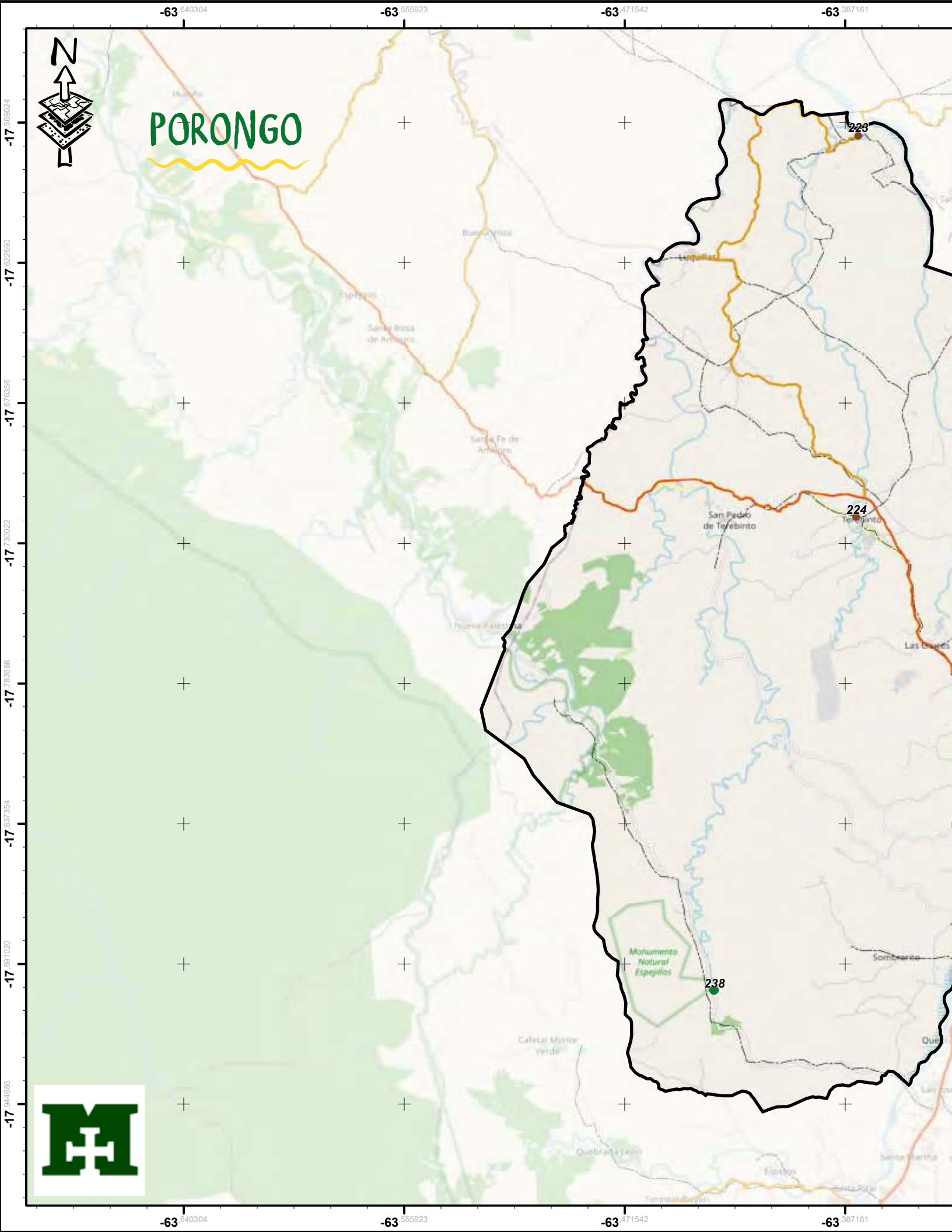
PORONGO
N
-63.640304
-63.555923
-63.471542
-63.387161
-17.569024
-17.622690
-17.676356
-17.730022
-17.783688
-17.837354
-17.891020
-17.944686
223
224
238
San Pedro de Terebinto
Monumento Natural Espejillos

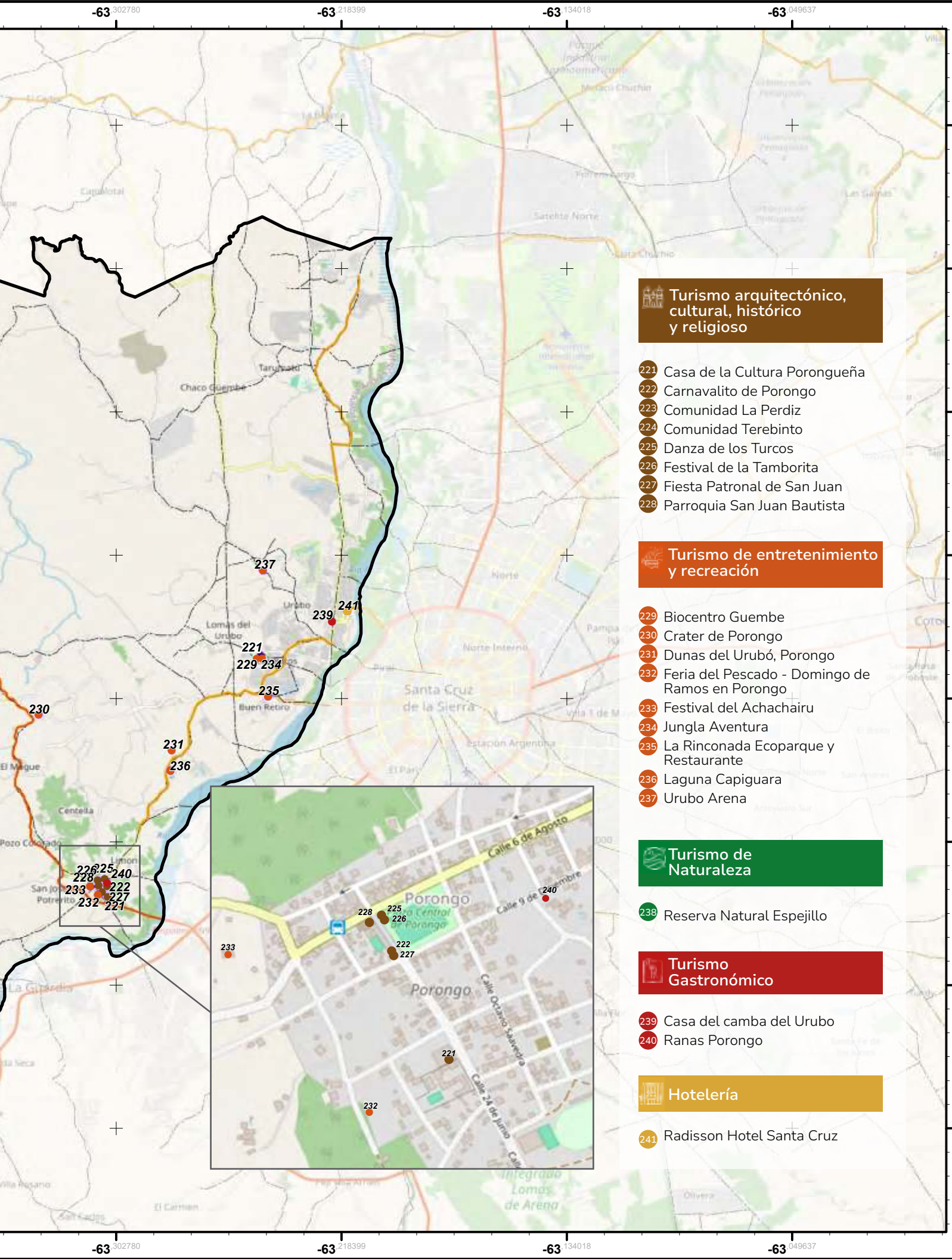

Turismo arquitectónico, cultural, histórico y religioso

- 221 Casa de la Cultura Porongueña
- 222 Carnavalito de Porongo
- 223 Comunidad La Perdiz
- 224 Comunidad Terebinto
- 225 Danza de los Turcos
- 226 Festival de la Tamborita
- 227 Fiesta Patronal de San Juan
- 228 Parroquia San Juan Bautista

Turismo de entretenimiento y recreación

- 229 Biocentro Guembe
- 230 Crater de Porongo
- 231 Dunas del Urubó, Porongo
- 232 Feria del Pescado - Domingo de Ramos en Porongo
- 233 Festival del Achachairu
- 234 Jungla Aventura
- 235 La Rinconada Ecoparque y Restaurante
- 236 Laguna Capiguara
- 237 Urubo Arena

Turismo de Naturaleza

- 238 Reserva Natural Espejillo

Turismo Gastronómico

- 239 Casa del camba del Urubo
- 240 Ranas Porongo

Hotelería

- 241 Radisson Hotel Santa Cruz

RESERVA NATURAL

ESPEJILLOS

Ubicación: Municipio de Porongo, a 45 kilómetros de la ciudad de Santa Cruz de la Sierra

ph: GAD SCZ

La Reserva Natural de Espejillos, se encuentra ubicada en la zona sur del Parque Nacional Amboró, fue creada en el año 2000 y declarada Patrimonio Natural y Turístico del país, según Ley N° 413 del 30 de septiembre de 2013. Existen dos vías habilitadas para ingresar a este paraíso natural, la primera parte desde el municipio de Porongo sobre caminos de tierra transportándote hacía una aventura extrema que pondrá a prueba tu habilidad al volante, ideal para aquellos que disfrutan realizar deportes extremos como el denominado road trip, como segunda opción tenés el ingreso por el municipio de la Guardia, donde el recorrido comienza en la comunidad San José y termina con la llegada al complejo turístico

ph: Espejillos Monumento Natural

que se encuentra en la Comunidad Agua Dulce. Una vez dentro de la reserva, podrás disfrutar de pozas naturales y cristalinas cascadas, con un paisaje espectacular que incluye árboles de hasta 30 metros y abundantes orquídeas, además que Espejillos, es hogar de una rica diversidad de fauna, con 593 especies entre anfibios, aves, reptiles, mamíferos, mariposas y plantas vasculares. Tenés la opción de visitar y alojarte en el complejo turístico, que cuenta con áreas recreativas, hospedaje (camping incluido al ingreso), cabañas para que podás compartir, además de incluir la venta de alimentos y bebidas a un precio accesible. El costo de ingreso es Bs 20 para adultos y Bs 10 para menores a 13 años, abierto desde las 08:00 a 17:00 Hrs, de lunes a viernes incluyendo feriados. Tacuarembó, Agua Dulce y Surutú son las comunidades que, bajo un acuerdo ecoturístico comunal, administran los atractivos turísticos como el mariposario ubicado dentro de la comunidad Surutú y el complejo turístico, convirtiéndose algunos de ellos en guías locales que tranformarán tu visita en una experiencia cargada de conocimiento del destino.

ph: Espejillos Monumento Natural



ph: Espejillos Monumento Natural

ECOPARQUE Y RESTAURANTE

LA RINCONADA

Ubicación: Camino a Porongo, antes del desvío a Buen Retiro, zona del Urubó
Atención: Martes a Domingo - 09:30 a 18:00

ph: La Rinconada

La Rinconada Ecoparque & Restaurante es un cobijo natural para los visitantes del municipio de Porongo. Este resort, ubicado a 7 kilómetros de la capital cruceña, te ofrece la combinación perfecta entre comodidad, tranquilidad y disfrute. En sus instalaciones, te encontrarás con atractivos senderos, bellas lagunas, pequeñas cascadas y cientos de plantas exóticas que te invitarán a conectar con la naturaleza y redescubrir una parte esencial de Santa Cruz. Una de las plantas exóticas que no te podés perder es la hoja de nenúfar más grande del mundo. Fue encontrada en el departamento del Beni hace 22 años y trasladada a La Rinconada, lugar donde se le construyó un hábitat únicamente para que pueda crecer sin partirse, logrando preservar la magnitud de sus cautivadores colores y tamaños. Conocida y bautizada como la Victoria Boliviana, alcanzó en 2012 dos reconocimientos Guinness: el primero a la hoja más grande del mundo y el segundo a la hoja sin dividir más grande del mundo. Fue así como, con 3,2 metros de diámetro, uno de los ejemplares terminó convirtiéndose en un símbolo destacado de la variedad de flora que posee nuestro departamento. Pero eso no es todo, además de poder disfrutar una conexión con la naturaleza (que sin lugar a duda es toda una aventura), podrás acceder a múltiples servicios gastronómicos que La Rinconada ofrece. Estos servicios buscan brindarte la experiencia auténtica de degustar la comida cruceña. Entre sus deliciosos platillos encontrás el majao batido, la cola de lagarto y carne a la parrilla, acompañados de los tradicionales refrescos de fruta de temporada y el característico mocochinchi, que es conocido por ser uno de los mejores que existen en la región.

ph: La Rinconada

ph: La Rinconada

BIOCENTRO GÜEMBÉ

Ubicación: Km. 5 camino a Porongo, Zona Urubó
Atención: Lunes a Domingo - 9:30 am a 17:30 pm

ph: Trip Advisor

El Biocentro Güembé es un refugio natural y un atractivo turístico de primer nivel, reconocido por su diversidad ecológica y la impresionante belleza de sus instalaciones. Ubicado a 13 kilómetros de la capital cruceña, es un entorno de 24 hectáreas que abarca múltiples espacios ecológicos, como el Aviario, Mariposario, Pantano, Tortugario, el Curichi, Orquidiario, Jungla de Monos y el Terrario, convirtiéndose en un paraíso natural rodeado de plantas exóticas, bosques exuberantes y una rica variedad de fauna autóctona. Con áreas naturales bien preservadas, senderos ecológicos que invitan a explorar, lagunas serenas y un total de 15 piscinas naturales, es el destino ideal para que vayas con tus amigos, familia y pareja, o cualquier amante de la naturaleza que busque una experiencia única e inolvidable.

ph: Trip Advisor

ph: Trip Advisor

JUNGLA AVENTURA

Ubicación: Km. 5 camino a Porongo, Zona Urubó
Atención: Lunes a Domingos - 9:30 a 18:30

ph: Biocentro Güembé

Jungla Aventura es un emocionante parque temático que brinda una experiencia única para quienes disfrutan de la adrenalina y la naturaleza, ya que ofrece actividades de aventura en medio de la belleza de la selva tropical. Entre las emocionantes actividades que podrás realizar se encuentran el salto en tirolesa, el camino por puentes colgantes y la oportunidad de disfrutar y explorar la exuberante naturaleza que rodea el parque.

LAGUNA CAPIGUARA

Ubicación: Km 13 Carretera a Porongo
Atención: Lunes a Viernes - 8:30 a 18:30 y Sábados y Domingos - 8:30 a 19:30

ph: Laguna Capiguara

Un tesoro natural con un potencial turístico y estratégico innegable: Laguna Capiguara. Este sitio abarca alrededor de 600 hectáreas y te ofrece la posibilidad de disfrutar de un día relajante en cualquier época del año. La Laguna Capiguara promete estar disponible los 365 días del año para brindar atención continua. El espacio se divide en dos áreas principales. En la primera, los visitantes pueden disfrutar de parrillas ya instaladas, sillas para tomar el sol, un enorme tobogán recientemente construido, juegos infantiles y barquitos a pedal, disponibles por un costo adicional. Además, en el sector de las cabañas ubicadas a lo largo de la orilla, se ofrece una variada oferta gastronómica. La segunda área de la Laguna Capiguara cuenta con tres piscinas: una piscina infantil de 2,000 metros cuadrados; una piscina más pequeña diseñada para amortiguar el impacto de la caída desde los toboganes; y, por último, una piscina para adultos, la más grande, con una extensión de 7,000 metros cuadrados.

CRATER

DE PORONGO

Ubicación: Km 18, zona del Urubó, Porongo

ph: Municipio de Porongo

Para los entusiastas de la aventura y el ciclismo, el cráter de Porongo es un destino imperdible. Ubicado a solo 18 km del puente del Urubó, esta experiencia te hará vivir emociones únicas y disfrutar de paisajes cautivadores que no querrás dejar pasar. Desafía tus límites y descubrí la magia de este lugar que te dejará sin aliento. Además, vale la pena mencionar que el camino es mayormente asfaltado, con excepción del último tramo, que añade un toque extra de emoción a la aventura.

DUNAS DE ARENA

EN PORONGO

Ubicación: Km 13, Carretera a Porongo

ph: GAD SCZ

Descubrí las impresionantes Dunas de arena del Urubó, estructuras naturales esculpidas por el viento a lo largo de los años. Este destino cuenta con un clima agradable, característico de la región, que lo convierte en el lugar perfecto para una variedad de actividades al aire libre. Desde apacibles caminatas hasta la captura de impresionantes fotografías que reflejan la belleza incomparable del paisaje, estas dunas ofrecen un entorno ideal para disfrutar y explorar.

ECO RESORT
LA RIVIERA

Ubicación: Camino a Tarumatú a 3 Km. A la Belgica, a 15 Km. de Santa Cruz
Atención: Siempre abierto

ph: Eco Resort La Riviera

Descubrí el acogedor Eco Resort La Riviera del Urubó, situado a 15 kilómetros de la capital cruceña, dentro del municipio de Porongo. Con cómodas habitaciones tipo cabaña y una amplia gama de servicios, este Eco Resort te ofrece el escape perfecto para relajarte y disfrutar de la tranquilidad, lejos del bullicio de la zona urbana. Podrás disfrutar de la refrescante piscina al aire libre, relajarte en el sauna o explorar la laguna en un paseo en kayak. Además, tendrás la opción de elegir entre una variedad de comidas en el restaurante y refrescantes cócteles en el bar. Para los más pequeños, hay un parque infantil y una sala de juegos, mientras que los adultos tienen a su disposición el servicio de entretenimiento nocturno con karaoke. El Eco Resort La Riviera te espera, con acceso exclusivo al río Piraí y muchas sorpresas más.

HOTEL
RADISSON

Ubicación: Av. Segunda # 4, Colina del Urubó. Municipio de Porongo
Atención: Siempre abierto

ph: Santa Cruz Top Hotels

Hotel 5 estrellas ubicado a 30 minutos del Aeropuerto Internacional Viru Viru. Es una excelente opción para aquellos viajeros que buscan comodidad y lujo durante su estancia en Santa Cruz. Ubicado en Colina del Urubó y de fácil acceso cruzando el puente Mario Foianini, que une los municipios de Santa Cruz de la Sierra y Porongo.

AEDEP

ASOCIACIÓN DE EMPRESARIOS DESARROLLADORES DE PORONGO

Ubicación: Av. Noel Kempff N° 702 (3er Anillo Interno frente Clínica Martín Dockweiler)
Atención: Lunes a viernes de 09:00 a 12:30 Hrs.

La Asociación de Empresarios Desarrolladores de Porongo (AEDEP), con oficina situada en la capital cruceña, emerge como un faro de progreso y colaboración en la región de Porongo. Con un enfoque claro en el desarrollo económico y social, esta asociación reúne a empresarios comprometidos con el crecimiento sostenible y la mejora de la calidad de vida en Porongo y sus alrededores. La AEDEP es un ejemplo inspirador de cómo la colaboración y el compromiso pueden impulsar el progreso y el bienestar en una comunidad. Con su visión audaz y su dedicación inquebrantable, esta asociación continúa siendo un motor de cambio positivo en Porongo y Santa Cruz, además de ser un modelo a seguir para otras comunidades.

FERIA DE LA MIEL

Ubicación: Av. 24 de Junio, en la plaza principal de Porongo.

La Feria de la Miel Ecológica de Porongo, conocida comúnmente como "La Feria de la Miel", organizada por la Asociación de Apicultores Ecológicos Colinas del Amboró (ASAPECAB) en coordinación con el municipio de Porongo, es un evento imperdible para los entusiastas de la apicultura. La feria ofrece productos como miel pura certificada, propóleos y caramelos de miel, todos provenientes de colmenas que albergan entre 50,000 y 60,000 abejas. Según los productores, esta actividad impulsa la economía local, con una producción anual de 18,000 kilos de miel de 700 colmenas. Además, se realizan capacitaciones, como por ejemplo talleres en relación a la apicultura ecológica, dirigidos a pequeños y medianos productores locales, siendo sin duda un espacio para el desarrollo productivo local.

URUBÓ

ARENA

Ubicación: Km 11, 4 Zona del Urubó
Atención: Sábados y Domingos - 17:00 a 23:30 Hrs.

Urubó Arena es el primer centro de entretenimiento al aire libre ubicado en el Urubó, diseñado para realizar shows y eventos de primer nivel. Además, cuenta con la capacidad de albergar a más de 15.000 personas.

IGLESIA

SAN JUAN BAUTISTA

Ubicación: Av. 24 de Junio, frente a la Plaza Principal de Porongo
Atención: Domingo 7:30 y 9:00; Lunes y Jueves - 19:30

ph: GAD SCZ

ph: Arquidiosis de SC de la Sierra

ph: Arquidiosis de SC de la Sierra

ph: GAD SCZ

Fundada en 1714, la Iglesia San Juan Bautista de Porongo es una de las últimas iglesias misionales construidas y se encuentra ubicada a 18 kilómetros de la capital cruceña. Declarada como Patrimonio Cultural e Histórico del departamento mediante Ley N°45 del 13 de junio de 2012, es el atractivo religioso más representativo del municipio y un referente histórico. La historia de esta Iglesia se remonta al siglo XVII, cuando se estableció un núcleo misional en la región de Porongo bajo el liderazgo del fray Santiago del Rivero, quien fue el doctrinero y fundador de esta encantadora misión. La población original constaba de 50 indígenas de origen chiriguano, a quienes se les enseñaba a tocar instrumentos musicales como violines, bajones y otros; la fachada de la iglesia presentaba un estilo barroco mestizo, con tallados en madera en el altar, impresionantes columnas, hermosas pinturas y altares dorados. Casi 200 años después, por decisión de los feligreses la iglesia fue completamente refaccionada, sin embargo, se ha mantenido fiel al estilo original que la caracteriza, conservando el legado histórico y adquiriendo piezas emblemáticas como su campana, que antes se encontraba en la catedral de Santa Cruz de la Sierra. También es el escenario de diversas actividades religiosas a lo largo del año, incluyendo el Festival Internacional de Música Renacentista y Barroca Americana "Misiones de Chiquitos" con la visita de orquestas nacionales e internacionales, misas, procesiones y festividades en honor a San Juan Bautista.

FIESTA PATRONAL

DE SAN JUAN

Ubicación: Av. 24 de Junio, frente a la Plaza Principal de Porongo

En Porongo, el mes de junio adquiere un sentido especial, se lleva a cabo la celebración más importante del municipio, la Fiesta Patronal de San Juan Bautista. Esta fiesta además de honrar al Santo Patrono, reúne a visitantes de todo el departamento en una conmemorativa manifestación de fe, cultura y tradiciones. Se estima que para la noche del 23 de junio, Porongo recibe alrededor de 15 mil visitantes de todas partes de Santa Cruz y del país. Las celebraciones comienzan a mediados de junio, cuando los devotos emprenden una procesión con la imagen de San Juancito hacia la comunidad Esmeralda, donde se lleva a cabo la tradicional "sacada del palo ensebao". Este debe ser cortado por la familia que lo encontró, para luego ser pulido y bendecido por el párroco de Porongo. Una vez llegado el 23 de junio, se lleva a cabo una procesión por la mañana para trasladar a San Juancito al río Piraí, donde se bendice el agua que se recoge en tinajas, la cual se utilizará para el bautizo de seis

ph: De Redes Tv.

ph: Mente Poderosa

niños esa misma noche. La fiesta da inicio con la llegada de las antorchas desde la capital cruceña, portadas por múltiples atletas que, impulsados por la fe, llegan al municipio de Porongo con la llama del jenecherú (el fuego que nunca se apaga), para encender la fogata central. Las fogatas son otra parte imprescindible de la celebración. En tiempos antiguos, las fogatas se encendían en las casas de los locales, pero la costumbre ha ido mutando con los años y actualmente se realiza una sola fogata para todo el municipio, ubicada frente a la parroquia. Una vez que la llama baja su intensidad, tiene lugar la tradicional pisada por las brasas, donde los valientes cruzan descalzos sobre las cenizas aún ardientes, simbolizando el cumplimiento de sus promesas al Santo Patrono. Cada año, los asistentes pueden disfrutar de estos festejos que van acompañados de múltiples bailes y música tradicional, siempre de la mano de un delicioso sucumbé caliente y de la alegría característica del pueblo.

CASA DE LA CULTURA

PORONGUEÑA

Ubicación: Av. 24 de Junio, frente a la Plaza Principal de Porongo
Atención: Lunes a Viernes - 08:00 a 12:00 y de 13:00 a 17:00 Hrs.

La Casa de la Cultura Vidal Sosa, conocida como Casa de la cultura Porongueña, es un homenaje al legado del costumbrista Vidal Sosa Soliz. Nacido en 1956, Sosa fue reconocido como un ícono cultural en su municipio. Su dedicación a proyectos de desarrollo local y su pasión por la música y la poesía lo mantuvieron ligado a la actividad cultural durante 29 años, bajo el apodo de "El Carretero Enamorao". En el interior de esta casa de la cultura, podrás experimentar la vida y obra de este artista a través de un museo dedicado en su honor. La sala de exposición alberga una rica colección de fotografías, trofeos y objetos personales que cuentan la historia de Sosa, incluyendo su primera guitarra y una selección de su obra poética. Este espacio se convierte así en un punto de encuentro para admiradores y estudiosos del legado cultural de Porongo y de la figura inmortalizada de su legado. La Casa de la Cultura Vidal Sosa, situada a tres cuadras de la plaza principal, se erige como un faro de

la identidad cultural de Porongo. Sus puertas abiertas de lunes a viernes permiten que tanto locales como visitantes se introduzcan en la riqueza del patrimonio cultural local y rindan tributo a la memoria de un hombre que dedicó su vida a enriquecer el alma de su pueblo a través del arte y la poesía.

COMUNIDAD TEREBINTO

Ubicación: Dentro del cantón de Terebinto

La comunidad de Terebinto, se encuentran situada a 32 kilómetros de Santa Cruz de la Sierra, en el municipio de Porongo. Esta comunidad, nació un 8 de septiembre de 1719, en la misma década de fundación del municipio de Porongo y lleva consigo una imponente historia que es ejemplo de vida para todos los visitantes y residentes de Santa Cruz. Caracterizado por ser un pueblo pintoresco, cálido y alegre, es la capital de su cantón y dentro de sus limitaciones, habitan 150 familias. Su iglesia, de fachada misional, fue reconstruida en el año 1998 y tiene como Santa Patrona a la Virgen de Alta Gracia, símbolo de devoción para todos los residentes de este hermoso pueblo, que ha sido testigo y protagonista de momentos cruciales en la historia de la región, es por eso que se lo conoce como el corazón latiente del municipio de Porongo. Sus valientes pobladores participaron activamente en las gestas libertarias de 1814, marcando un hito en la lucha por la independencia de Santa Cruz ante la corona española. De igual manera, en la década de los 50's, Terebinto se destacó nuevamente en la lucha por 11% de regalías, demostrando su firme compromiso con el desarrollo y el bienestar de la región. Esta comunidad fue declarada Patrimonio Histórico y Cultural Departamental, mediante Ley Departamental Nº 157, del 17 de mayo de 2018. En la actualidad, Terebinto te ofrece espacios verdes de esparcimiento, donde podrás realizar diferentes actividades al aire libre con tu familia y amigos. Podrás por ejemplo, tomar el cafecito de la tarde acompañado de un buen cuñapé o pan de arroz mientras aprecias la escena natural y relajante que te ofrece la comunidad. La plaza principal está rodeada de casas tradicionales, erguidas bajo los principios arquitectónicos coloniales, siendo un punto de encuentro para los locales y para los visitantes.

LA DANZA DE LOS TURCOS

Ubicación: Sobre Av. 24 de Junio, frente a la plaza principal de Porongo.

Esta danza típica se presenta una vez al año, por la mañana del 24 de julio, después de la celebración de la fiesta patronal de San Juan. La danza es una representación teatral y coreográfica de la batalla de moros y cristianos, misma que fue enseñada por los sacerdotes jesuitas como parte del proceso de colonización. Además de ser una forma de veneración, la Danza de los Turcos también desempeña un papel importante en el desarrollo artístico y musical de la comunidad. A través de la práctica y la actuación, los participantes honran y preservan una tradición que ha sido transmitida de generación en generación. Desde septiembre de 2023, la Danza de los Turcos ha sido declarada como Patrimonio Cultural Inmaterial del departamento de Santa Cruz, según la Ley Departamental N°305 del 14 de septiembre de 2023. Esta danza es una demostración de la creatividad y el ingenio del pueblo de Porongo, así como un homenaje a sus antepasados y a las influencias que han dado forma a su comunidad a lo largo del tiempo.

COMUNIDAD LA PERDIZ

Atención: Comunidad La Perdiz, Zona Bajío.

Con una historia arraigada en la tradición y el servicio, la ex llamada "Estancia El Bajío de La Perdiz" ha sido un punto de descanso para viajeros por generaciones, como lo cuentan las antiguas cartas cartográficas. Durante más de un siglo, este lugar emblemático ha sido testigo del ir y venir de cientos de carretones cargados con productos alimenticios que abastecen a la capital del departamento. Las familias tradicionales de La Perdiz se remontan a los años 1850. Al fundarse esta comunidad, solo contaba con 8 familias; con el paso de los años y después de la Guerra del Chaco, llegaron a ser 14 familias que habitaban la localidad. Esta comunidad se estableció como pascana obligatoria en las rutas de los viajeros, pues constituía un punto de seguridad y refugio en medio de los desafíos del camino para quienes llegaban a Santa Cruz.

CARNAVALITO DE PORONGO

Atención: Sobre Av. 24 de Junio, frente a la plaza principal de Porongo.

Una semana después del majestuoso carnaval cruceño, los porongueños celebran el denominado "Carnavalito", una representación auténtica de las festividades de antaño en el departamento de Santa Cruz. Durante este fin de semana, los comparseros llevan a cabo el simbólico entierro, donde cada comparsa local despide a su muñeco, marcando así el fin de la temporada festiva carnavalera. La fiesta del carnavalito, acompañada del uso tradicional de mascaritas, rinde homenaje a las raíces regionales y cuenta con la presencia destacada de la reina del carnaval de Santa Cruz y la comparsa coronadora del presente año. Este evento no solo te transportará a las profundidades de la cultura local, sino que también te permitirá sumergirte en las melodías tradicionales de la tamborita, creando una experiencia inolvidable.

FESTIVAL DE LA TAMBORITA

Atención: Sobre Av. 24 de Junio, frente a la plaza principal de Porongo.

Porongo celebra su rica herencia cultural con un evento que reune a todas las bandas de tamborita del municipio en su plaza principal. Desde los ritmos más enérgicos hasta las melodías más cautivadoras, este festival ofrece una experiencia cultural con un derroche de alegría especial que es característica del municipio. En este festejo, tanto locales como visitantes tienen la oportunidad de interactuar con apicultores locales. Estos expertos ofrecen productos naturales hechos de miel pura, perfectos para combatir el frío del invierno. Los asistentes a este festival también podrán llevarse un recuerdo de las hermosas artesanías elaboradas por mujeres emprendedoras, con su variedad de canastas hechas de bejuco y chuchio natural.

RANAS PORONGO

Ubicación: Calle s/n, a 2 cuadras de la plaza de Porongo diagonal al hospital municipal.
Atención: Viernes - 18:00 a 22:00; Sábados y Domingos - 11:00 a 16:00

ph: Ranas Porongo

Es un restaurante campestre situado a 18 km de la capital cruceña, especializado en carnes asadas a la leña. Este lugar se caracteriza por asar las costillas de cerdo y res durante más de 5 horas con leña seleccionada de curupaú, que les da un toque ahumado muy rico y no tan invasivo a las carnes. El lugar es maravilloso para pasar un tiempo en familia o con amigos. Está ubicado a dos cuadras de la plaza principal de Porongo y cuenta con piscina y habitaciones para aquellos que deseen descansar en contacto con la naturaleza.

CASA DEL CAMBA

DE PORONGO

Ubicación: A dos cuadras de la plaza principal de Porongo
Atención: Sábado y Domingo - 11:00 a 15:30

ph: Casa del Camba

La Casa del Camba de Porongo, inaugurada el 21 de junio de 2024, se encuentra a dos cuadras de la plaza principal. Esta sucursal conserva la temática tradicional y "camba" de la franquicia, con árboles frutales locales y una decoración acorde a la región. Ofrece un espacio de juegos para niños, ideal para disfrutar en familia. Además, dentro de la propiedad se encuentra una casona tradicional con un museo sobre la historia de Porongo. El restaurante sigue ofreciendo los platos típicos de la región, como majao, churrasco, keperí, picante de legua y masitas horneadas localmente. Es un lugar perfecto para disfrutés de una experiencia gastronómica y cultural en un ambiente único.

FERIA DEL PESCADO

Ubicación: En la plaza principal de Porongo

ph: GAMP

El municipio de Porongo se caracteriza por fusionar las tradiciones regionales con la fe católica. Una de esas fusiones es la Feria del Pescado, que se celebra el domingo de Ramos. Esta feria se lleva a cabo una semana antes de Semana Santa, en conmemoración de la llegada de Jesucristo a Jerusalén. En el municipio, la celebración comienza con una procesión de ramos de palma, que parte desde la casa "El Milagrito" hasta la plaza principal de Porongo, culminando con una misa de reflexión para los residentes. Durante ese día, en la misma plaza, se desarrolla la Feria del Pescado, donde piscicultores de múltiples localidades ponen en exhibición sus ofertas, desde la venta de pescado crudo hasta curiosos platos de pescado tradicionales de la región. Pacú, Paiche y Sábalo son algunos de los pescados más representativos que encontrarás en este evento, además de bebidas tradicionales como el somó y el mocochinchi. El evento se desarrolla acompañado de la alegría de los residentes y múltiples visitantes de todos los municipios que conforman la Región Metropolitana.

FESTIVAL DEL ACHACHAIRÚ

Ubicación: Av. 24 de Junio, en la plaza principal de Porongo.

ph: GAD SCZ

El festival del achachairú es una oportunidad para que todo aquel que visita el municipio de Porongo pueda disfrutar del sabor de esta fruta y de su textura suave y peculiar. Realizado en el último mes de la cosecha (que suele ser en enero), este festival organiza una variedad de actividades, siendo la principal la presentación de un sinfín de platos y bebidas elaborados con achachairú (desde jugos y postres hasta platos principales y salsas). Todo esto culmina en concursos para premiar a los mejores productos y recetas, como las mermeladas, conservas, dulces y más.

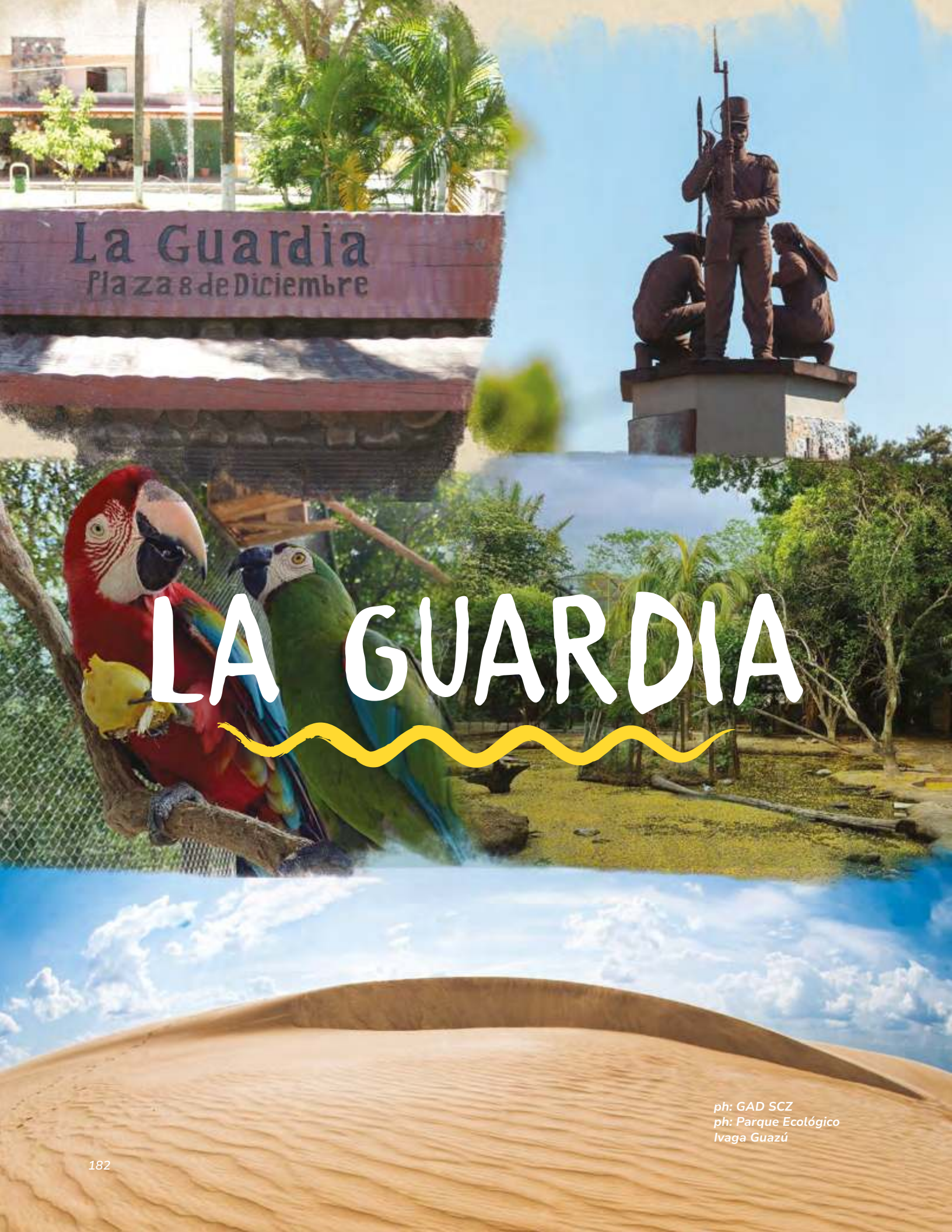

LA GUARDIA

ph: GAD SCZ
ph: Parque Ecológico Ivaga Guazú

LA GUARDIA

Provincia Andrés Ibañez
Fundación: 26 de noviembre de 1826

CLIMA

Temperatura media mensual de 26,7°C

DATOS DEMOGRÁFICOS

Gentilicio Guardieño (a)
Población (2023)[1]**:** 165.726 habitantes
Densidad (2023): 133 hab./km²

DATOS GEOGRÁFICOS

Ubicación: 17 kilómetros al suroeste de la ciudad de Santa Cruz de la Sierra

Coordenadas: 17°53'31"S 63°19'52"O

Superficie: 1.244 km²

Altitud : 506 m s.n.m..

ECONOMÍA

Economía[2]**:** Las actividades económicas más importantes son manufactura y pecuario, que de acuerdo al Valor Bruto de Producción (VBP) del municipio representan el 44.53% y 25.13% respectivamente.

[3] El Municipio cuenta con 22 industrias dedicadas a diferentes actividades, muchas de ellas emprendidas por esfuerzos familiares, catalogadas como pequeñas industrias:

• Alimenticias, siendo considerado este rubro muy importante en la transformación de la materia prima (derivados de la miel).

• Artesanales, habiéndose desarrollado fruto de diversas manifestaciones de la región, generando ello empleo permanente y eventual en las diferentes actividades, como el tallado de madera, trabajos en barro, el tejido, costura, la repostería, la panadería, entre otros más.

• Servicios, tales como chapería y pintura, muellería, remachado de balatas, soldadura en arco eléctrico y oxígeno.

• Desarrollo de la actividad de las Tejerías y Ladrilleras, cuya finalidad es la fabricación de ladrillo tipo gambote o adobe, gracias al aprovechamiento de los yacimientos de arcilla de la zona, actividad en la cual se emplean insumos como; aserrín, leña, chala, que son aprovisionados por la zona. Cabe destacar que la fabricación es manual, lo único que se utiliza, son hornos para el secado de los ladrillos.

Valor Bruto de Producción (VBP)[4]**:** 225 MM Bs.

---

[1] Encuesta de Estimación Poblacional de Santa Cruz 2023. Instituto Cruceño de Estadística
[2] Mapa de Complejidades, BDP 2019
[3] PTDI del Municipio de La Guardia 2015 – 2019
[4] Mapa de Complejidades, BDP 2019

LA GUARDIA

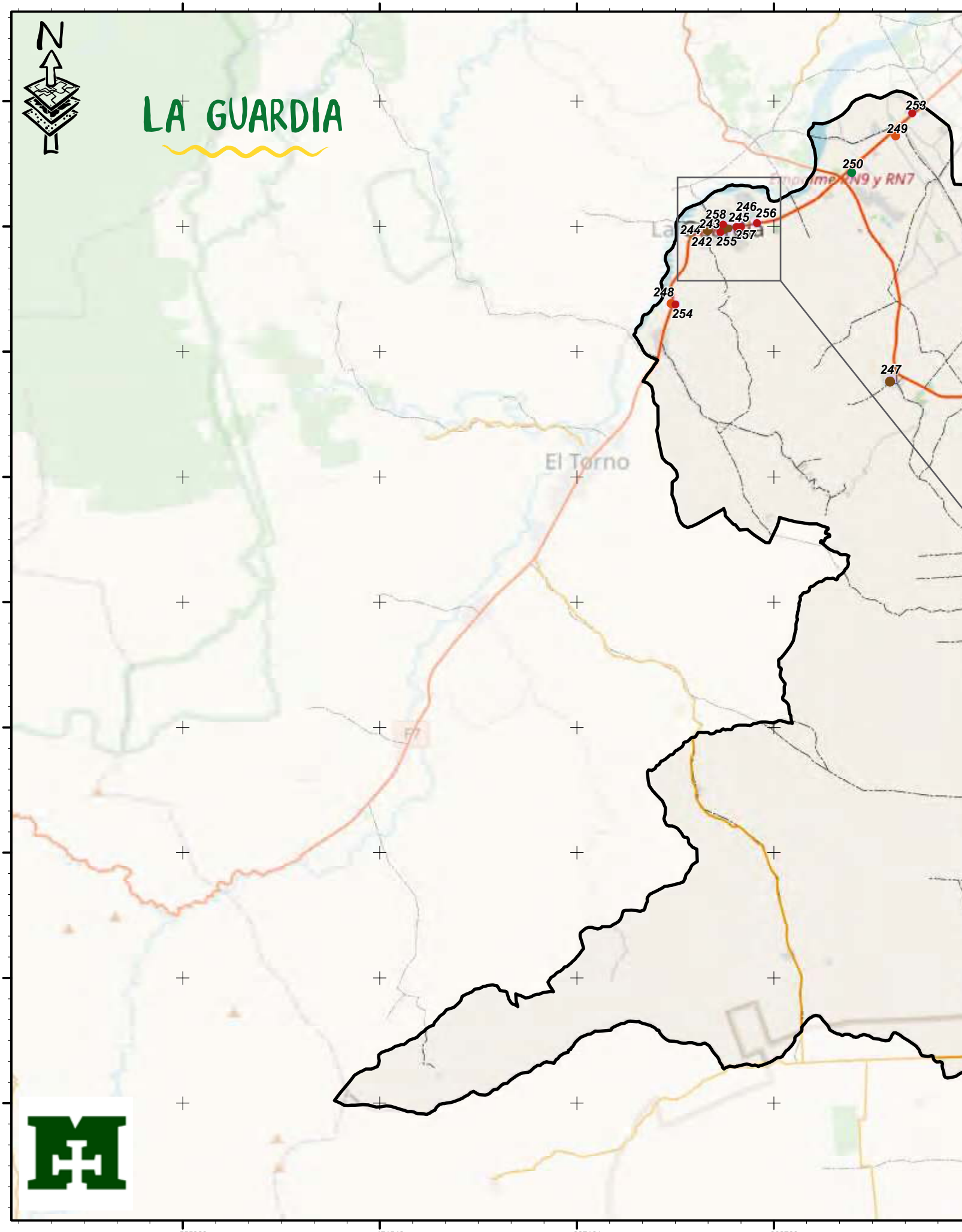
N
-63.555923
-63.471542
-63.387161
-63.302780
-17.837354
-17.891020
-17.944686
-17.998352
-18.052018
-18.105684
-18.159350
-18.213016
-18.266682
253
249
250
RN9 y RN7
246
258
245
256
243
244
257
242
255
248
254
247
El Torno

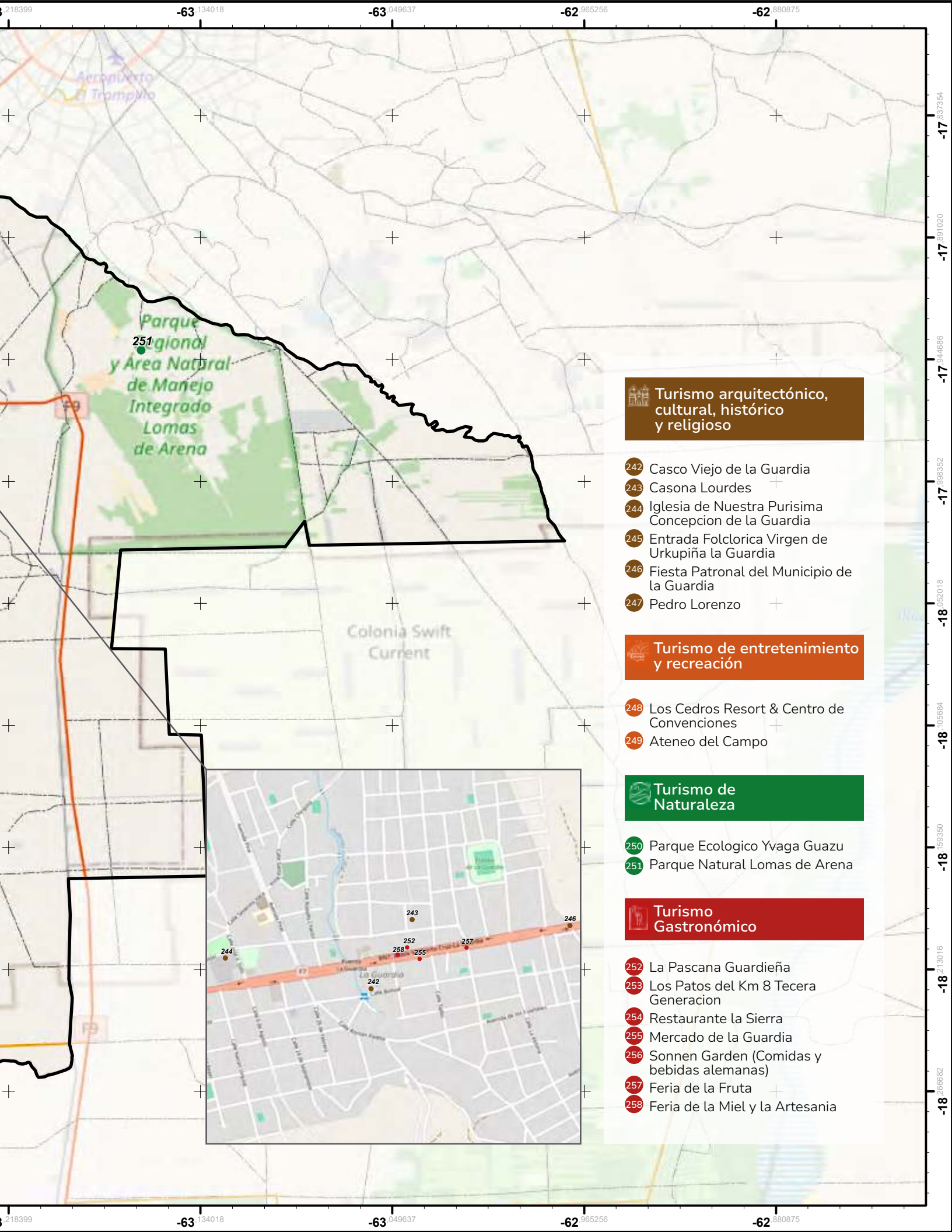
-63.218399
-63.134018
-63.049637
-62.965256
-62.880875
-17.837354
-17.891020
-17.944686
-17.998352
-18.052018
-18.105684
-18.159350
-18.213016
-18.266682
Aeropuerto El Trompillo
Parque Regional y Área Natural de Manejo Integrado Lomas de Arena
251
Colonia Swift Current
243
246
244
252
258
255
257
242
La Guardia
Turismo arquitectónico, cultural, histórico y religioso
242 Casco Viejo de la Guardia
243 Casona Lourdes
244 Iglesia de Nuestra Purisima Concepcion de la Guardia
245 Entrada Folclorica Virgen de Urkupiña la Guardia
246 Fiesta Patronal del Municipio de la Guardia
247 Pedro Lorenzo
Turismo de entretenimiento y recreación
248 Los Cedros Resort & Centro de Convenciones
249 Ateneo del Campo
Turismo de Naturaleza
250 Parque Ecologico Yvaga Guazu
251 Parque Natural Lomas de Arena
Turismo Gastronómico
252 La Pascana Guardieña
253 Los Patos del Km 8 Tecera Generacion
254 Restaurante la Sierra
255 Mercado de la Guardia
256 Sonnen Garden (Comidas y bebidas alemanas)
257 Feria de la Fruta
258 Feria de la Miel y la Artesania

PARQUE NATURAL

LOMAS DE ARENA

Ubicación: 12 Km. al sureste de la ciudad de Santa Cruz de la Sierra
Atención: Lunes a domingo: De 08:00 a 14:00 Hrs.

ph: GAD SCZ

Ubicado en el departamento de Santa Cruz, la UCPN Parque Natural y Unidad Natural de Manejo Integrado Lomas de Arena se extiende sobre una impresionante superficie de 14,075.9 hectáreas y está ubicado a 12 kilómetros de la capital cruceña. Este paraíso natural alberga las comunidades de Palmar Tapera, Aguaíces, Las Lomitas y Oliveira. Te deleitarás con sus paisajes únicos, caracterizados por dunas de arena sin vegetación y lagunas estacionales, que crean un escenario de belleza natural. El parque es un santuario para los amantes de la naturaleza y la ornitología, ya que alberga el 21% de las aves registradas en el país. Son un total de 286 especies distribuidas en 52 familias que encuentran refugio en sus humedales e islas de bosques.

Además, el Centro de Interpretación del parque te ofrece una valiosa oportunidad educativa y de interpretación ambiental. Coordinando previamente, podrás disfrutar de recorridos especializados para la observación de aves, la vegetación y las impresionantes dunas de arena. Uno de los grandes atractivos del parque es el sendero ecológico, donde podrás dar paseos en carroza o a caballo por un sendero espectacular que se extiende por 5 kilómetros. Este recorrido ofrece la oportunidad de experimentar las dunas y el sol en un entorno natural inigualable. Asimismo, el sitio arqueológico en la zona de Los Chivatos revela restos de cerámicas pertenecientes al cementerio Chané, siendo hasta la fecha el único sitio arqueológico remanente de esta cultura. Para llegar, tenés que tomar la avenida Santos Dumont hasta la refinería Palmasola. Desde allí, debés seguir las señalizaciones que orientan hasta llegar al parque. Te recomendamos usar un vehículo 4x4, ya que es la única forma de desplazarse en motorizado dentro del parque, además de ingresar a pie.

ph: GAD SCZ

ph: Yvaga Guazú

ph: Yvaga Guazú

El Parque Ecológico Yvaga Guazú, lleva un nombre que en la lengua guaraní se traduce como “paraíso grande”. Este parque es conocido por su belleza paisajística, ya que alberga una gran diversidad de flora y fauna, incluyendo bosques, humedales, lagunas y cursos de agua. El parque cuenta con una variedad de 15 senderos que varían en dificultad y longitud: desde paseos cortos adecuados para toda la familia hasta rutas más extensas para los excursionistas más aventureros. En estas rutas, podrás observar alrededor de 800 especies de plantas nativas y exóticas, incluyendo una colección de 200 especies de orquídeas. Además, el parque es hogar de tucanes multicolores y más de 135 especies de mariposas. Es un atractivo ideal para los entusiastas del aviturismo. También podrás observar animales como tortugas de agua y tierra, monos, loros, venados, taitetuses, iguanas, jochis, perezosos y ardillas. Este encantador lugar ofrece programas de educación ambiental para aquellos interesados en aprender sobre la flora, fauna y ecología del parque. Se llevan a cabo esfuerzos para proteger

ph: Yvaga Guazú

la biodiversidad, controlar la actividad humana y promover el turismo responsable y sostenible en la zona, por lo que también funciona como un refugio de animales, a pesar de ser de carácter privado. El parque ofrece todos los servicios básicos, como baños, áreas de descanso, señalética y un espacio de estacionamiento para vehículos. Ha sido reconocido como el primer parque certificado por Green Globe 21 en América del Sur, un sistema de certificación en sostenibilidad desarrollado exclusivamente para la industria del turismo. El Parque Ecológico Yvaga Guazú es un tesoro natural que brinda la oportunidad de conectarse con la naturaleza y disfrutar de su belleza y biodiversidad. Con sus senderos pintorescos, oportunidades de observación de aves y actividades al aire libre, el parque es un destino ideal para quienes buscan aventura y tranquilidad en un entorno natural único.

ph: Yvaga Guazú

ph: Yvaga Guazú

ph: Yvaga Guazú

ph: Yvaga Guazú

ph: Los Cedros

ph: Los Cedros

Los Cedros es un impresionante destino que te ofrece lujo y comodidad, rodeado de un entorno natural imponente. Es un resort que brinda todas las comodidades necesarias, desde una atención de excelente calidad hasta instalaciones bien equipadas. Podrás disfrutar de nadar en las múltiples piscinas del resort, accesibles tanto para niños como para adultos. Además, tendrás acceso a una variedad de saunas, tanto secos como húmedos, y a un spa totalmente equipado con servicios estéticos y de atención personal. Este exclusivo resort cuenta con numerosos espacios para el entretenimiento, como una cabaña de karaoke, donde podrás poner a prueba tus habilidades vocales junto a tus seres queridos. También encontrarás áreas de juego como ping-pong y billar. Las cabañas de hospedaje están diseñadas con todas las dependencias de un hogar, permitiéndote experimentar lo más cercano a estar en casa. Los Cedros te ofrece un servicio integral: como centro de convenciones, posee salones de eventos para diversas actividades, como congresos, bodas y cumpleaños, además de contar con espectaculares vistas.

ph: Los Cedros

La Sierra ofrece una experiencia culinaria inigualable con la oferta platos de pato, pacumuto y chancho. Con capacidad para 200 personas, este lugar no solo deleita con su comida, sino también con una vista panorámica del río Piraí. Además, cuenta con un pequeño zoológico con parabas azules y otros animales, cuidado y administrado por los dueños. Esta abierto los fines de semana y días festivos.

ph: La Sierra

ph: La Sierra

ph: La Sierra

MERCADO MUNICIPAL

DE LA GUARDIA

Ubicación: Km 13 Av. Doble vía La Guardia
Atención: Lunes: 07:00 a 22:00 Hrs.
Martes a domingo: 07:00 a 20:30 Hrs.

El Mercado de La Guardia ofrece una auténtica experiencia gastronómica. Aquí podés disfrutar de platos típicos del municipio de La Guardia, como un locro de gallina criolla, una sopa de maní, y el delicioso asadito colorado, todo a precios muy accesibles, desde Bs 10. Abierto todos los días, este mercado es el lugar perfecto para explorar la cocina local y disfrutar de sabores auténticos sin gastar mucho.

PATOS DEL KM 8

Ubicación: Av. Doble Vía la Guardia, Km. 8
Atención: Viernes a domingo: 11:00 a 17:00 Hrs

Los patos del KM 8 es un destino culinario con 45 años de historia, siendo uno de los primeros establecimientos en el departamento de Santa Cruz en ofrecer pato al horno. Con una capacidad para albergar hasta 200 personas, este restaurante se destaca por su ambiente acogedor y su atención continua de viernes a domingo, todos los días del año. Además, cuenta con un parque infantil y un estacionamiento interno con guardias de seguridad. Sí pasás por la Guardia, no perdás la oportunidad de disfrutar esta experiencia.

FIAMBRERÍA

HELMUT'S DELICATTSSEN

Ubicación: Km 17, Doble vía La Guardia

Fiambrería Helmut's Delikatessen ofrece platos típicos alemanes y una gran variedad de ensaladas. Dirigida por propietarios alemanes, es una opción familiar ideal con precios desde Bs 32. Abierto de martes a domingo, este acogedor establecimiento es perfecto para disfrutar de auténticos sabores en un ambiente familiar.

SONNENGARTEN

Ubicación: Km 17, Doble vía La Guardia
Atención: Lunes a domingo: 10:00 a 18:00 Hrs

Sonnengarten ofrece auténticos platos alemanes como Bratwurst (salchicha para asar) y Schnitzel (chuleta de ternera) junto con innovaciones culinarias. Su amplia variedad de cervezas alemanas y cócteles de autor completa una experiencia ideal para vos, amante de la buena comida y bebida. Además, el ambiente relajante y el aire puro hacen de Sonnengarten un lugar perfecto para disfrutar en compañía de amigos y familiares.

FERIA DE LA MIEL Y ARTESANÍA

Ubicación: Km 13, Doble vía La Guardia

Este evento se lleva a cabo en el frontis del Mercado Municipal de La Guardia. En la feria participarán alrededor de 50 productores, incluidos apicultores y artesanos del municipio, quienes demostrarán lo mejor de su producción en derivados de la miel y una variedad de productos artesanales locales. Cada apicultor trabaja la miel en plantas naturales y barbechos o cultivos frutales mediante abejas que la almacenan en colmenas. La producción por año, ha llegado a alcanzar los 13.000 kilos entre todos los asociados.

LA PASCANA GUARDIEÑA

Ubicación: Km. 12, Doble Vía La Guardia
Atención: Sábado y domingo: 10:00 a 18:00 Hrs.

ph: La Pascana Guardieña

La Pascana es conocida hace varias décadas por el excelente servicio que ofrece, los deliciosos platillos nacionales que sirven, además del cálido y acogedor ambiente que brinda. Hoy en día, se ha establecido como un referente de la gastronomía tradicional para todo aquel visitante que se da cita en La Guardia. Doña Maritza, quien dirige el negocio, está al tanto del servicio del personal y se asegura que los comensales reciban productos de calidad. Desde un delicioso keperí, el sabroso majao, una exquisita y tradicional sopa de maní, un locro carretero y un churrasco preparado con la mejor carne y con manos profesionales, son algunos de los manjares que podrás disfrutar aquí. Además, la construcción de madera tiene la imagen de una infraestructura misional chiquitana, junto con una amplia área de juegos para niños, para que los padres puedan disfrutar de un tiempo de sobremesa compartiendo un cafecito, un budín, leche crema o arroz con leche. La Pascana Guardieña, es un símbolo de tradición y cultura, una parada obligatoria si visitás el municipio de La Guardia.

ph: GAD SCZ

ph: GAD SCZ

CASCO VIEJO

DE LA GUARDIA

Ubicación: Alrededor de la plaza principal del municipio de La Guardia

ph: GAD SCZ

El Casco Viejo de La Guardia es un verdadero tesoro histórico que te cautivará con sus amplios espacios, sus calles empedradas y su encantador ambiente pintoresco. La Guardia se presenta como un atractivo urbano que fusiona lo tradicional con lo moderno. En su parte urbana, podrás apreciar una variedad de edificaciones que van desde las antiguas y tradicionales, construidas con materiales locales, de aspecto frágil y romántico, hasta aquellas de aspecto robusto y moderno en constante crecimiento. Fundado el 26 de julio de 1857, el nombre de La Guardia se remonta a los tiempos en que el Coronel Ignacio Warnes, gobernador de la Republiqueta de Santa Cruz de la Sierra, quien estableció un grupo de soldados en la zona para vigilar la llegada de gente y tropas realistas desde el altiplano. En el Casco Viejo, podrás visitar la Plaza Principal 8 de diciembre, el edificio de la Alcaldía, la tradicional Pascana Guardieña y casas antiguas, todo acompañado de vecinos que transmiten por las calles ese espíritu de tranquilidad y hospitalidad. ¡No te quedés sin conocer este precioso lugar!

ph: GAD SCZ

ph: GAD SCZ

IGLESIA DE NUESTRA PURÍSIMA CONCEPCIÓN DE LA GUARDIA

Ubicación: Frente a la plaza principal Doble Vía la Guardia

Esta parroquia abrió sus puertas al público en el año 2019. Lo que comenzó como el sueño de ser un simple salón parroquial, terminó siendo una parroquia totalmente nueva. Fue construida con la colaboración de muchas personas, entre asistentes, grupos de infancia y adolescencia misionera, hermanas de otra orden, estudiantes de colegios, profesores y el Gobierno Municipal. El principal benefactor fue Adalid Novillo y su familia, quienes donaron el 80 % de los recursos para la construcción del nuevo Templo. Para aquellos creyentes devotos, la iglesia posee en el altar dos reliquias invaluables: algunos cabellos del extinto papa Juan Pablo II y parte de la túnica del papa Juan XXIII.

ENTRADA FOLCLÓRICA VIRGEN DE URKUPIÑA

Ubicación: A 1 Km. de Plaza Principal de La Guardia

Cada tercer domingo de agosto, el municipio de La Guardia celebra con gran fervor la festividad dedicada a la Virgen de Urkupiña. Desde que fue nombrada Patrona de la Integración Nacional en 1998, esta festividad se celebra en varios departamentos y atrae a numerosos fi eles de todo el país. La celebración comienza con una emotiva procesión desde las primeras horas del domingo, que se dirige hacia el cerro más cercano del municipio. Las fraternidades locales, acompañadas de música en vivo, con bailarines y bandas, enriquecen el ambiente festivo

FIESTA PATRONAL DEL MUNICIPIO DE LA GUARDIA

Ubicación: Frente a la plaza principal Doble Vía la Guardia

La fiesta patronal se celebra cada 12 de diciembre. Los habitantes se reúnen en la iglesia, adornada con flores y velas, para una misa en honor a la "mamita de La Guardia" seguida de un sermón. Luego, se realiza la Procesión Solemne con La Purísima Concepción, acompañada por el párroco, autoridades y fieles. Al caer la noche, las festividades continúan en la plaza del municipio con actividades como el lanzamiento del globo, la tamborita y la degustación de comidas típicas.

CASONA LOURDES

Ubicación: Dentro de Localidad Pedro Lorenzo.

Es una antigua propiedad en la comunidad de Pedro Lorenzo, municipio de La Guardia, que alberga la historia de Miguel Hignicio Velasco, quien inició el proceso de refinación de gasolina en el departamento. En la casona se conservan los utensilios utilizados en este proceso, y la infraestructura mantiene el estilo colonial característico de las casas de campo de la época.

PEDRO LORENZO

Ubicación: Km 14, Doble vía la Guardia, carretera 7

Pedro Lorenzo es una pintoresca comunidad rodeada de granjas y cultivos, con un ambiente apacible y un clima templado durante la mayor parte del año. Su nombre proviene de los hermanos Pedro y Lorenzo, los primeros habitantes de la zona. La comunidad, que ofrece una visita agradable en cualquier estación, destaca por su hermosa iglesia dedicada a la Virgen de Fátima, patrona local.

ATENEO DEL CAMPO

Ubicación: Avenida Mapaizo 125, Av Doble Vía Km 9 Santa Cruz de la Sierra
Atención: Lunes a viernes 15:00 a 20:00 Hrs.
Sábado: 10:00 a 20:00 Hrs. Domingo: 15:00 a 20:00 Hrs.



ph: GAD SCZ

ph: GAD SCZ

El Ateneo del Campo es mucho más que una librería; es un santuario cultural que cautiva a los amantes del arte y la literatura por igual. Con una vasta colección de libros que abarcan desde clásicos literarios hasta obras contemporáneas, este espacio te ofrece un refugio acogedor para que te sumerjas en el mundo de la imaginación y el conocimiento.

ph: Maluc Art Sanji

En este lugar, tendrás la oportunidad de explorar dos circuitos distintos: por un lado, te encontrarás con salas repletas de réplicas de algunas de las obras de arte más célebres de la historia universal, como las de Leonardo da Vinci, Diego Velásquez, entre otros. Por otro lado, el circuito dedicado a los artistas nacionales te ofrece una mirada íntima a la creatividad local. Los espacios abiertos, la oferta gastronómica y los ambientes de lectura te permitirán vivir una encantadora experiencia llena de arte y tranquilidad.

ph: GAD SCZ

EL TORNO

EL TORNO

Provincia Andrés Ibañez
Fundación: 19 de junio de 1957

DATOS GENERALES

Declarado “Patrimonio Cultural y Religioso de Bolivia” en el año 2003.
Huso horario: UTC-4
Moneda: Boliviano
Prefijo telefónico: +591 (3)

DATOS DEMOGRÁFICOS

Gentilicio: Torneño (a)
Población (2023)[1]: 67.091 habitantes
Densidad (2023): 67 hab./km²

CLIMA

Clima: tropical húmedo – seco

Temperatura promedio: 24.77 °C., con una variación moderada a lo largo del año, siendo ligeramente superior la temperatura los meses de octubre a febrero y de mayo a agosto los meses más fríos.

DATOS GEOGRÁFICOS

Ubicación: 36 kilómetros al suroeste de la ciudad de Santa Cruz de la Sierra, sobre la ruta hacia la localidad de Samaiptata, antigua carretera a Cochabamba.

Coordenadas: 18°03'S 63°27'O

Superficie: 993,15Km²

Altitud : varían de 490 m s.n.m. (zona de Santa Martha) a 1.780 m s.n.m. (zona de Villa Paraíso o Cajones)

ECONOMÍA

Economía[2]: Las actividades económicas más importantes son el pecuario y el agrícola, que de acuerdo al Valor Bruto de Producción (VBP) del municipio representan el 59.91% y 27.14% respectivamente.

[3] El municipio tiene un fuerte énfasis en la producción de frutas y la ganadería con su componente de feria de comercialización de ganado, el aprovechamiento de áridos y agregados complementados por el turismo y el comercio.

Valor Bruto de Producción (VBP)[4]: 732 MM Bs.

---

[1] Encuesta de Estimación Poblacional de Santa Cruz 2023. Instituto Cruceño de Estadística
[2] Mapa de Complejidades, BDP 2019
[3] PTDI del Municipio de El Torno 2015 – 2019
[4] Mapa de Complejidades, BDP 2019

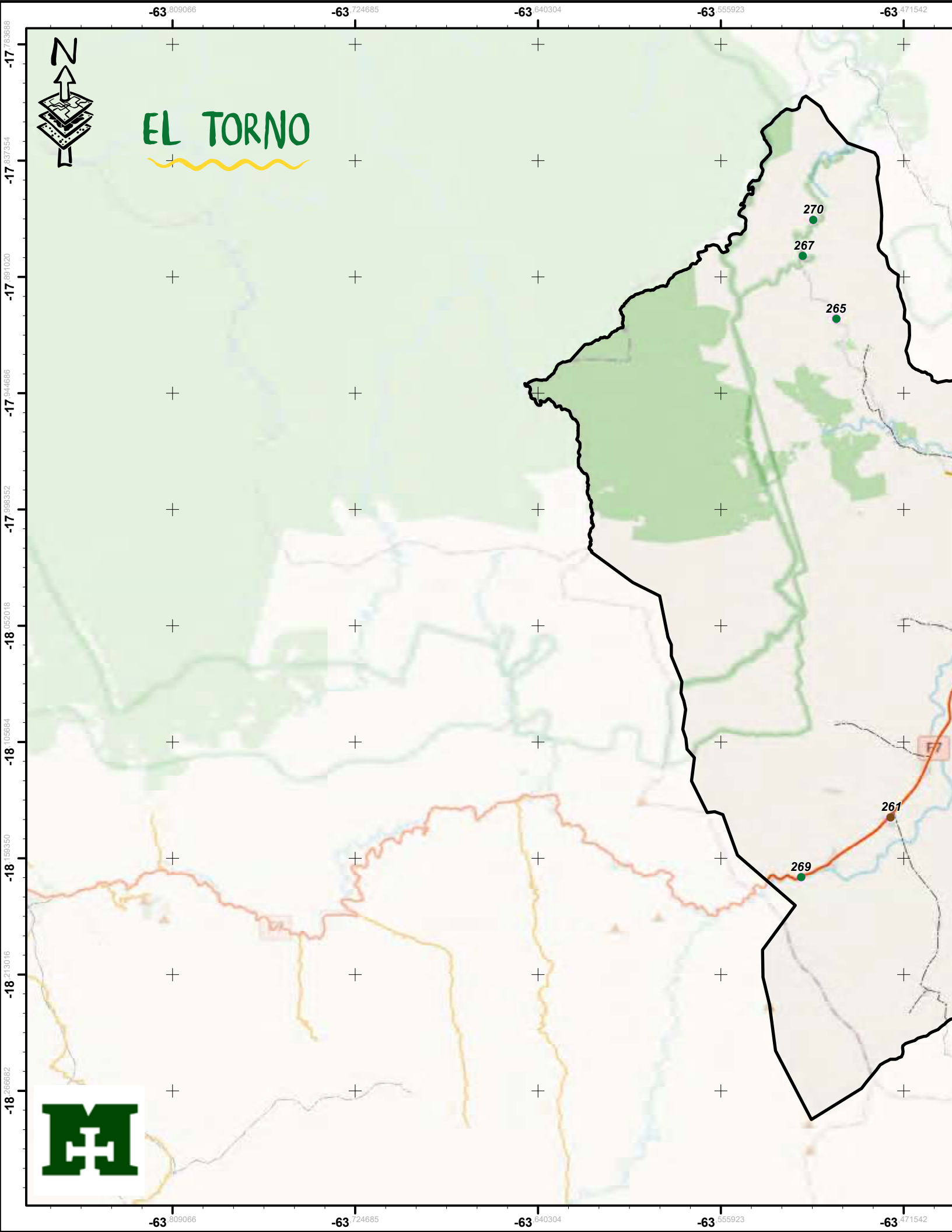
EL TORNO
N
270
267
265
261
269
-63.809066
-63.724685
-63.640304
-63.555923
-63.471542
-17.783688
-17.837354
-17.891020
-17.944686
-17.998352
-18.052018
-18.105684
-18.159350
-18.213016
-18.266682

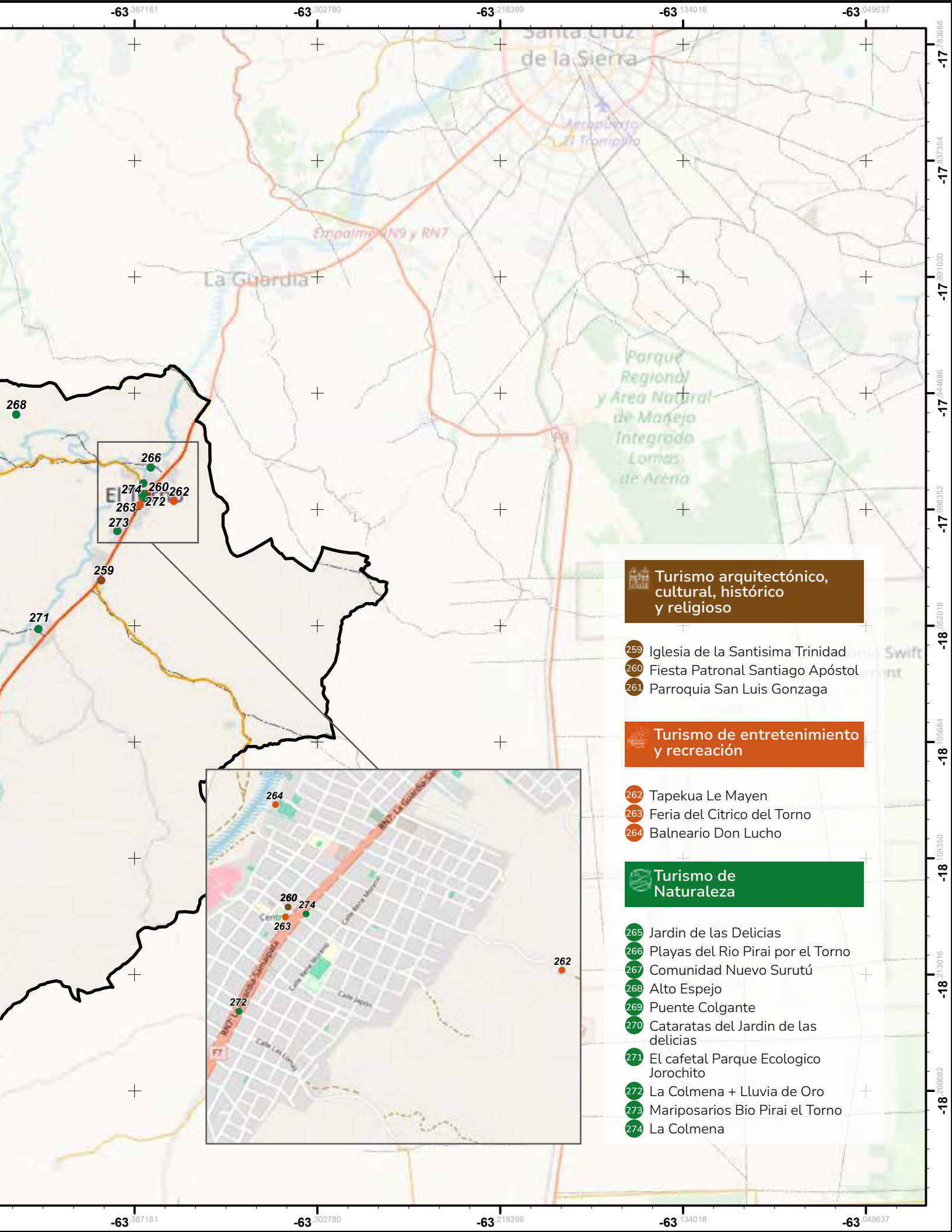
Santa Cruz de la Sierra
Aeropuerto El Trompillo
Empalme RN9 y RN7
La Guardia
Parque Regional y Área Natural de Manejo Integrado Lomas de Arena
El Torno
268
266
274
260
262
272
263
273
259
271
264
260
274
263
262
272
Turismo arquitectónico, cultural, histórico y religioso
259 Iglesia de la Santisima Trinidad
260 Fiesta Patronal Santiago Apóstol
261 Parroquia San Luis Gonzaga
Turismo de entretenimiento y recreación
262 Tapekua Le Mayen
263 Feria del Citrico del Torno
264 Balneario Don Lucho
Turismo de Naturaleza
265 Jardin de las Delicias
266 Playas del Rio Pirai por el Torno
267 Comunidad Nuevo Surutú
268 Alto Espejo
269 Puente Colgante
270 Cataratas del Jardin de las delicias
271 El cafetal Parque Ecologico Jorochito
272 La Colmena + Lluvia de Oro
273 Mariposarios Bio Pirai el Torno
274 La Colmena
-63.387161
-63.302780
-63.218399
-63.134018
-63.049637
-17.783688
-17.637354
-17.691020
-17.944686
-17.998352
-18.052018
-18.105684
-18.159350
-18.213016
-18.266682

JARDÍN DE LAS DELICIAS

Ubicación: Carretera antigua a Cochabamba, Km. 36
Atención: Lunes a domingo 08:00 a 18:00 Hrs.

ph: GAD SCZ

ph: Jardín de las Delicias

En el municipio de El Torno, dentro del Parque Nacional Amboró, encontrarás un paraíso terrenal llamado el Jardín de las Delicias. Este destino turístico ubicado a 36 kilómetros de la capital cruceña, es conocido por su belleza y entorno sereno, te ofrece una experiencia inolvidable de conexión con la naturaleza y aventura. Desde sus imponentes cascadas hasta su asombrosa vegetación, el Jardín de las Delicias es un lugar mágico que invita a explorar y maravillarse ante la grandeza de la madre naturaleza. Las cascadas como tesoro escondido, están situadas en un área remota y rodeadas de densa vegetación y ofrecen un refugio tranquilo, sereno lejos del bullicio de la vida urbana. Para llegar a ellas, tendrás que aventurarte a través de senderos sinuosos y bosques, agregando emoción y aventura a la experiencia. Una vez dentro de las cascadas, serás recibido por una vista impresionante: una cascada majestuosa que cae desde lo alto de un acantilado rocoso hacia una piscina natural de aguas cristalinas. El sonido del agua golpeando las rocas y el rocío que llena el aire crean una atmósfera mágica y revitalizante, que cautivará tus sentidos. Gracias al emprendimiento de los comunarios, al llegar podrás acceder a una excelente infraestructura, apta para recibir a los turistas. El lugar cuenta con habitaciones confortables, baños, duchas, cocina, espacios de comedor para reuniones y área de camping, todo rodeado de la espectacular naturaleza de la zona. Además de maravillarse ante la belleza, también podrás disfrutar de una variedad de actividades emocionantes y explorar la vida silvestre, desde nadar en las piscinas naturales hasta hacer senderismo por los alrededores y observar aves exóticas. En el Jardín de las Delicias, la preservación y conservación de la biodiversidad es una prioridad fundamental. Este paraíso natural, que alberga variedad de especies vegetales y animales, se esfuerza por proteger su entorno único y promover la sostenibilidad ambiental. El lugar se compromete a conservar y proteger los hábitats naturales que albergan especies vegetales y animales. Se llevan a cabo programas de monitoreo de especies y además de promover la educación ambiental entre los visitantes y la comunidad local.

ph: Jardín de las Delicias

ALTO ESPEJO

Ubicación: Km 42, carretera antigua a Cochabamba.

ph: Viva Santa Cruz

La comunidad de Alto Espejo te ofrece una combinación única de paisajes escénicos, biodiversidad sorprendente y emocionantes oportunidades para la aventura al aire libre. Cuenta con una cascada muy alta que, hoy por hoy, se conoce como un refugio sereno y tranquilo, lejos del bullicio de la ciudad. Entre las características de esta comunidad están sus impresionantes paisajes, salpicados de valles verdes y cascadas cristalinas. Entre sus atractivos turísticos se encuentran El Salto Alto Espejo, la Poza de la Luna, y las pozas sobre el arroyo Alto Espejo. También hay una caída de agua que forma una piscina natural sobre otro brazo del arroyo Alto Espejo, y un espectacular mirador desde donde se puede ver incluso hasta el municipio de La Guardia y sus alrededores. Varias operadoras turísticas ofrecen servicios en esta comunidad. Te recomendamos que vayas en grupo y con personas capacitadas y conocedoras de la zona. La actividad extrema que se realiza es el rappel, que consiste en el descenso por una cascada de 60 metros, ubicada a una hora a pie del ingreso. Además, tenés opciones para descansar en las aguas de los ríos cercanos, lo que te brinda una manera relajante de explorar la belleza natural de la región. El senderismo y el ciclismo extremo son otras de las actividades destacadas en esta zona, donde los recorridos te permiten disfrutar de la impresionante biodiversidad y los paisajes que ofrece el Parque Amboró. Estos recorridos no solo son una excelente forma de ejercitarte, sino que te brindan la oportunidad de explorar a fondo este paraíso natural, en un clima húmedo caracteristico de Parque Amboró. Recordá que el viaje a Alto Espejo dura aproximadamente dos horas, y se recomienda hacerlo en grupo y con guías locales que conozcan bien el terreno y las condiciones del lugar. ¡Vení y conocé esta maravilla natural!

CASCADA NATURAL
EL CHORRITO

Ubicación: Km 63, La Angostura, El Torno

En la comunidad de La Angostura, en El Torno, se encuentra un tesoro natural escondido: El Chorrito. Esta impresionante cascada es un lugar que debes visitar con amigos, familia o pareja. El viaje en transporte público dura aproximadamente dos horas. Al desembarcar, después de unos diez minutos de caminata, encontrarás cabañas con techos de hatata, ideales para disfrutar de un churrasco tradicional o descansar a la sombra. Un dato interesante es que antes de la riada de 1983, El Chorrito era un pequeño pueblo en El Torno con 17 casas, 3 hoteles y una iglesia. Hoy, solo quedan los restos como recuerdo de aquella tragedia. Se dice que el puente circular de estilo colonial de El Chorrito causó el desbordamiento. Al acumularse árboles y piedras, el puente colapsó, llevando la destrucción al pueblo y luego al puente de Tarumá, alcanzando hasta la capital cruceña.

PUENTE COLGANTE
DE EL TORNO

Ubicación: Km. 35 por carretera principal, el Torno

El Puente Colgante de El Torno se encuentra sobre el río Grande, en la localidad de Jorochito, situada a aproximadamente 35 kilómetros al suroeste de la ciudad de Santa Cruz de la Sierra, capital del departamento. Este atractivo, es un puente colgante de tipo peatonal que conecta las dos orillas del río Grande. Está construido principalmente con cables de acero y tablones de madera, y su diseño colgante permite que se balancee ligeramente cuando las personas caminan sobre él. Muchos visitantes, tanto locales como extranjeros, acuden al puente para disfrutar de las vistas panorámicas del río y de la experiencia única de cruzarlo a pie mientras se balancea suavemente. Además, podrás obtener unas excelentes fotografías que capturen la escena natural que representa a El Torno, vení y disfrutá de esta experiencia.

EL MARIPOSARIO
BIO PIRAÍ

Ubicación: Carretera antigua a Cochabamba, Km. 37, Localidad El Torno
Atención: Lunes a domingo: 09:00 a 18:00 Hrs

El Mariposario Bio Piraí es una empresa familiar dedicada a la reproducción y exhibición de mariposas con fines educativos, científicos, recreativos y económicos. Cuenta con un área de vuelo de 400 m²", donde se reproducen y sobrevuelan múltiples variedades de mariposas. Tiene en reproducción 13 diferentes especies de mariposas diurnas en ciclo cerrado, a partir de las parentales de la zona. Al visitarlo, además de poder disfrutar de los lepidópteros, podrás relajarte en las piscinas, acompañado de la belleza natural en la comunidad de Puerto Rico, El Torno.

EL CAFETAL
PARQUE ECOLÓGICO JOROCHITO

Ubicación: Km 42, Jorochito, antigua carretera a Cochabamba
Atención: De acuerdo a coordinación con la administración.

Ubicado en el pintoresco municipio de El Torno, a solo 42 kilómetros de la capital cruceña, el Cafetal Jorochito es un encantador destino ecológico que te invita a conectar con la naturaleza. Aquí podrás disfrutar de un entorno natural único y disfrutar de las cosechas que aquí existen, además de compartir un churrasco en familia. El Cafetal Jorochito también ofrece guiados que te permitirán conocer la historia del parque y su entorno. Los horarios de apertura se coordinan según el grupo con la administración del lugar, asegurando una experiencia personalizada y adaptada a tus necesidades.

COMUNIDAD

NUEVO SURUTÚ

Ubicación: Km 37, antigua carrera a Cochabamba

ph: AENS

La Comunidad Nuevo Surutú es un enclave rural, ubicado en un entorno natural ofrece a los visitantes una experiencia auténtica, permitiéndoles sumergise en la vida cotidiana de la población local y descubrir la belleza y la simplicidad de la vida en el campo. En Nuevo Surutú encontrarás alrededor de 17 piscinas naturales, con profundidades que varían de uno a cinco metros, distribuidas en diferentes senderos. Una de las características más distintivas de es la hospitalidad y calidez de su gente, quienes reciben a los visitantes con los brazos abiertos. Como visitante, tenés la oportunidad de hospedarte en pascanas para descansar y compartir comidas con los residentes, creando conexiones auténticas y significativas que trascienden las barreras culturales. La Comunidad Nuevo Surutú, ubicada dentro del parque Amboró, está rodeada de una naturaleza exuberante y biodiversidad que ofrece variedad de oportunidades para el ecoturismo y la aventura al aire libre.

ph: AENS

IGLESIA DE LA SANTÍSIMA TRINIDAD

Ubicación: Km 37, Localidad de Limoncito, El Torno.

ph: Marshal

En la localidad de Limoncito, situada a 37 kilómetros del municipio de Santa Cruz de la Sierra, se encuentra la Iglesia de la Santísima Trinidad. Según cuentan los residentes, esta capilla es un testimonio de la bondad de Dios hacia ellos. La historia de su construcción comienza cuando el estadounidense Benno Etmuller llega a Limoncito y comparte con sus conocidos que ha recibido una revelación divina: debía construir una capilla. Aunque en un principio pensaba erigirla en la provincia de Cordillera, los habitantes locales lo convencieron de construirla en Limoncito. La construcción del templo no fue sencilla. El Sr. Etmuller inicialmente deseaba construir la capilla en una zona elevada, lo que requería encontrar un terreno adecuado en las alturas. Sin embargo, la generosidad de los residentes Nicolás Leaños y la señora Pinto hizo posible que el sueño se hiciera realidad, ya que ellos donaron el terreno. A pesar de esto, la construcción enfrentó más desafíos: Coordecruz solo pudo proporcionar un tractor durante dos horas. No obstante, gracias a sus contactos, Benno Etmuller consiguió 30 horas adicionales de uso del tractor, siempre y cuando los residentes proporcionaran el diésel necesario. A pesar de las adversidades, la construcción de la Iglesia se completó y abrió sus puertas el 14 de junio de 1987. Hoy en día es un símbolo de fe y esperanza para la comunidad de Limoncito.

FERIA DEL CÍTRICO

EN EL TORNO

Ubicación: Km 34, Plaza principal de El Torno.

ph: GAD SCZ

La Feria del Cítrico de El Torno se ha consolidado a lo largo de aproximadamente 20 ediciones como un evento destacado que celebra el potencial productivo del municipio. Este festival es conocido por su atractivo principal: una impresionante variedad de frutas cítricas, entre ellas naranjas, pomelos, mandarinas y quinotos, todas cargadas de vitamina C. En cada edición, la feria reúne a hasta 130 productores que presentan una amplia gama de productos cítricos, desde frutas frescas hasta sus derivados más creativos. Además, la feria ofrece una rica oferta de artesanías elaboradas por productores locales de El Torno, quienes utilizan materiales autóctonos de la región cruceña para sus creaciones. La Gobernación juega un papel crucial en este evento al proporcionar asistencia técnica, capacitaciones y semillas para apoyar a los pequeños y medianos productores locales. Así, la feria se convierte no solo en una oportunidad para exhibir y vender cítricos a precios accesibles, sino también en una plataforma que promueve la economía local y la tradición regional.

ph: GAD SCZ

TAPEKUA LE MAYEN

Ubicación: Km 37, a diagonal izquierdo carretera a Cochabamba
Atención: Viernes a domingo: De 11:30 a 17:30 Hrs.

ph: Tapekua Le Mayen

Este restaurante, conocido por su exquisita cocina internacional, se encuentra ubicado a 37 kilómetros de Santa Cruz de la Sierra y es un destino gastronómico imperdible para los visitantes que desean explorar la rica cultura culinaria suiza fusionada con la experiencia tradicional de un día de campo. Su nombre, significa "la posada" en el idioma guaraní. Le Mayen, además, es un destino que cuenta con cabañas equipadas con todo lo necesario para una estadía cómoda.

La propiedad se extiende sobre 6 hectáreas, que están hermosamente conservadas con jardines y bosques bastos en árboles frutales; una vista ideal para que des largos paseos y descansés de la agitada ciudad. También cuenta con espacios para eventos como bodas o cumpleaños, además que de lunes a viernes, el establecimiento ofrece a sus visitantes el servicio alimenticio.. Este es un destino infaltable si querés disfrutar unos días de descanso y reposo, o simplemente quieras aventurarte a probar delicias gastronómicas que Le Mayen, tiene para vos.

ph: Tapekua Le Mayen

ph: Tapekua Le Mayen

RESORT Y FAMILY CLUB

HELEDEM

Ubicación: Km 43, Comunidad Jorochito El Torno
Atención: Siempre abierto

ph: Heledem

Heledem Resort & Family Club se encuentra ubicado en la comunidad de Jorochito, dentro del municipio de El Torno. Este resort es, sin lugar a dudas, un lugar increíble para vacacionar o aprovechar los fines de semana, feriados o tiempos libres con tus seres queridos. Ofrece a sus visitantes piscinas de diferentes tamaños, adaptadas para todas las edades, y toboganes para los más pequeños. Pensando en ellos, también encontrarás espacios verdes con parques adaptados para su diversión.Este encantador lugar te brinda la oportunidad de realizar deportes extremos dentro de sus espacios, como rutas de trekking, recorridos en cuadratracks y rappel en descenso. Además, cuenta con un restaurante (Los Lirios) que

ph: Heledem

ph: Heledem

ofrece servicios de alimentación durante tu estadía. Este complejo turístico está dividido en tres tipos de rutas: ruta vehicular, ruta peatonal y ruta de trekking. Con espacios para que podás hospedarte, como una variedad de cabañas, áreas de camping que tienen sanitarios para los huéspedes, Heledem te brindará una experiencia maravillosa, lejos del bullicio de la ciudad, conectándote con la naturaleza a través de sus espacios recreativos, deportivos y de descanso. ¡Un tesoro natural en el municipio de El Torno!

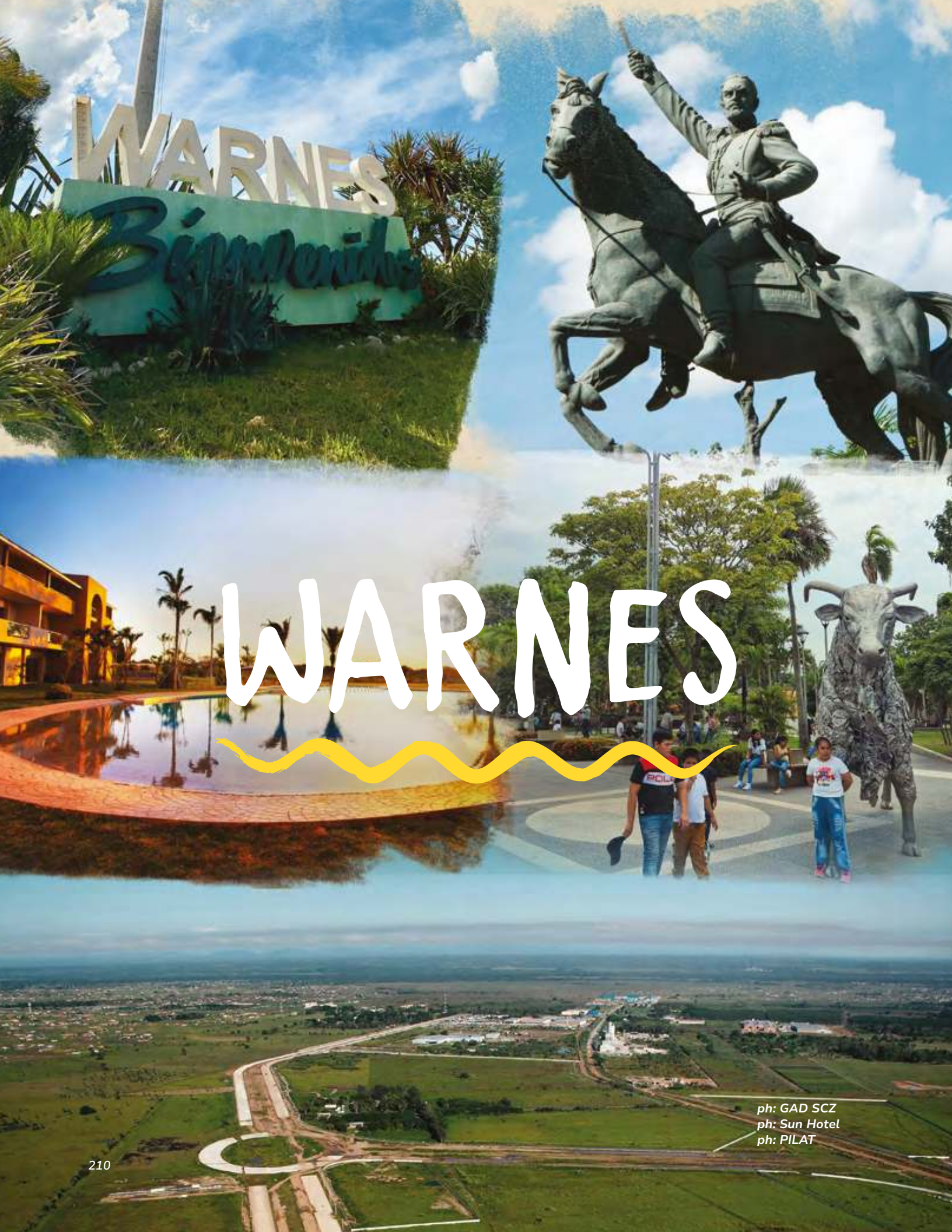

WARNES

ph: GAD SCZ
ph: Sun Hotel
ph: PILAT

WARNES

Provincia Ignacio Warnes
Fundación: Antiguo establecimiento agropecuario construido en 1790 con el nombre de La Rinconada de Chané, propiedad del sacerdote José Molina Campos. En 1891 la población toma el nombre definitivo de Warnes.

DATOS GENERALES

El Municipio de Warnes tiene una riqueza importante por su privilegiada ubicación en el corazón de la Región Metropolitana de Santa Cruz, que concentra prácticamente todo el desarrollo industrial del departamento. Tiene excepcionales condiciones de vinculación caminera, en especial la carretera de la red que une Warnes con Santa Cruz de la Sierra y la pujante zona del norte integrado, además del ramal de la red fundamental que une Montero y todo el norte cruceño con la carretera al Beni y el corredor bioceánico.

El aeropuerto internacional Viru Viru se constituye en una de las potencialidades más importantes del territorio, que permite la rápida vinculación con el interior y exterior del país.

CLIMA

Tropical húmedo – seco. El periodo más lluvioso se da en los meses de enero a marzo, por otro lado, la precipitación más baja se presenta durante el invierno (junio, julio y agosto). Los veranos son largos, cálidos y mayormente soleados; los inviernos son cortos, cómodos, húmedos y parcialmente nublados.

Temperatura promedio: la temperatura generalmente varía en un promedio de 13,8 °C a 36,9 °C.

DATOS GEOGRÁFICOS

Ubicación: 27 kilómetros al norte de la ciudad de Santa Cruz de la Sierra

Coordenadas: 17°30'37"S 63°09'53"O

Superficie: 1.800 Km²

Altitud : 340 m.s.n.m.

DATOS DEMOGRÁFICOS

Gentilicio: Warneño (a)
Población (2023)[1]: 190.298 habitantes
Densidad (2023): 106 hab./km²

ECONOMÍA

Economía[2]: Las actividades económicas más importantes son manufactura y el agrícola, que de acuerdo con el Valor Bruto de Producción (VBP) del municipio representan el 49.61% y 40.48% respectivamente.

[3]Por las características climáticas, en el municipio de Warnes la actividad agrícola está orientada hacia la producción agroindustrial, donde el principal producto cultivado es la caña de azúcar, pues representa el 71,3% (30.849 ha) del total de la superficie agrícola cultivada. El segundo producto representativo en el municipio es la Soya con una superficie de 4.707 ha que representa el 10,9%, seguida por el Sorgo 5% (2.175 ha.), Maíz 1,7% (737) y Grano de Girasol 1,6 % (704 ha).

Valor Bruto de Producción (VBP)[4]: 2.231 MM Bs

---

[1] Encuesta de Estimación Poblacional de Santa Cruz 2023. Instituto Cruceño de Estadística
[2] Mapa de Complejidades, BDP 2019
[3] PTDI del Municipio de Warnes 2015 – 2019
[4] Mapa de Complejidades, BDP 2019

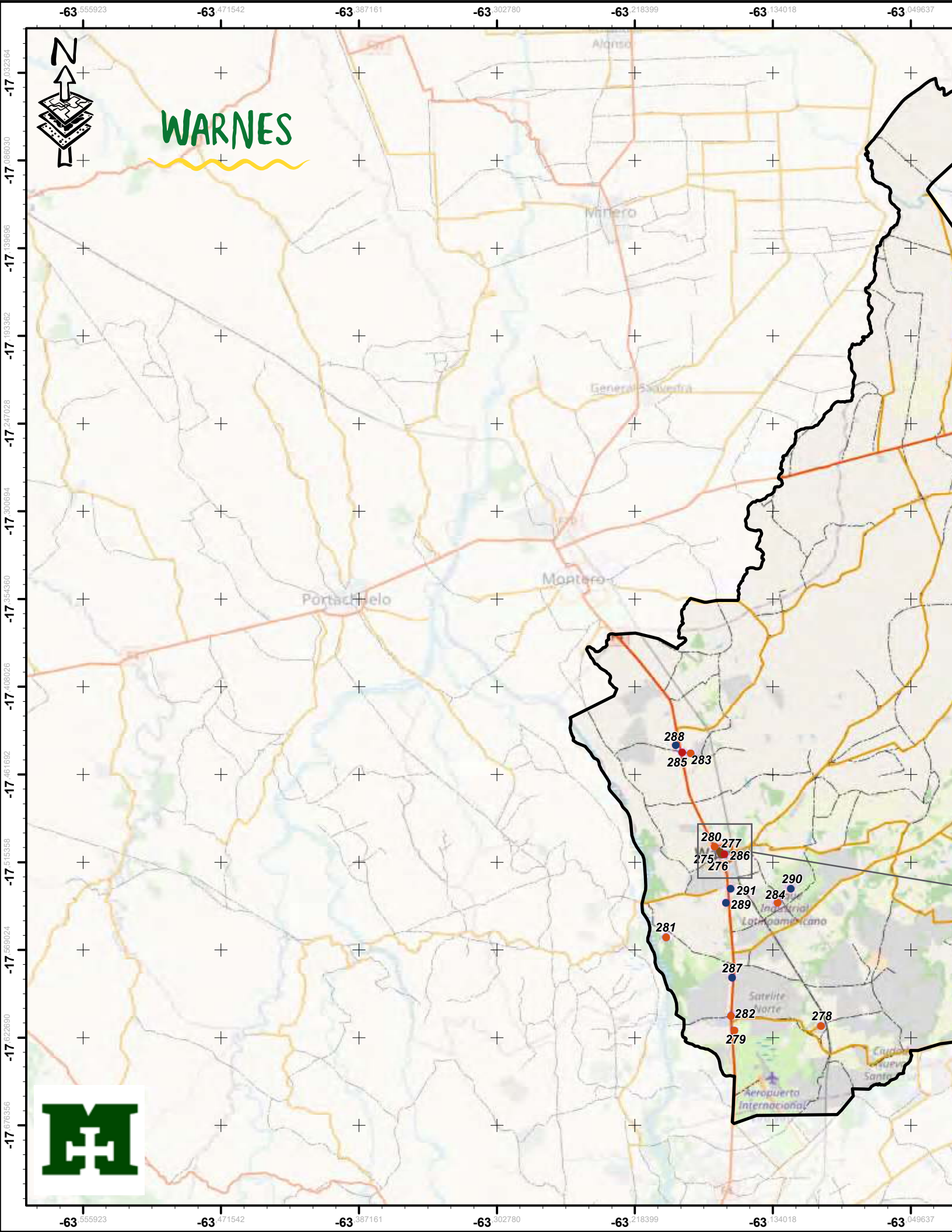
WARNES
N
-63.555923
-63.471542
-63.387161
-63.302780
-63.218399
-63.134018
-63.049637
-17.032364
-17.086030
-17.139696
-17.193362
-17.247028
-17.300694
-17.354360
-17.408026
-17.461692
-17.515358
-17.569024
-17.622690
-17.676356
Alonso
Minero
General Saavedra
Montero
Portachuelo
288
285
283
280
277
275
286
276
290
291
284
289
281
287
282
278
279
Industrial Latinoamericano
Satelite Norte
Aeropuerto Internacional

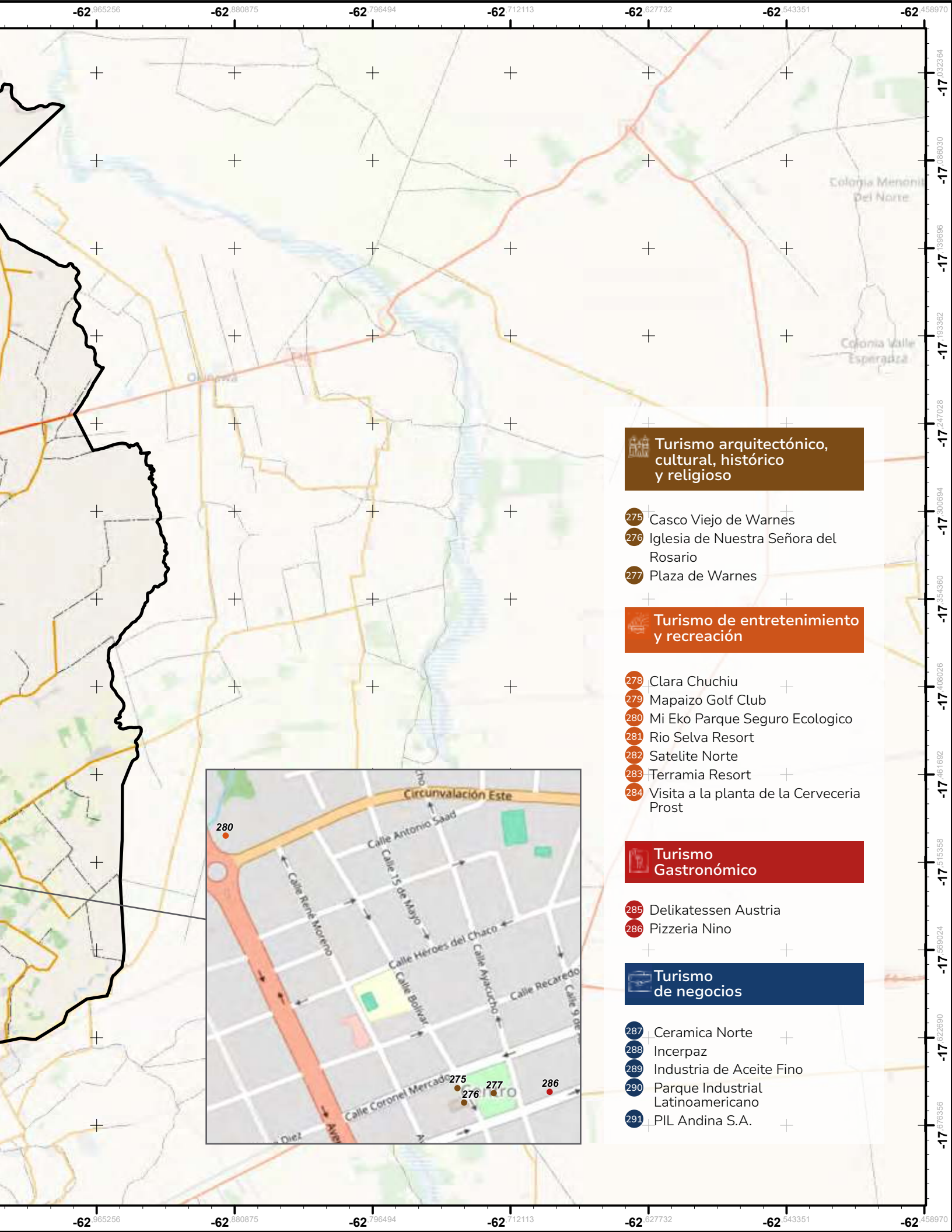

Turismo arquitectónico, cultural, histórico y religioso

- 275 Casco Viejo de Warnes
- 276 Iglesia de Nuestra Señora del Rosario
- 277 Plaza de Warnes

Turismo de entretenimiento y recreación

- 278 Clara Chuchiu
- 279 Mapaizo Golf Club
- 280 Mi Eko Parque Seguro Ecologico
- 281 Rio Selva Resort
- 282 Satelite Norte
- 283 Terramia Resort
- 284 Visita a la planta de la Cerveceria Prost

Turismo Gastronómico

- 285 Delikatessen Austria
- 286 Pizzeria Nino

Turismo de negocios

- 287 Ceramica Norte
- 288 Incerpaz
- 289 Industria de Aceite Fino
- 290 Parque Industrial Latinoamericano
- 291 PIL Andina S.A.

CASCO VIEJO

DE WARNES

Ubicación: Perímetro contemplado dentro del primer anillo, desde el kilómetro cero hasta Av 25 de mayo, esquina Monseñor Rivero y Bolivar.

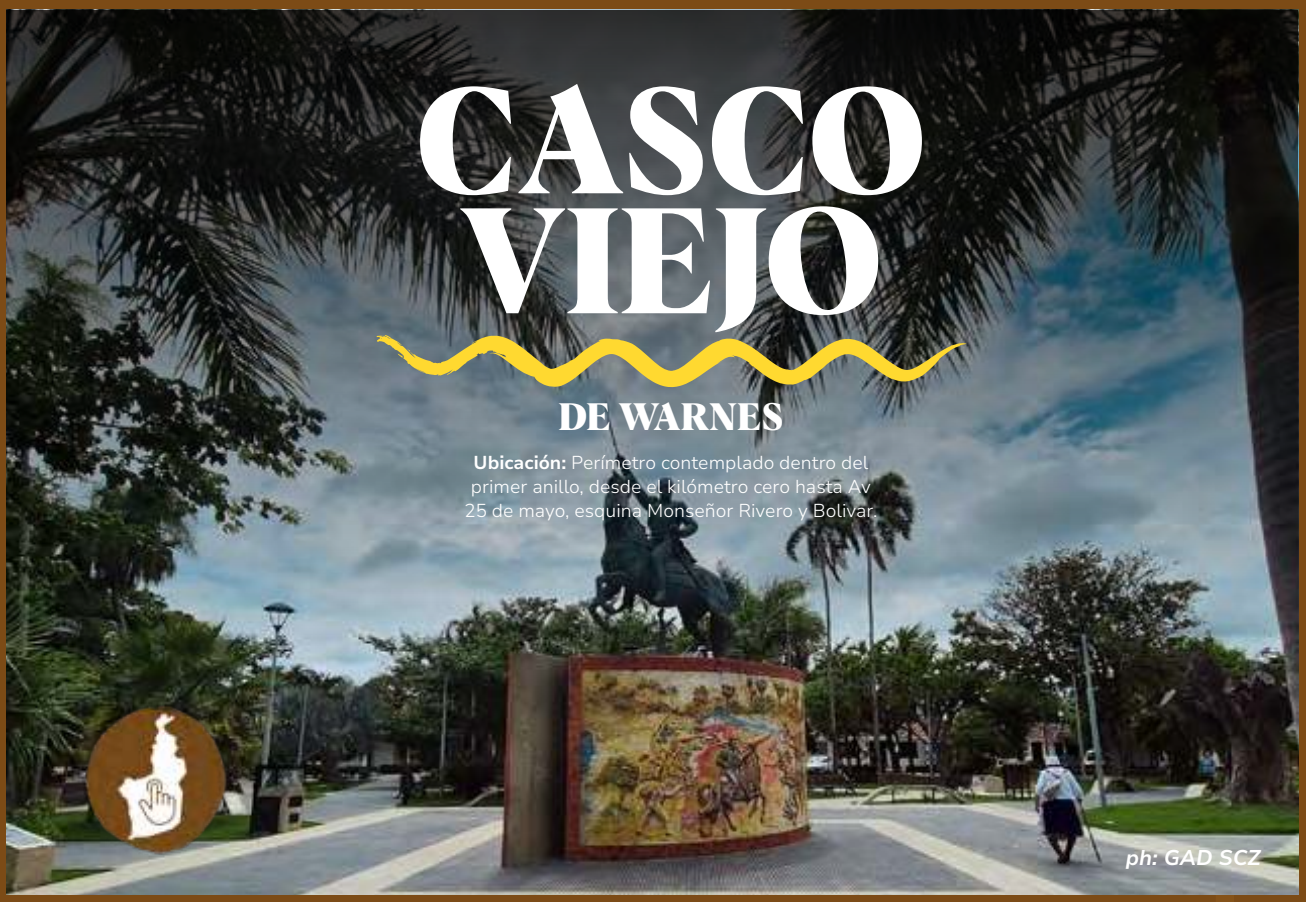

ph: GAD SCZ

Ubicado a 31 kilómetros de la capital cruceña, su origen se remonta a 1760, cuando el capellán José Molina Campos estableció una próspera comunidad agrícola en la región, erigiendo un oratorio que fungió como punto de encuentro para los habitantes circundantes. De este florecimiento inicial surgió un pueblo que, bajo diferentes denominaciones como "La Rinconada del Chané" y posteriormente "Chané" y "La Enconada", finalmente adoptaría el nombre de Warnes en 1891, en honor al influyente caudillo de la independencia. En el corazón de Warnes, se erige la majestuosa Iglesia construida en 1859, la cual ha sido un faro de devoción para la comunidad, rindiendo homenaje a la Virgen del Rosario cada primer domingo de octubre. Explorar el casco viejo de Warnes es sumergirse en un viaje a través de la tradición y la historia del norte cruceño, donde cada calle y casa cuenta una historia de resistencia y resiliencia cultural. En el casco viejo, podrás disfrutar de una variedad de comidas tradicionales. Desde las 5 de la tarde, encontrarás por las calles, a las mujeres de antaño vendiendo el tradicional pan de arroz junto a su delicioso vaso de mocochinchi. De igual forma, sobre la carretera Norte, encontrarás acceso a todos los servicios que un turista necesita, desde cajeros automáticos, bancos y transporte privado, que te permitirá desplazarte a la capital y a los municipios cercanos. ¡Conocé el patrimonio de Warnes!

ph: GAD SCZ

IGLESIA

NUESTRA SEÑORA DEL ROSARIO

Ubicación: Calle Bolivar, frente a plaza prinicpal 24 de septiembre Warnes
Atención: Lunes: 19:30 Hrs. Martes, Viernes y Sábado: 07:00 a 19:30 Hrs. Miércoles: 19:00 Hrs. Jueves: 19:00 Hrs. Domingos: 08:00 - 09:30 y 18:00 y 19:30 Hrs.

ph: GAD SCZ

En sus humildes inicios, la iglesia era simplemente un modesto oratorio, con un techo de tejas y un amplio corredor que se extendía hacia la calle, ubicada en lo que hoy ocupa la acera sur de la casa principal, ahora convertida en el Club de Leones. El diseño original estaba conformado por una estructura central de al menos 20 metros de largo y 10 de ancho. Este lugar de devoción, originalmente designado como viceparroquia, fue dedicado a Nuestra Señora del Rosario desde su edificación en 1760. Como se ha mencionado, cada primer domingo de octubre, la comunidad se reúne para rendir homenaje y celebrar la festividad patronal del pueblo. La viceparroquia fue elevada al rango de parroquia en 1840, mediante un Auto Episcopal. La transformación más significativa del templo tuvo lugar en 1950, bajo la dirección de Gil Antonio Pérez Franco, y nuevamente en 1989, durante el mandato del alcalde Alfredo Vaca Díez. Durante estas renovaciones, se realizaron modificaciones en el interior del templo, incluida la sustitución de las columnas por otras de estilo de las misiones chiquitanas. La torre moderna que ahora se erige majestuosa en el horizonte fue construida en 1900 por arquitectos españoles. Las campanas, son un regalo generoso de una residente conocida como “la reina” y posteriormente, fueron renovadas para convertirse en campanas automáticas en el año 2000, gracias a una donación de la alcaldía. Hoy en día, la iglesia es cuidada y atendida por los sacerdotes de la comunidad Oblatos de San José, manteniendo viva la llama de la fe y la devoción en el corazón de la comunidad de Warnes.

ph: GAD SCZ

PLAZA

DE WARNES

Ubicación: Perimetro contemplado entre esquinas Boliva, Coronel Mercado, Sucre y Monseñor Rivero

ph: Distribuidora Clarita

Galardonada como la plaza principal más moderna del norte integrado, ofrece un ambiente de disfrute para los visitantes y residentes, prometiendo una seguridad integral y un paisajismo de primera categoria. La plaza principal de Warnes, ubicada a 31 kilómetros de la capital cruceña y contemplada desde un enfoque ingenieril, es un escenario moderno e innovador en el departamento de Santa Cruz. Cuenta con un sistema de alcantarillado debajo del manzano en el que se encuentra, buscando evitar la acumulación de agua en tiempos de lluvia, además de un sistema de riego automático para la conservación del jardín. Tiene jardines en elevación para evitar que sus espacios verdes sean destruidos y posee una colección de 30 palmeras, que otorgan sombra natural a quienes la visitan. Además, cuenta con murales que conmemoran la batalla del Pari. En el costado izquierdo de la plaza, sobre la calle Coronel Mercado, encontrarás un restaurante donde se ofrecen diferentes platos de gastronomía internacional y warneña. La fachada de los restaurantes está revestida con pintura tradicional. La Plaza, tiene acceso a internet gratis en todo el perímetro, complementado con una red de vigilancia, para que puedas sentirte seguro.

ph: Distribuidora Clarita

VISITA LA PLANTA

PROST

Ubicación: Parque Industrial Latinoamericano, a 10 min a la derecha de Carretera al norte
Atención: Todos los viernes de 19:00 a 24:00 Hrs.

ph: Prost

La visita a la Cervecería Prost es sin duda, una experiencia muy divertida que podrás disfrutar con amigos, colegas o familiares. Consiste en un novedoso y entretenido recorrido, recorrido que incluye una visita guiada por las instalaciones, degustación de las cervezas directamente de los tanques de enfriamiento, y finaliza con un picoteo de carnes (de churrasco, por supuesto). Si venís al municipio de Warnes, no perdás la oportunidad de conocer la planta cervecera y pasar un viernes por la noche al estilo cruceño, cargado de alegría y diversión acompañado de sus buenas frías.

ph: Prost

ph: Prost

MI EKOPARQUE

PARQUE ECOLÓGICO DE WARNES

Ubicación: Km 33, Av. 25 de Mayo, municipio de Warnes.

El Parque Ecológico Warnes, también conocido como Ekoparque Ecológico, es un espacio al aire libre en el que podrás disfrutar en familia, pareja o con amigos. Aquí, tanto familias como jóvenes y niños pueden realizar múltiples actividades, ya que cuenta con estructuras diseñadas para estimular la imaginación y compartir momentos especiales. Desde áreas de juegos con columpios y toboganes hasta espacios recreativos y deportivos. Cuenta con servicio de internet gratuito. El área social para las familias cuenta con 16 churrasqueras y se complementa con un área de servicios básicos gratuito; la última área tiene un teatro al aire libre y espacios para el desarrollo de actividades culturales y mesas de ajedrez.

MAPAIZO GOLF CLUB

Ubicación: Km 20, carretera al Norte
Atención: Martes a domingos de 7:00 a 19:00 Hrs.

Un destino imprescindible para los amantes del golf. Este club, con su impresionante diseño y paisaje pintoresco, ofrece una experiencia de juego excepcional. El club de golf ofrece dos tipos de membresías, la primera denominada “solo” es exclusiva para jugadores menores de 39 años. Por Bs. 500 mensuales, brindando acceso ilimitado al campo y al driving range. Este plan es ideal para golfistas jóvenes que desean practicar y disfrutar del golf regularmente. La membresía es individual y de uso exclusivo de campos. El segundo tipo de membresía ofrece una cartera de beneficios más amplia. Los miembros tienen derecho al uso de todas las instalaciones, junto a un dependiente que el asociado elija, por un costo de Bs 990 mensual, además de los mismos accesos en los campos de juego.

BARRIO CASA DE LAS

BOTELLAS

Ubicación: Dentro de localidad “Satelite Norte”

El Barrio Casa de las Botellas fue creado por la cruceña Ingrid Vaca Diez, quien concibió la idea de construir viviendas utilizando botellas de plástico recicladas como material principal. El proyecto surgió como una respuesta creativa a la necesidad de viviendas económicas y sostenibles para las personas en extrema pobreza, al mismo tiempo que abordó el problema de la contaminación por plásticos. Estas botellas se utilizan como ladrillos para levantar paredes, luego se cubren con una mezcla de cemento y otros materiales para dar estabilidad y resistencia estructural.

SATÉLITE NORTE

Ubicación: Km 20, diagonal derecho carretera a norte

Es una ciudadela con el segundo mayor crecimiento poblacional del municipio. Satélite Norte, es un rincón en Santa Cruz que reúne una pequeña fracción de cada una de las regiones del país, ya que alberga una enorme variedad de migrantes nacionales. En este espacio, encontrarás una variada oferta gastronómica. Además, existe un movimiento comercial bastante fuerte, por lo que aquí encontrarás una variedad de productos y servicios para el diario vivir.

CLARA CHUCHIO

Ubicación: Km 25, sobre carretera Bioceanica

Clara Chuchio es un punto de descanso para quienes practican ciclismo en la zona norte de la metrópoli cruceña. Aquí podrás relajarte, divertirte y pasear por la comunidad. También podrás ser parte de la experiencia que ofrece la celebración de la fiesta patronal de la Virgen del Carmen, que se realiza el 17 y 18 de julio de cada año. Esta celebración es amenizada con danzas tradicionales y platos típicos del departamento, además de otras actividades para rendir devoción a su Santa Patrona.

TERRAMIA RESORT

COMPLEJO TURÍSTICO

Ubicación: RN4, por ingreso a las Barreras
Atención: Abierto 24 Hrs.

ph: Terramia Resort

Galardonado con cuatro estrellas y considerado como el complejo turistico más completo del municipio, te presentamos a Terramia Resort, el lugar perfecto para que olvidés el estrés diario y reconectés con la naturaleza. Ubicado a tan solo 40 kilómetros de la capital cruceña, este complejo hotelero, tiene todos los lujos y comodidades para ofrecerte, donde podrás disfrutar de múltiples espacios de relajación priorizando tu bienestar y comodidad. Terramia Resort te ofrece diferentes tipos de actividades, ya que cuenta con una variedad de piscinas con toboganes, servicio de spa y saunas. Si sos amante de los deportes, tendrás acceso a múltiples espacios recreativos como canchas de fútbol, vóley de arena, baloncesto y futsal, además podrás realizar paseos en kayak y manejar barquitos a pedal en su hermosísima laguna natural, mientras disfrutás de vistas increíbles de la flora que caracteriza la zona. Tendrás la oportunidad de degustar una variedad de platos, ya que Terramia Resort ofrece servicios de buffet y platos típicos nacionales para todos los gustos, en los horarios de desayuno, almuerzo y cena. Salas de cine, karaoke y una escenografía natural llamada Oasis, también distinguen a Terramia como un destino imperdible si visitás el municipio de Warnes.

ph: Terramia Resort

ph: Terramia Resort

ph: Santa Cruz Top Hotels

Rodeado por 10 hectáreas de jardines, Río Selva Resort ofrece una experiencia única en armonía con la naturaleza. Brinda a sus huéspedes una interesante variedad en sus instalaciones que fusionan la calidéz de la arquitectura rústica con comodidades modernas, incluyendo cabañas, estudios y suites. Sus amplias áreas sociales garantizan entretenimiento y la relajación a quienes se hospedan en este magnífico lugar, con una infraestructura completa para vacaciones, eventos o reuniones de grupos ejecutivos. El Resort, tiene la capacidad para albergar hasta 380 personas para el plan familiar y 235 en seminarios. Ofrece privacidad y confort en todos sus ambientes, que están equipados con baño privado, aire acondicionado, frigobar, telefonía nacional e internacional, y TV por cable.

ph: Hotel Sun

Ubicado a 2 Km del Aeropuerto Internacional Viru Viru, Sun Hotel combina calidéz y comodidad en sus instalaciones. Además de contar con una ubicación estratégica, ofrece espacios recreativos como una gran piscina en el centro de sus habitaciones, un gimnasio equipado y un spa que cuenta con sauna seco, húmedo e hidromasaje. Si lo que buscás es un hotel que ofrezca espacios para el desarrollo de ruedas de negocios o reuniones ejecutivas, Sun Hotel dispone de un salón de eventos con capacidad para 250 personas, equipado con sillas y proyectores. Además, ofrece traslado gratuito desde el aeropuerto hasta las instalaciones para los grupos ejecutivos. El hotel ofrece diversos paquetes para sus huéspedes, como "Day One" para aquellos pasajeros que necesitan hospedarse por escala, "Noches Románticas" para parejas, "Noche de Bodas" para recién casados y el "Paquete Relax". Sun Hotel también cuenta con acceso a internet en todo momento, desayuno incluido en todas las tarifas, estacionamiento gratuito y es pet friendly.

Pizzeria Restaurante NINO, especializado en la elaboración de pizzas artesanales. Ofrece una extensa variedad de pizzas para muchos gustos y cuenta con los tamaños medio y grande, para que podás visitarla con toda la familia y de las deliciosas pizzas, ofrece durante la semana diferentes tipos de menú, con una oferta de carnes y pastas, además de ciertos platos tradicionales que son típicos de la región. Se realizan celebraciones de eventos, tocadas en vivo, festejos cumpleañeros para todas las edades.

Delikatessen Austria es un restaurante que se encuentra ubicado a tan solo 38 kilómetros de la capital cruceña. Este lugar te ofrece una auténtica experiencia de un día de campo combinada con la riqueza y variedad de la tradición austriaca. Se especializa en una amplia variedad de platos típicos austriacos, entre los cuales destacan la costilla de cerdo, cordón blue, gulasch, wiener schnitzel y salchicha Liona. Además, podrás deleitarte con exquisitos postres alemanes y una selección de cafés. El lugar no solo ofrece una experiencia culinaria, sino también una serie de actividades recreativas que incluyen paseos en carroza y paseos a caballo. También, podrás celebrar tu cumpleaños en un ambiente único y especial, incluyendo la presencia de tus mascotas, ya que este restaurante tiene la categoria pet frendly. Delikatessen Austria es el destino ideal para quienes buscan disfrutar de la cultura y gastronomía austriaca en un entorno campestre y acogedor, apto para toda la familia y amigos.

PARQUE INDUSTRIAL LATINOAMERICANO

Ubicación: Km 32, sobre carretera norte, camino a Candelaria

ph: PILAT

El Parque Industrial Latinoamericano con una extensión de 1.800 hectáreas y una inversión inicial de 180 millones de dólares, se encuentra ubicado a 32 kilómetros de la capital del departamento. Este impresionante complejo alberga más de 1,500 industrias de diferentes escalas: pequeñas, medianas y grandes, es reconocido como el mayor "clúster" industrial de América Latina y el sexto parque industrial más grande del mundo, un motor económico de gran envergadura. Desde la producción automotriz hasta la manufactura de productos electrónicos, este parque alberga una amplia gama de industrias que impulsan el crecimiento económico en la región y ofrece una red de colaboración empresarial invaluable. Aquí, las empresas tienen la oportunidad de conectarse con otros actores del sector, compartir conocimientos y experiencias, y establecer alianzas estratégicas que impulsen su crecimiento. Los espacios de coworking, las incubadoras de negocios y los eventos de networking son solo algunas de las herramientas disponibles para fomentar la colaboración y el intercambio de ideas entre emprendedores y empresarios. A través de programas de apoyo a la innovación y el desarrollo tecnológico, las empresas pueden acceder a financiamiento, asesoramiento técnico y recursos especializados para llevar sus ideas al mercado. Además, la proximidad a universidades, centros de investigación y organismos gubernamentales fomenta la transferencia de conocimientos y la creación de sinergias que impulsan la innovación y el progreso tecnológico en la región. ¡Conocé el Parque Industrial Latinoamericano, el más grande del país!

ph: PILAT

ph: PILAT

ph: PILAT

Aceite Fino es una empresa agroindustrial y de consumo masivo líder en Bolivia, fundada en febrero de 1944. En 1974, trasladó su planta de extracción de aceite a Warnes, Santa Cruz, para estar más cerca de la materia prima. En 1982, amplió su planta de refinación en Cochabamba e instaló una planta de extracción por solventes en Santa Cruz. Ese mismo año, lanzó al mercado Manteca Karina, y en 1986, Margarina Regia. En 1995, desarrolló Manteca Gordito para el sector panadero, y en 1996, instaló una nueva planta de extracción con capacidad de 800 Tm/día, que se amplió en 2006 a 1.500 Tm/día. En 1999, FINO comenzó a exportar aceites envasados a países de la CAN. La empresa diversificó su cartera de productos, lanzando en 1998 el jabón de ropa OSO y en 2007 la marca UNO. La trayectoria de FINO nos muestra cómo el municipio de Warnes alberga empresas que son un motor de estabilidad y progreso, asegurando un futuro próspero para Santa Cruz y todos aquellos que quieran apostar por esta tierra.

Nace en 1960 como una planta industrializadora de leche con una capacidad productiva reducida, pero con la visión de crecimiento para posicionar al país. Esta fuerza traspasó fronteras, y fue así como durante 1996, logró expandirse hasta conseguir apoyo internacional, consolidándose en La Paz, Cochabamba, y sobre todo Santa Cruz. PIL fue testigo y cómplice del progreso de la tierra cruceña, así como parte fundamental de su desarrollo económico y social. Empresas como PIL contribuyen enormemente al crecimiento económico nacional, con inversiones y generación de empleo. La presencia de PIL aporta la estabilidad que Santa Cruz ofrece a quienes la visitan, convirtiéndose en un pilar de confianza y prosperidad para la región. Con su compromiso constante, PIL continúa impulsando diariamente el avance de Santa Cruz, consolidándose como uno de los referentes más importantes del desarrollo en el país.

INCERPAZ es una empresa proveedora de material cerámico de construcción, establecida y consolidada en Warnes, que a la fecha se constituye como una de las empresas con mayor extensión dentro del municipio. Inició sus operaciones el 1978 y, con el tiempo, se posicionó como una de las empresas líderes en cerámica industrial de la región de Latinoamérica. Su objetivo es brindar un servicio de calidad a través del sistema integrado de gestión en todos sus procesos. INCERPAZ ofrece al mercado una gran variedad de diseños y texturas de ladrillos; pero eso no es todo, ofrece también combos comerciales que fusionan la oferta del material de construcción con una variedad de elementos bastante útiles para el hogar, como kits de herramientas, sets churrasqueros, juegos de cubiertos, coolers, entre otros. Trabaja con materiales para construcción de muros, piezas especiales, pisos, pavimentos, revestimientos, elementos decorativos y techos, entre otros. Sin duda, es un ejemplo de la estabilidad industrial que ofrece el departamento.

Considerada una empresa líder en la producción y comercialización de material cerámico para la construcción, con una reputación de excelencia y confiabilidad en el mercado, te presentamos a CERÁMICA NORTE. Su casa matriz se encuentra ubicada en kilómetro 42 Carretera al Norte, una locación que funciona como núcleo de operaciones y refleja el compromiso con la innovación y la calidad. La empresa cuenta con 13 sucursales en todo el departamento, garantizando la calidad y disponibilidad de sus productos. CERÁMICA NORTE ofrece una amplia variedad de ladrillos, adaptándose a múltiples necesidades y tipos de construcción. Además, sus servicios incluyen una garantía de fábrica, asegurando la satisfacción y confianza de sus clientes.

OKINAWA I

ph: Colonia de Okinawa I
ph: Dwight Petar Mileta Albrecht
ph: Akex Arteaga

OKINAWA I

Provincia Ignacio Warnes
Fundación: En 1954, el presidente boliviano Víctor Paz Estenssoro permitió la migración de las familias japonesas que llegaron con unas 3.329 personas, en el marco de acuerdos con el convenio denominado Ryukyu, nombre del archipiélago después de la guerra. El asentamiento de los colonos de Okinawa en territorio boliviano, obedece a un Plan de migración del gobierno de "Ryukyu" (Actual Okinawa de Japón, que estaba ocupado por EE.UU., después de Segunda Guerra Mundial), que comenzó en el año 1954 y duró hasta el 1979. Inicialmente estuvo habitado por los migrantes, pero luego muchos bolivianos también llegaron para buscar trabajo, por lo que aumentó la población de la colonia. Consecuentemente en 1998, se estableció el municipio de Okinawa, como segunda sección municipal de la Provincia Warnes.

DATOS GENERALES

Conocida como la capital del trigo.

CLIMA

Los veranos son largos, cálidos, opresivos, mojados y mayormente nublados y los inviernos son cortos, cómodos, húmedos y parcialmente nublados. **Temperatura promedio:** Durante el transcurso del año, la temperatura generalmente varía de 16 °C a 32 °C y rara vez baja a menos de 10 °C o sube a más de 36 °C.

DATOS GEOGRÁFICOS

Ubicación: 146 kilómetros al noreste de la ciudad de Santa Cruz de la Sierra

Coordenadas: 17°20'00"S 62°50'00"O

Superficie: 1.113,78 Km²

Altitud : 257 m.s.n.m.

DATOS DEMOGRÁFICOS

Gentilicio: Okinawense
Población (2023): 14.068 habitantes
Densidad (2023): 13 hab./km²

ECONOMÍA

Economía: La actividad económica más importantes es la agrícola, que de acuerdo al Valor Bruto de Producción (VBP) del municipio representa el 93.5%.

En el Municipio Okinawa Uno, el área que comprende las tierras rurales (parcelas, propiedades, chacos) cuenta con grandes, medianas y pequeñas unidades productivas donde se practica el cultivo de trigo, soya, girasol, caña, frejol, sorgo, arroz y maíz. Estos dos últimos productos se cultivan en las parcelas pequeñas y los otros en las medianas y grandes. La mayoría de la producción se destina al mercado.Por otro lado, Identifica a las actividades que trasforman la producción agrícola y pecuaria como ser, arroz, girasol, caña de azúcar, trigo, soya, trigo, lácteos, incluso esta la actividad avícola. También se cuenta con otros centros de transformación como carpinterías y las esteras.

---

[1] Encuesta de Estimación Poblacional de Santa Cruz 2023. Instituto Cruceño de Estadística
[2] Mapa de Complejidades, BDP 2019

OKINAWA I

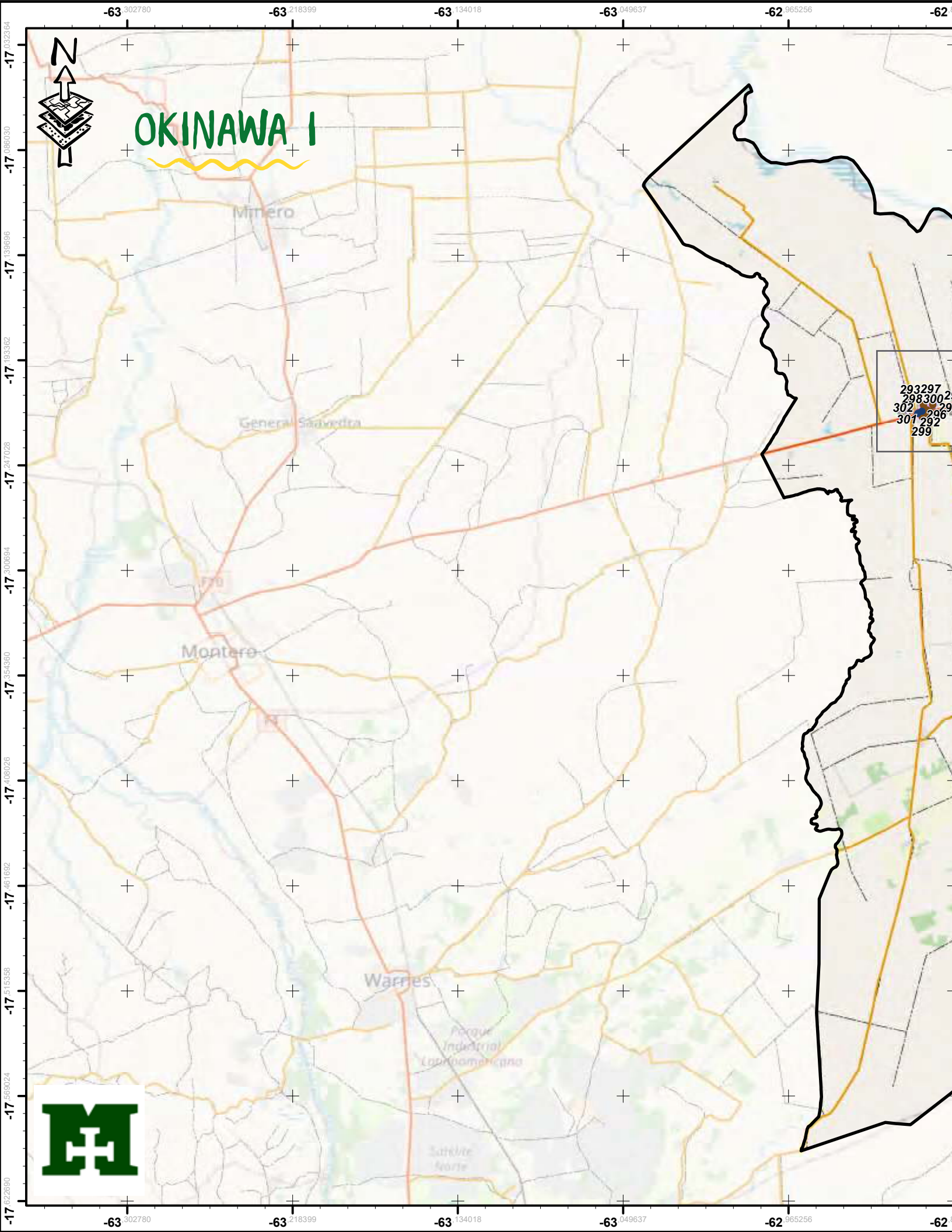
N
Minero
General Saavedra
Montero
Warnes
293297
298300
302
296
301
292
299
-63.302780
-63.218399
-63.134018
-63.049637
-62.965256
-17.032364
-17.086030
-17.139696
-17.193362
-17.247028
-17.300694
-17.354360
-17.408026
-17.461692
-17.515358
-17.569024
-17.622690

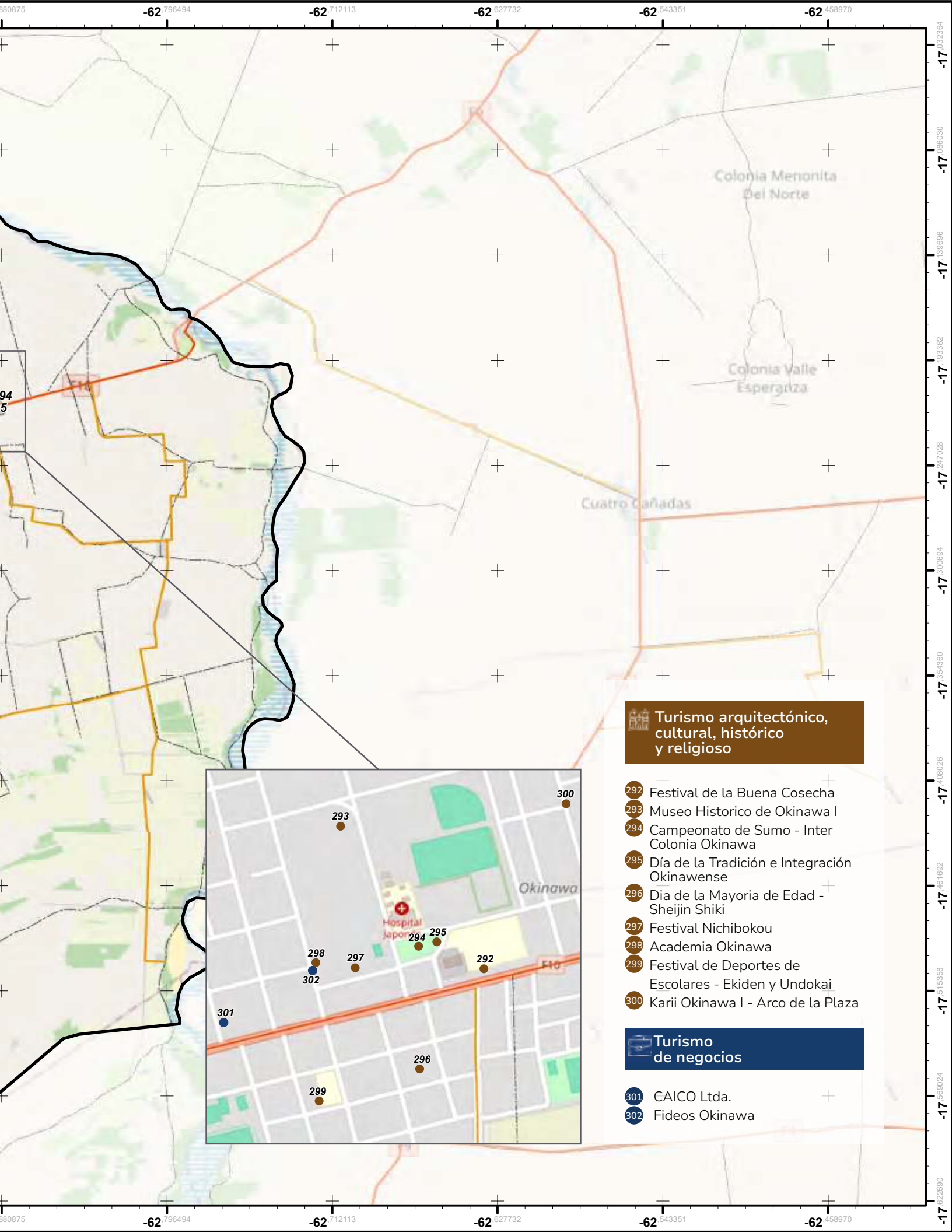

Turismo arquitectónico, cultural, histórico y religioso

- 292 Festival de la Buena Cosecha
- 293 Museo Historico de Okinawa I
- 294 Campeonato de Sumo - Inter Colonia Okinawa
- 295 Día de la Tradición e Integración Okinawense
- 296 Dia de la Mayoria de Edad - Sheijin Shiki
- 297 Festival Nichibokou
- 298 Academia Okinawa
- 299 Festival de Deportes de Escolares - Ekiden y Undokai
- 300 Karii Okinawa I - Arco de la Plaza

Turismo de negocios

- 301 CAICO Ltda.
- 302 Fideos Okinawa

FESTIVAL DE LA BUENA COSECHA

Ubicación: Av. 15 de Agosto, Plaza Principal
Atención: Desde las 07:00 Hrs.

Ph: Alexander Arteaga

ph: Alexander Arteaga

En honor a los campos dorados que se extienden hasta donde alcanza la vista y que son símbolo de prosperidad y desarrollo de esta localidad, te presentamos el Festival de la buena Cosecha. En el año 1908, se tiene registrada la llegada del primer okinawense, José Oshi, al país. Sin embargo, la migración de familias japonesas se detuvo debido a la posición de Bolivia como parte de los aliados en los conflictos bélicos de la segunda guerra mundial. Fue en 1954, a solicitud de los okinawenses de Riberalta y La Paz, que llegó a Santa Cruz el primer grupo de familias okinawenses, dotándolos alrededor de 50 hectáreas por familia. Esta festividad se celebra cada segunda semana de agosto, en conjunto con las colonias de Okinawa I, II y III. Las actividades inician un día antes, muy temprano, comenzando con la ceremonia de homenaje a los difuntos, en un mausoleo donde se encuentran escritos los nombres de sus ancestros en español y japonés. Al día siguiente, el festival abre en la mañana con una feria de maquinaria y equipos agrícolas en la plaza principal, con la participación de empresas e instituciones comerciales, industriales y productivas. Por la tarde, continúan las celebraciones del festival, con danzas tradicionales de la isla de Okinawa que se conservan en la colonia y una oferta gastronómica boliviano-okinawense, todo esto amenizado por las melodías de índole japonesa y oriental. Entre los espectáculos, mencionamos "La danza de la Buena Cosecha", integrada por mujeres en demostración de respeto, marcando el inicio de la fiesta. A continuación, varios grupos de niños con vestimentas tradicionales okinawenses.

ph: Alexander Arteaga

Se escuchan ritmos regionales como la chovena, taquirari, brincao y carnavalito. Finalmente, se lleva a cabo la Danza de Los Tambores, en la que niños y adolescentes usan el instrumento de percusión como símbolo del anuncio de la bienaventuranza, la hermandad y el triunfo de esta población.

ph: Alexander Arteaga

MUSEO HISTÓRICO

DE OKINAWA I

Ubicación: A cuatro cuadras al norte de la Av. 15 de Agosto
Atención: Martes a sabado 09:00 a 19:30 Hrs.
Domingo: 09:00 a 17:30 Hrs.

ph: Alexander Arteaga

La iniciativa para construir el Museo de la Inmigración surgió en 2001, en el aniversario número 47 de la llegada de las familias okinawenses a nuestro país. Preocupados por preservar la memoria de sus antepasados y el arduo trabajo que realizaron, varios inmigrantes impulsaron este proyecto. Por ello se formó un Comité Preparativo para el Festejo de las Colonias Okinawa, liderado por Sr. Hiroshi Kochi como presidente del Comité Organizador y el Sr. Yukifumi Nakamura como presidente ejecutivo. Dentro de este comité, se organizó específicamente el proyecto del museo, dirigido por el Sr. Tsugio Higa hasta su conclusión. La construcción del museo comenzó en 2002 y se completó a finales de 2003. Fue inaugurado el 15 de agosto de 2004, conmemorando los 50 años de la inmigración a las colonias de Okinawa. Este proyecto fue posible gracias a la cooperación económica de la Prefectura de Okinawa, Japón, y el apoyo técnico de numerosas instituciones. El museo exhibe utensilios, vestimentas, herramientas, fotografías que datan de la llegada de los primeros inmigrantes a la comunidad, además de artefactos que llegaron de la Segunda Guerra Mundial y que, ingeniosamente, fueron usados para la producción del trigo. Te encontrarás con múltiples fotografías que cuentan la historia de las primeras familias que llegaron a Santa Cruz, además de fotografías de las primeras siembras y cosechas de trigo en Okinawa. Todo un legado de historia y cultura viva, en el Museo Histórico de Okinawa I.

FERIA CULTURAL BUNKASAI

Ubicación: Centro Social Japonés

El Bunkasai es una feria cultural organizada por la Asociación Cultural Boliviana Japonesa (ACBJ) y tiene como objetivo principal promover y compartir la cultura japonesa con la comunidad local y el público en general. En japonés, “Bunkasai” significa “Festival

Cultural". Esta feria se inspira en los festivales culturales que son comunes en Japón, donde se exhiben diversas facetas de la cultura japonesa, como la comida, el arte, la música, la danza, el idioma, la moda, entre otros. Puede servir como una plataforma para fortalecer los lazos de amistad y cooperación entre ambos países a través del entendimiento mutuo y el aprecio por la diversidad cultural.

ACADEMIA DE ARTES MARCIALES
BUKEN

Ubicación: Plaza Principal, Avenida 15 de agosto, Okinawa I.
Atención: Sábado de 14:00 a 15:00 Hrs.

Esta academia transmite a los jóvenes y niños de la comunidad okinawense la tradición, los principios y las costumbres okinawenses. La práctica ancestral de artes marciales es una tradición que pasa de generación en generación, una disciplina que nace en la isla Okinawa (Japón) y que llega a Santa Cruz a través de sus descendientes. Los estudiantes de esta academia practican disciplinas como el karate y ninjutsu, entre otras. Cada año, la academia hace su debut en el Festival de la Buena Cosecha, resaltando la cultura del lugar y, de igual forma, honrando la llegada de sus antepasados a esta tierra. Es una forma de recordar todas las tradiciones que vinieron con ellos desde Japón.

ARTESANÍAS DE
ESTERAS

Ubicación: A 1 Km. de Plaza Principal de La Guardia

El municipio de Okinawa alberga un sinfín de expresiones culturales; sin embargo, esta actividad artesanal unifica la tradición japonesa con la materia prima que existe en el departamento. Desde la comunidad de San Miguel, situada al sur del municipio, las familias locales preservan una ancestral tradición: la elaboración de esteras. Utilizando habilidades transmitidas de generación en generación, transforman el junquillo, una planta local, en hermosas esteras de diferentes tamaños, desde dos plazas hasta individuales, siendo Warnes, Montero y Santa Cruz sus principales mercados. No te olvidés de llevarte una; son únicas en su tipo.

DÍA DE LA TRADICIÓN E INTEGRACIÓN

Ubicación: Plaza Principal, Avenida 15 de agosto, Okinawa I

El 5 de septiembre es el día de la tradición e integración okinawense, un jornada en la que podrás disfrutar de todo el legado cultural que ofrece esta cultura. Las actividades comienzan desde temprano, con una caravana que parte desde la empresa CAICO hasta la plaza principal del municipio de Okinawa I, donde se inaugura la festividad de la tradición. Posteriormente, se llevan a cabo elecciones de las reinas de Okinawa una muestra más de la mezcla cultural. En este día de la tradición, podrás encontrar una oferta gastronómica de alimentos a base de trigo, sorgo, miel, platos de origen japonés y oriental. Al atardecer, la festividad culminará con demostraciones de danzas típicas orientales y de ascendencia japonesa.

EKIDEN Y UNDOKAI

FESTIVAL DE DEPORTES ESCOLARES

Ubicación: Estadio municipal, Okinawa I

El Ekiden y el Undokai son eventos deportivos y culturales que forman parte de la celebración de la comunidad japonesa en el municipio de Okinawa I. El Ekiden es una carrera de relevos de larga distancia originaria de Japón, se organiza como una competencia deportiva que reúne a equipos de corredores de diferentes edades y habilidades. El Undokai es un torneo de atletismo deportivo y recreativo tradicional japonés, similar a un día de deportes o una jornada de campo. Tanto el Ekiden como el Undokai son eventos importantes dentro de la comunidad, mismos que se celebran en el mes de junio, ya que combinan la práctica deportiva con la celebración cultural y el fortalecimiento de las relaciones comunitarias,

FESTIVAL NICHIBOKOU

Ubicación: Av. 15 de Agosto, Plaza Principal

ph: U.E boliviano japonés, Okinawa I

Cada año, el municipio de Okinawa I se convierte en un vibrante escenario de cultura y tradición japonesa. Organizado por el Colegio boliviano-japones, este evento tiene como objetivo mostrar el legado enriquecido japonés que han mantenido los residentes de Okinawa I. La idea de este festival nació con los estudiantes de la promoción de 2022; ellos fueron quienes se inspiraron en un festival similar que se realiza en Japón con estudiantes de nivel secundario. El resultado fue una experiencia inolvidable que atrajo tanto a locales como a turistas.

ph: Alexander Arteaga

El festival ofrece una amplia gama de actividades para todas las edades. Aquí podrás disfrutar de juegos tradicionales japoneses y participar en un sushi tren, donde degustarás el sabor tradicional del sushi preparado por locales. Además, el festival incluye talleres de escritura japonesa y exhibiciones de origami, actividad recreativa si querés aprender y practicar estas antiguas tradiciones. La música tradicional japonesa resuena en el aire, acompañada de impresionantes juegos pirotécnicos que iluminan el cielo a la media noche. Los puestos de comida ofrecen una deliciosa variedad de platos típicos japoneses, para que podás experimentar los sabores tradicionales del municipio. Las demostraciones de artes marciales y danzas de origen japonés también forman parte del evento.

ph: CAICO

La historia de esta cooperativa se remonta a 1951, cuando los inmigrantes japoneses adquirieron tierras fiscales alrededor del río Grande y fundaron la Colonia Uruma (actualmente conocida como Okinawa I). En este contexto, establecieron la primera cooperativa bajo el nombre de Cooperativa Colonia Uruma. En 1957, se puso en funcionamiento un molino descascarador de arroz, lo que también marcó el inicio de la construcción de oficinas para la cooperativa. Entre 1960 y 1961, se crearon las colonias Okinawa II y Okinawa III, cada una con su propia cooperativa. En Okinawa II, se formó la Cooperativa Agrícola Nueva Esperanza, y en Okinawa III, la Cooperativa Agrícola Colonia Okinawa III. En 1965, las cooperativas independientes de las tres colonias se unieron para establecer la Asociación de Cooperativas Colonias Okinawa, con el objetivo de consolidar la venta de sus productos. En 1971, esta asociación se transformó en la Cooperativa Agropecuaria Integral Colonias Okinawa Limitada (CAICO LTDA), obteniendo su personería jurídica el 19 de agosto de ese año. Inicialmente, la cooperativa se dedicaba al cultivo de algodón, pero en 1981 se comenzó con el cultivo de soya, que pronto se convirtió en el principal producto de la región. En 1987, la prefectura de Okinawa en Japón aprobó un préstamo de 40,000 yenes para construir la Planta Agroindustrial CAINCO. Desde entonces y hasta 2002, la cooperativa diversificó sus producciones y abrió nuevos puntos de exportación. En 2002, el Ministerio de Agricultura, Ganadería y Desarrollo Rural de Bolivia, mediante la resolución ministerial N.º 131 del 30 de agosto de 2002, declaró a las Colonias Okinawa como la Capital Triguera de Bolivia, un reconocimiento que destaca su importancia en la producción de trigo en el país y un emblema de desarrollo para el departamento de Santa Cruz.

ph: CAICO



PAILÓN

ph: Nacional 13 de mayo
ph: Google
ph: GAD SCZ

PAILÓN

Provincia: Chiquitos
Fundación: No se encuentra bibliografía sobre el fundador de Pailón, sin embargo, se considera como fundadores a ganaderos cruceños, viajeros hacia Puerto Suárez y trabajadores del FF.CC (trabajadores y contratistas de la Comisión Mixta Ferroviaria Boliviano- Brasileña), que formaban los campamentos y viviendas del pueblo, de lo que iba a ser Pailón posteriormente, hasta el 13 de mayo de 1953, que es la fecha oficial de fundación.

DATOS GENERALES

Declarado "Patrimonio Cultural y Religioso de Bolivia" en el año 2003.
Huso horario: UTC-4
Moneda: Boliviano
Prefijo telefónico: +591 (3)

CLIMA

Clima: clima cálido subhúmedo, húmedo de verano e invierno cálido
Temperatura promedio: Se identifican dos periodos: el primero con bajas temperaturas que fluctúan entre los 21 a 24 °C registrados en entre los meses de abril a septiembre y el segundo periodo más caluroso que se distribuye entre los meses de octubre a marzo con temperaturas que fluctúan entre 26 a 27 °C de promedio

DATOS DEMOGRÁFICOS

Gentilicio: Pailoneño -a
Población (2023)[1]: 46.314 habitantes
Densidad (2023): 5 hab./Km²

DATOS GEOGRÁFICOS

Ubicación: 53,06 km al este de la ciudad de Santa Cruz de la Sierra

Coordenadas: 17°39'34"S 62°43'11"O

Superficie: 10.155 km²

Altitud : 291 m s.n.m.

ECONOMÍA

Economía[2]: Las actividades económicas más importantes son agrícola y pecuario que de acuerdo al Valor Bruto de Producción (VBP) del municipio representan el 85.22% y 12.47% respectivamente. [3]El municipio de Pailón, de acuerdo al ranking de producción agropecuaria-piscícola a nivel nacional, es el 2do productor en crianza de bovinos. Por otro lado, se destaca la producción de tipo agrícola como ser cultivos de: Soya, Maíz, Trigo, y en crianza de: aves de granja, porcinos de granja, ovinos.

Valor Bruto de Producción (VBP)[4]: 2.602 MM Bs.

---

[1] Encuesta de Estimación Poblacional de Santa Cruz 2023. Instituto Cruceño de Estadística
[2] Mapa de Complejidades, BDP 2019
[3] PTDI del Municipio de Pailón 2015 – 2019
[4] Mapa de Complejidades, BDP 2019

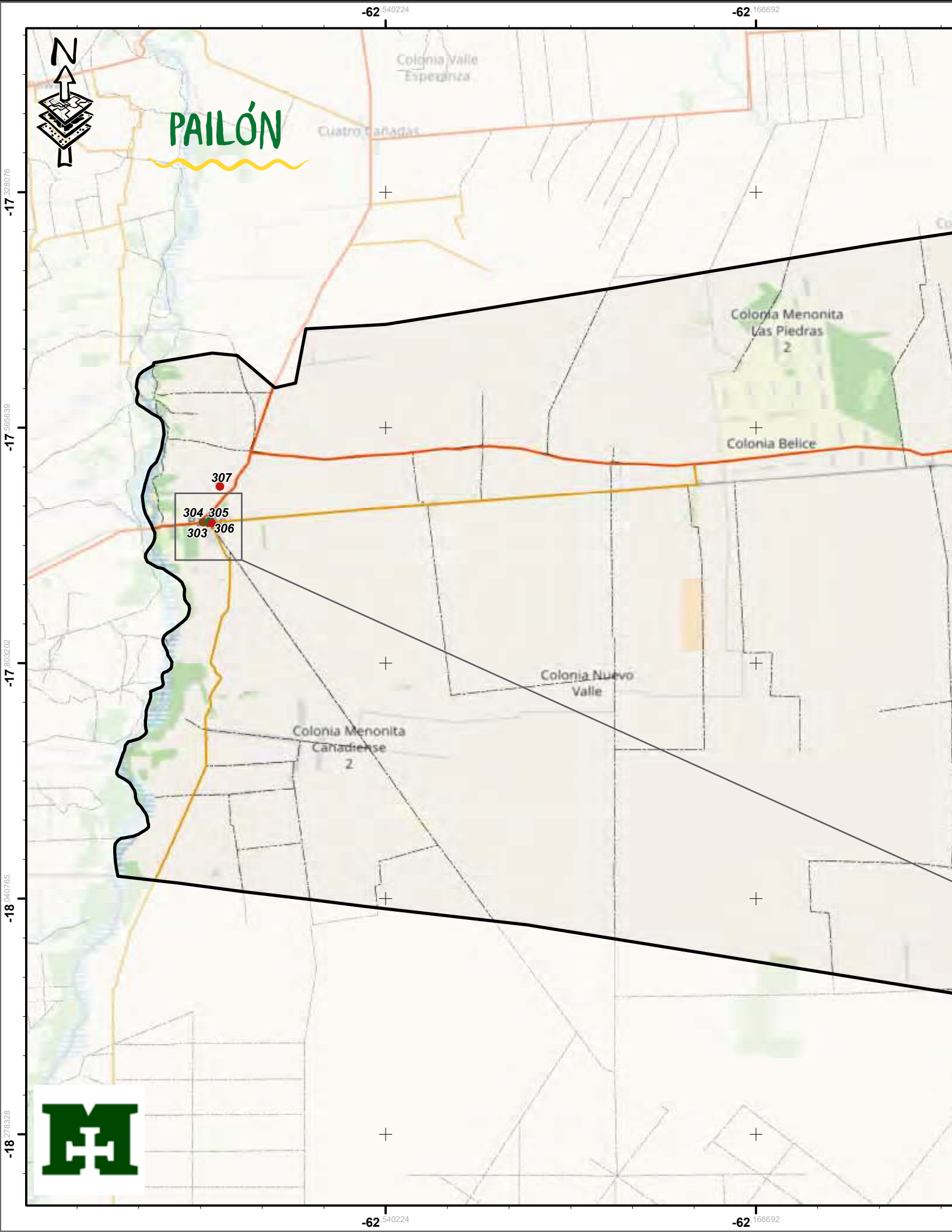
N
PAILÓN
Colonia Valle Esperanza
Cuatro Cañadas
Colonia Menonita Las Piedras 2
Colonia Belice
307
304
305
303
306
Colonia Nuevo Valle
Colonia Menonita Canadiense 2
-62.540224
-62.166692
-17.328076
-17.565639
-17.803202
-18.040765
-18.278328

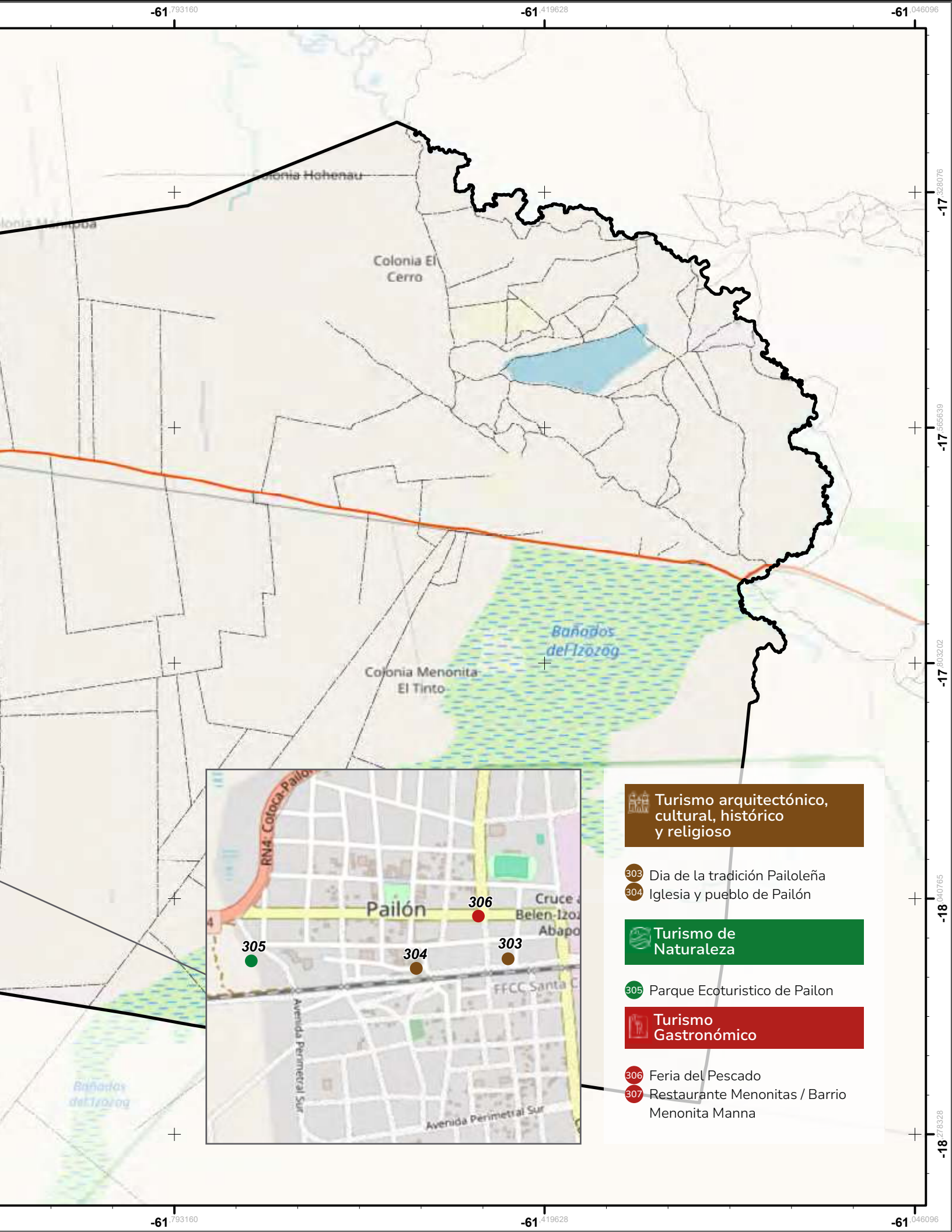
Colonia Hohenau
Colonia El Cerro
Bañados del Izozog
Colonia Menonita El Tinto
Pailón
RN4: Cotoca-Pailón
Avenida Perimetral Sur
FFCC Santa C
305
304
303
306
Turismo arquitectónico, cultural, histórico y religioso
303 Dia de la tradición Pailoleña
304 Iglesia y pueblo de Pailón
Turismo de Naturaleza
305 Parque Ecoturistico de Pailon
Turismo Gastronómico
306 Feria del Pescado
307 Restaurante Menonitas / Barrio Menonita Manna

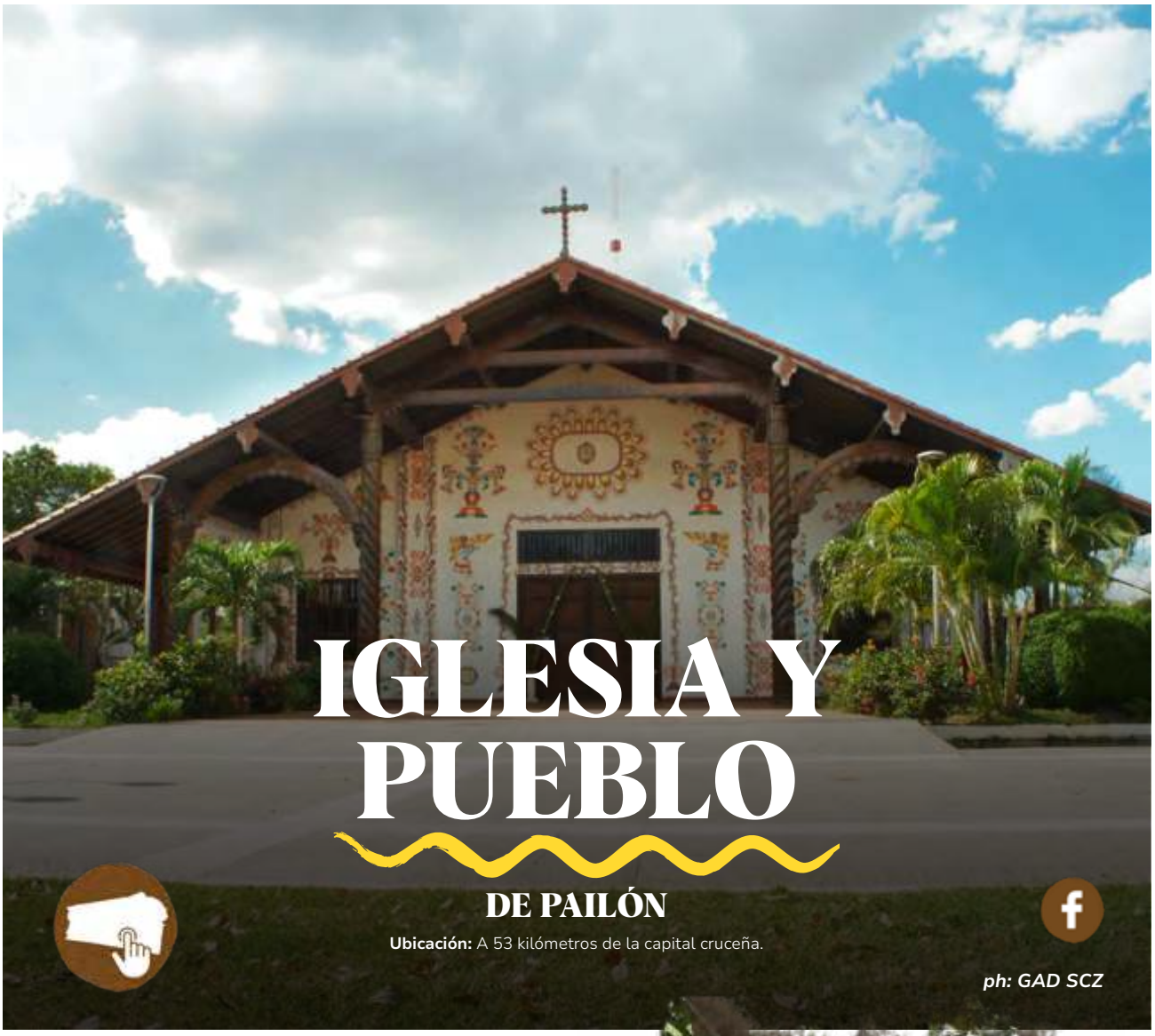

IGLESIA Y PUEBLO

DE PAILÓN

Ubicación: A 53 kilómetros de la capital cruceña.

ph: GAD SCZ

Pailón, un encantador municipio ubicado en la provincia Chiquitos del departamento de Santa Cruz, ofrece a sus visitantes una experiencia única en medio de una extensión de 10,155 km² , de extensión de naturaleza virgen y hospitalidad auténtica. Fundado el 13 de mayo de 1953 y reconocido como municipio el 24 de noviembre de 1993, este destino ha florecido a la puerta de las tierras bajas del este. La geografía de Pailón se destaca por su suelo fértil, creando un entorno ideal para la producción agrícola, especialmente la industria soyera, que se ha convertido en una de las principales fortalezas económicas de la región. Además de disfrutar de la belleza natural del lugar, podrás adentrarte en la rica historia y cultura local, mientras explorás las tradiciones arraigadas que han dado forma a esta vibrante comunidad.

ph: GAD SCZ

ph: Concejo Municipal de Paílón

La fundación de su iglesia nos remonta al 22 de enero de 1996, año que marcó un momento trascendental en la historia de Pailón, cuando el Rvdo. Padre Ansgar Prosegger proclamó solemnemente a la Virgen de Fátima como 'Patrona y Protectora' durante la Santa Misa, celebrada en una modesta aula de la escuela local. Este acto significativo, apenas seis días después de la llegada del sacerdote a la comunidad, resonó con un profundo sentido de devoción y compromiso religioso entre los habitantes del pueblo. Desde entonces, cada 13 de mayo, fecha emblemática en honor a la Virgen de Fátima, la parroquia de Pailón se viste de fervor para celebrar su fiesta patronal. Este día especial no solo conmemora la presencia y protección divina en la vida de la comunidad, sino que también refuerza los lazos de fe y unidad entre sus fieles. Esta localidad escondida en el departamento de Santa Cruz, ha cautivado a viajeros durante siglos con su encanto y ambiente acogedor. Desde su historia hasta sus variadas actividades culturales, Pailón es la puerta a una experiencia única que invita a los visitantes a explorar y descubrir los tesoros de la Chiquitanía.

ph: GAD SCZ

DÍA DE LA TRADICIÓN PAILONEÑA

Ubicación: Km 53, frente a la plaza principal 13 de mayo.

ph: Nacional 13 de mayo

La población de Pailón, de origen chiquitano, celebra con fervor y alegría sus raíces en una fiesta llena de cultura y emoción. Cada año, este municipio celebra el Día de la Tradición Pailoneña, iniciando con una caravana que parte temprano en la mañana, seguida de bailes, música y ofertas gastronómicas como la tradicional e infaltable patasca. En este festejo es común ver a los jóvenes vestidos con trajes típicos como el jasayé y tipoy, entre otras indumentarias, con el fin de preservar las tradiciones y costumbres regionales. Desde el año 2020, el acto suele celebrarse en el parque Ecoturístico de Pailón, donde se presenta a la Reina de Pailón y finaliza al anochecer en medio de fiesta y alegría característicos del municipio. Te invitamos a ser parte de esta celebración única, a que compartás la calidez de la cultura pailoleña y disfrutés de una jornada llena de color, tradición y espíritu.

ph: Nacional 13 de mayo

PARQUE ECOTURÍSTICO

DE PAILÓN

Ubicación: Km 53, sobre perimetral sur.

ph: Amdecruz

El municipio de Pailón, desde el año 2020, cuenta con una hermosa obra construida y destinada para el disfrute de los residentes y los visitantes: el Parque Ecoturístico Pailón. Con la finalidad proporcionar un espacio de esparcimiento, la Alcaldía inauguró este pintoresco parque, pensado en residentes y visitante. Con un pórtico de ingreso estilo chiquitano, este parque ofrece gran cantidad de áreas verdes, recorridos a la sombra y numerosos árboles, juegos para niños de todas las edades y espacios para que podás disfrustar de un churrasco con tus cercanos. Sin duda, el Parque Ecoturístico de Pailón es un espacio recreacional para toda la familia, o incluso, para que pasés un momento de diversión y tranquilidad.

ph: Google

ph: Google

RESTAURANTE

MENONITA

Ubicación: Km 55, camino a surtidor Goteo 111.
Atención: Lunes a domingo 06:00 am a 22:00 pm

ph: MANNA, Cafetería y Panadería

ph: MANNA, Cafetería y Panadería

El municipio de Pailón alberga una maravillosa comunidad menonita llamada Villa Nueva. Esta colonia está ubicada a 77 kilómetros, al costado de la carretera que conecta Santa Cruz con el departamento de Beni. Esta comunidad está conformada por aproximadamente 70 familias denominadas "rebeldes", pues han incorporado a sus vidas la modernidad y las comodidades a su vida diaria.

Dentro de Villa Nueva, se encuentra el restaurante Manna, que ofrece una diversidad interesante tanto a residentes como a visitantes. Inicialmente, encontramos el sector de panadería, en el que preparan gran variedad de panes como es el pan de avena, de centeno, blanco, entre otros. También hay productos más complejos como, tortas, rollitos de canela, galletas, gelatinas y casi cualquier antojo que uno pueda tener respecto a repostería y cafetería. En el sector del restaurante, los comensales podrán elegir deliciosas pizzas, lomitos, carne a la parrilla, pollo a la broaster y otros platos. Ya sea que te encontrés deleitándote con masitas o degustando un plato fuerte, una visita a Manna te asegura una linda experiencia.

ph: MANNA, Cafetería y Panadería

FERIA DEL PESCADO

Ubicación: Km 53, frente a la plaza 13 de mayo.

En el mercado nuevo del barrio Ovidio Barbery, ubicado en el municipio de Pailón, se ofrece una amplia variedad de pescados, en esta feria pintoresca celebrada durante Semana Santa. Entre las opciones disponibles se encuentran sábalo, pacú y surubí, que se sirven acompañados de yuca y limón. Los pescados son servidos a la parrilla y el ambiente se ameniza con música moderna, creando una experiencia culinaria y cultural única para los visitantes. Además, los productores de comunidades menonitas traen productos frescos de sus colonias. Cabe destacar que en esta feria se pueden comprar pescados frescos. Los precios varían de acuerdo con el tipo de pescado que elijás. Disfrutá la deliciosa oferta de Pailón y de su producto estrella: el pescado

PUENTE ESTRUCTURAL

Ubicación: Km 46, sobre río Guapay entre Puerto Pailas y Pailón

ph: Wikipedia

El Puente estructural, conocido como “Pailas”, es un puente vial que cruza el río Guapay formando parte de la ruta N4, la que se dirige al lado este del departamento. Se encuentra entre los municipios de Pailón y Cotoca, ubicado entre las provincias Chiquitos y Andrés Ibáñez. Este puente, que tiene una extensión de 1.400 metros, fue el más extenso en el país hasta el año 2009 y se encuentra ubicado a 60 kilómetros de la ciudad de Santa Cruz de la Sierra. La construcción inició en noviembre del año 2005 y forma parte del corredor bioceánico que vincula a Bolivia con Chile y Brasil. La finalidad de este puente es viabilizar las actividades agrícolas relacionadas al cultivo de semillas oleaginosas de la zona. Este proyecto fue realizado con financiamiento coreano, con el objetivode promover el progreso en el área y su industrial.



COLPA BÉLGICA

ph: Colpa Caranda
ph: GAM C. Bélgica
ph: Carlojvlog
ph: GAD SCZ

COLPA BELGICA

Provincia: Sara
Fundación: La Bélgica se funda con la población trabajadora del ingenio azucarero La Bélgica y el vecino pueblo de Colpa, hasta el 2002 formó parte del municipio de Portachuelo, ubicado en la provincia de Sara. Con el pasar de los años los pueblos de La Bélgica y Colpa quedaron unidos creándose como un solo municipio Colpa – Bélgica, el 1 de febrero de 2002 con la Ley 2325.

DATOS GENERALES

Datos generales: El origen del nombre es la fusión de dos comunidades que se encontraban cercanas Colpa y La Bélgica, que terminaron fusionándose para conformar un nuevo municipio desprendido del municipio de Portachuelo.

CLIMA

Presenta un Clima Subhúmedo Húmedo de verano e invierno cálido, presenta elevadas temperaturas anuales, sin grandes variaciones estacionales.
Temperatura promedio La temperatura media anual es de 24°C

DATOS DEMOGRÁFICOS

Gentilicio: Colpeño/a Belgiqueño/a
Población (2023)[1]: 8.199 habitantes
Densidad (2023): 28 hab./Km²

DATOS GEOGRÁFICOS

Ubicación: 38.7 kilómetros al norte de la ciudad de Santa Cruz de la Sierra

Coordenadas: 17°30'37"S 63°09'53"O

Superficie: 289,73 km²

Altitud : 228 a 329 s.n.m.

ECONOMÍA

Economía[2]: La actividad económica más importantes es manufactura, que de acuerdo al Valor Bruto de Producción (VBP) del municipio representa el 78.03%.

Cuenta con una planta industrial del ingenio azucarero La Bélgica "Don Guillermo" que inició sus labores en la década de los cincuenta. Es una de las empresas que genera trabajo a más de 800 familias que viven en la región. Las actividades agropecuarias son muy importantes para la economía del municipio, siendo la ganadería su pilar más importante.

Valor Bruto de Producción (VBP)[3]: 365 MM Bs.

---

[1] Encuesta de Estimación Poblacional de Santa Cruz 2023. Instituto Cruceño de Estadística
[2] Mapa de Complejidades, BDP 2019
[3] Mapa de Complejidades, BDP 2019

COLPA BÉLGICA

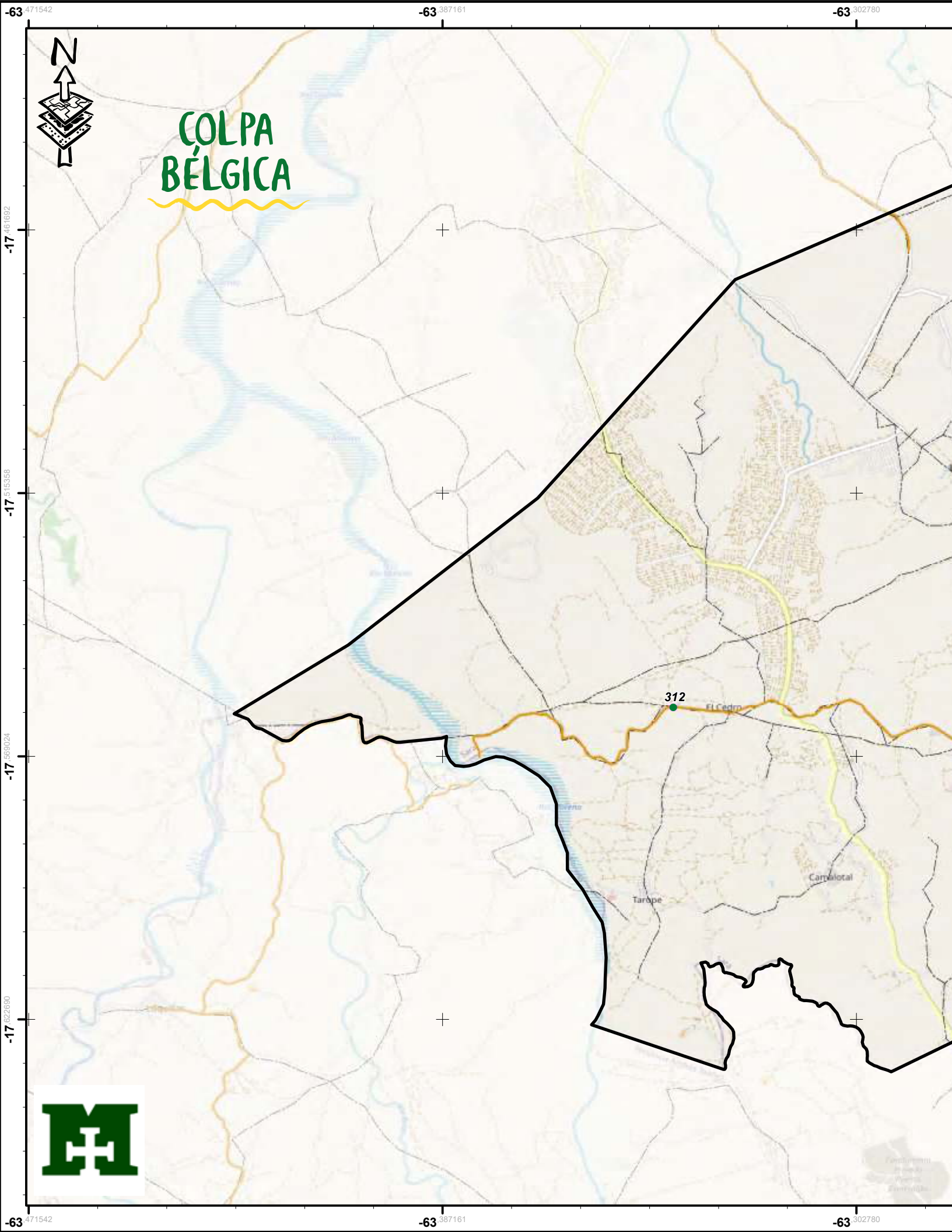

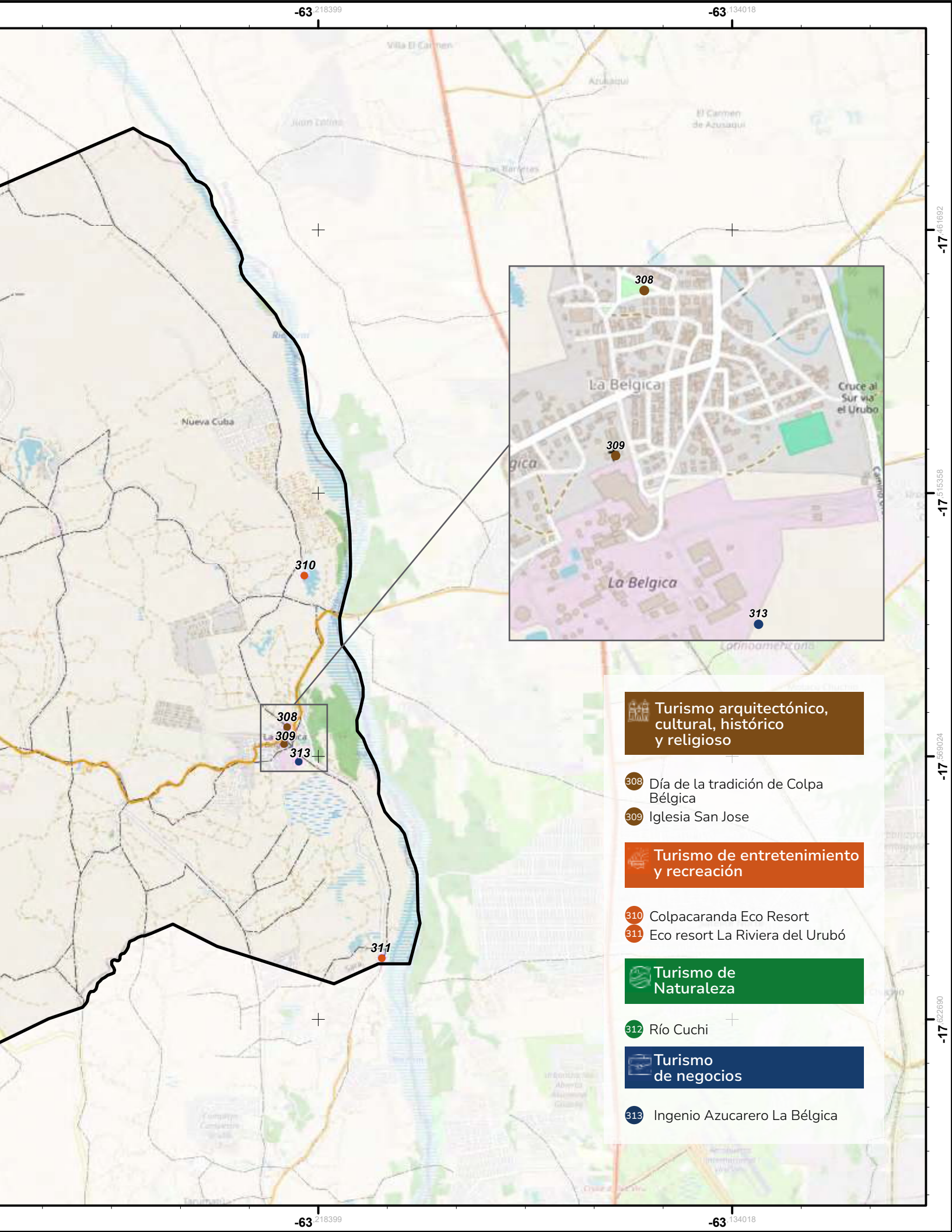
-63.218399
-63.134018
-17.461692
-17.515358
-17.569024
-17.622690
Villa El Carmen
Azusaqui
El Carmen de Azusaqui
Nueva Cuba
La Belgica
Cruce al Sur vía el Urubo
La Belgica
308
309
310
311
313
Turismo arquitectónico, cultural, histórico y religioso
308 Día de la tradición de Colpa Bélgica
309 Iglesia San Jose
Turismo de entretenimiento y recreación
310 Colpacaranda Eco Resort
311 Eco resort La Riviera del Urubó
Turismo de Naturaleza
312 Río Cuchi
Turismo de negocios
313 Ingenio Azucarero La Bélgica

COLPA CARANDA

ECO RESORT

Ubicación: Km 32 1/2, carretera al norte
Atención: Siempre Abierto

ph: Carlojvlog

Colpacaranda Eco Resort es un resort de lujo y serenidad, ubicado a 32 kilómetros de la capital cruceña en el municipio de Colpa Bélgica. Este complejo turístico ofrece a los visitantes una experiencia inolvidable de descanso y recreación. Situado en un entorno natural, combina comodidades de primera clase con vistas panorámicas de bosques y montañas, creando un santuario para los amantes de la naturaleza. Con una variedad de opciones de alojamiento, que van desde lujosas suites hasta acogedores bungalows, cada habitación está diseñada con elegancia y equipada con modernas comodidades para garantizar una estancia confortable.

ph: Colpa Caranda

ph: Colpa Caranda

Como huésped, podrás disfrutar de amplias terrazas y balcones privados con vistas impresionantes. Los restaurantes del resort te ofrecen una experiencia gastronómica excepcional, combinando ingredientes frescos con técnicas culinarias de calidad. Además, el resort brinda una amplia gama de actividades y entretenimiento, que incluyen tratamientos de spa, exploración de senderos naturales, emocionantes excursiones al aire libre y el paseo en tirolesa más extenso del país. Si sos de aquellos que viajan por negocios o deseas organizar eventos especiales, el resort cuenta con instalaciones y servicios para conferencias, reuniones y celebraciones. ¡Conocé este maravilloso complejo turístico!

ph: Colpa Caranda

DÍA DE LA TRADICIÓN

Ubicación: Km. 32 1/2 Carretera al norte

ph: GAM Colpa Bélgica

Cada 17 de septiembre, en este municipio se lleva a cabo una importante celebración: El día de la tradición del Colpa Bélgica. Una celebración vibrante que atrae a visitantes de todo el departamento, llenando el aire del municipio con las alegres melodías de la tamborita, un símbolo de la música típica local. Las festividades comienzan con la elección de la reina de la Tradición. Las participantes pertenecen a diferentes barrios y comparsas carnavaleras de Colpa Bélgica, quienes participarán de una competencia para lograr obtener el anhelado título de la reina de la Tradición de Colpa Bélgica. Durante el día de la Tradición, podrás participar de una variedad de juegos tradicionales que mantienen viva la cultura, entre ellos están el palo ensebao, el jocheo de toros y las riñas de gallos. Una de las atracciones más esperadas es la cabalgata, un desfile que incluye no solo a jinetes locales, sino también a mototaxistas y un grupo de tractores.

ph: GAM Colpa Bélgica

Este festejo ofrece un abanico de delicias típicas preparadas por los residentes. Platos, como un tujuré, patasca y panza rebosada, además de bebidas como el somó y la chicha.

IGLESIA SAN JOSÉ

Ubicación: Km 39, camino a la Laguna.

ph: AMDECRUZ

La parroquia San José de Colpa Bélgica, construida en el 1961, celebra cada 19 de marzo la fiesta de su Santo Patrón con visitantes y fieles de todo el municipio. La celebración está marcada por la esperada visita del arzobispo de la capital cruceña, quien preside la misa solemne, realzando la celebración con su presencia. Esta festividad es una excelente oportunidad para que conozcás la devoción y la calidez de la gente local, mientras disfrutás de un ambiente espiritual y festivo.

El río Cuchí, un tesoro natural situado a tan solo kilómetros del municipio de Colpa Bélgica, es un destino ideal para los amantes de la aventura y la naturaleza. Se encuentra a solo 30 minutos del municipio, con un acceso al río muy emocionante. En este trayecto, el recorrido pondrá a prueba tus habilidades al volante, ya sea en moto o en un vehículo todo terreno de 4x4. Al llegar, te encontrarás aguas cristalinas, listas para ser admiradas y disfrutadas, ideal para que te tomés fotos y disfrutés del atardecer en compañia de tus seres queridos. El ingreso hacia a este prominente río, es a través de la comunidad Taropé, que pertenece al municipio.

Conocido como uno de los ingenios azucareros más antiguos de Santa Cruz, con sus raíces arraigadas hace 67 años bajo el liderazgo de la familia Gasser y desde 1986, bajo la dirección de la familia Gutiérrez. Este emblema de la industria azucarera cruceña no solo fue pionero en la exportación de azúcar a los Estados Unidos, sino que también desempeñó un papel crucial en el desarrollo de la comunidad de La Bélgica, ahora conocida como Colpa Bélgica. Además, destacan sus expansiones internacionales, como la adquisición del ingenio Victoria en Misiones (Argentina) en 2015 y el montaje de la destilería Grizzo en Brasil en 2019, consolidando la posición del Ingenio como un líder regional en la industria y diversificando aún más sus operaciones.

ph: DIRCOM GAM Montero
ph: GAD SCZ

MONTERO

Provincia: Obispo Santistevan
Fundación: En 1854 Ramón Hurtado fundó el pueblo de San Ramón de la Víbora y en 1912 recibió el nombre de Montero, en honor al coronel M. Montero, héroe cruceño de la guerra de la Independencia y de la Batalla de Ingavi.

DATOS GENERALES

La ubicación del Municipio de Montero es privilegiada al tener vinculación caminera asfaltada hacia la ciudad de Santa Cruz de la Sierra y de Cochabamba, formando parte del eje económico nacional.

CLIMA

Clima: clima tropical húmedo – seco
Temperatura promedio: En el transcurso del año las temperaturas generalmente varían de 16°C a 31°C y rara vez bajan a menos de 11°C o suben a más de 35°C. Las temperaturas altas se registran de octubre a marzo, coincidiendo con los meses de mayor pluviosidad y las bajas de mayo a julio, durante la época seca.

DATOS GEOGRÁFICOS

Ubicación: Situada en el corazón agroindustrial de Bolivia, a 52,29 km al norte de la ciudad de Santa Cruz de la Sierra.

Coordenadas: 17°20'00"S 63°23'00"O

Superficie: 369,62 km²

Altitud : 357 m.s.n.m.

DATOS DEMOGRÁFICOS

Gentilicio: Montereño/a
Población (2023)[1]: 168.929 habitantes
Densidad (2023): 457 hab./km²

ECONOMÍA

Economía[3]: La actividad económica más importantes es la manufactura, que de acuerdo al Valor Bruto de Producción (VBP) del municipio representa el 82.42 % respectivamente.

[2]Es conocido por su industria azucarera, esta ciudad es el centro agrícola y cañero donde funciona el Ingenio Azucarero "Guabirá", mayor productor de azúcar y alcohol del país. En cuanto a la producción agropecuaria, Montero tiene como principal cultivo de verano la caña de azúcar y en invierno, el cultivo con mayor importancia es el sorgo.

Valor Bruto de Producción (VBP)[4]: 2.286 MM Bs.

---

[1] Encuesta de Estimación Poblacional de Santa Cruz 2023. Instituto Cruceño de Estadística
[2] PTDI del Municipio de Montero 2015 – 2019
[3] Mapa de Complejidades, BDP 2019
[4] Mapa de Complejidades, BDP 2019

MONTERO

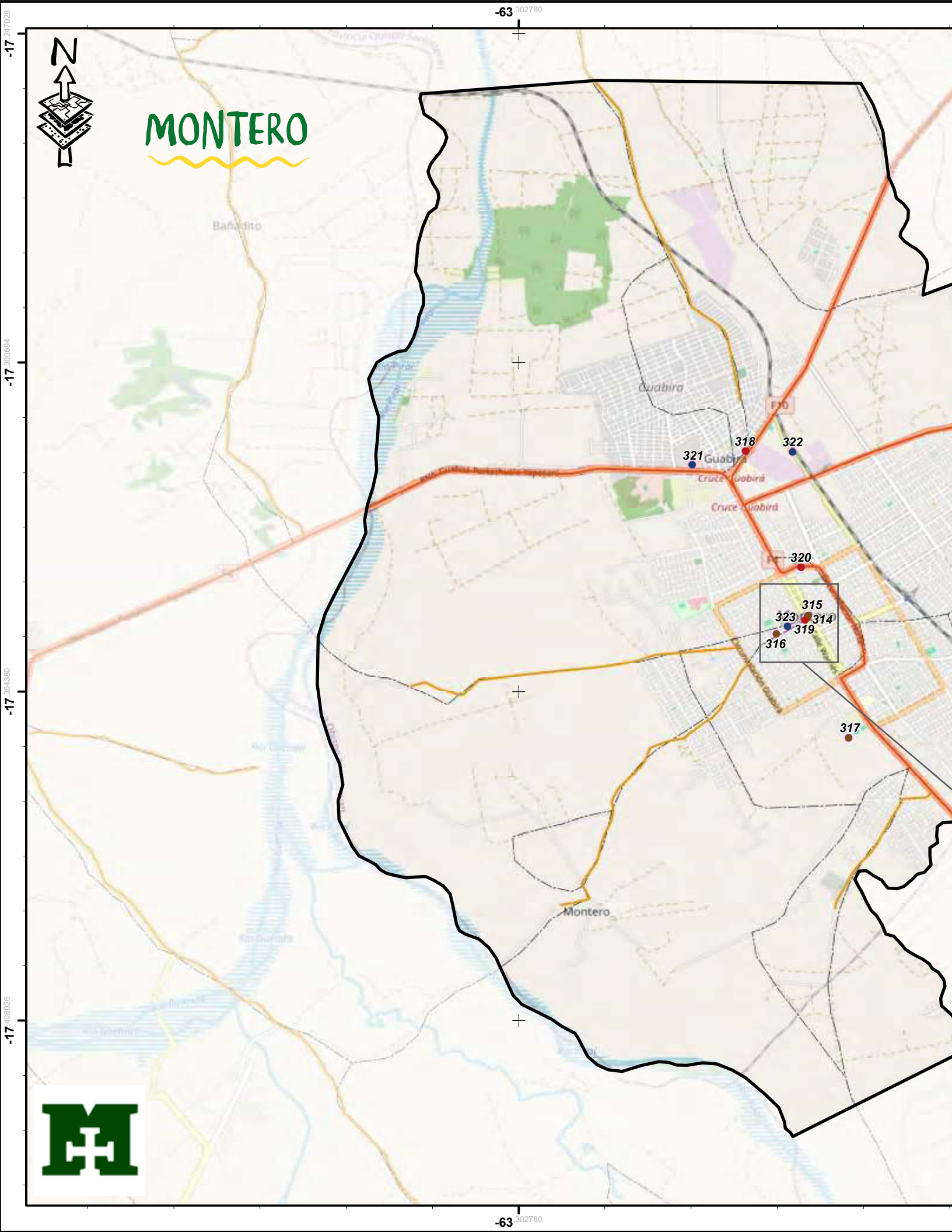
N
-63.302780
-17.247028
-17.300694
-17.354360
-17.408026
Guabirá
Cruce Guabirá
Montero
318
322
321
320
315
323
314
319
316
317

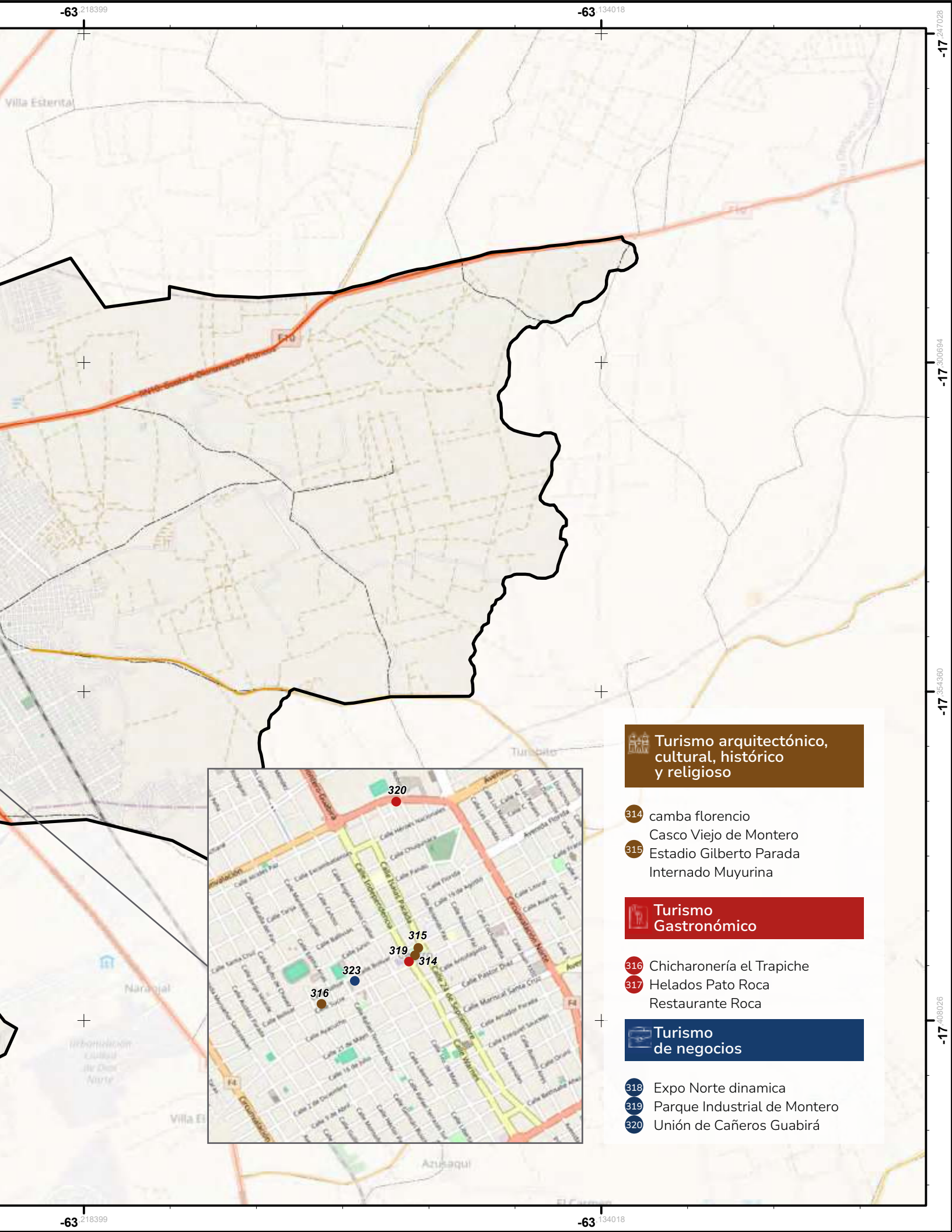
-63.218399
-63.134018
-17.247028
-17.300694
-17.354360
-17.408026
Villa Estrella
Turubate
Naranjal
Urbanización Ciudad de Don Norte
Villa El
Azucaqui
320
315
319
314
323
316
Turismo arquitectónico, cultural, histórico y religioso
314 camba florencio
Casco Viejo de Montero
315 Estadio Gilberto Parada
Internado Muyurina
Turismo Gastronómico
316 Chicharonería el Trapiche
317 Helados Pato Roca
Restaurante Roca
Turismo de negocios
318 Expo Norte dinamica
319 Parque Industrial de Montero
320 Unión de Cañeros Guabirá

CASCO VIEJO

DE MONTERO

Ubicación: Perímetro contemplado dentro del primer anillo, desde el kilómetro cero, entre ruta N4 y Av. Cv. Andrés Ibáñez.

ph: DIRCOM GAM Montero

En el norte de la metrópoli cruceña, se encuentra una joya que encierra siglos de historia y cultura: el Casco Viejo de Montero. Este encantador legado colonial es un testimonio vivo del pasado de la región y un destino turístico que cautiva a los visitantes con su arquitectura, sus calles empedradas y su ambiente pintoresco. Este municipio nació a partir de una comarca denominada "San Ramón de la Víbora", fundada el 31 de agosto de 1854. El 2 de diciembre de 1941, cuando gobernaba Enrique Peñaranda, crea la provincia Obispo Santistevan y Montero se constituye en su capital y primera sección municipal. La ley del 3 de diciembre de 1986, promulgada por el entonces presidente Víctor Paz Estenssoro, eleva a este hermoso municipio al rango de ciudad, pues era evidente su gran avance en todos los aspectos. Actualmente, Montero cuenta con una gran variedad de centros de producción, comercios y servicios en el parque industrial como también en sus calles principales. En el centro de la plaza se encuentra erigida la estatua del coronel Marceliano Montero, héroe de la batalla de Ingavi, a quien se homenajea cada 18 de noviembre; a su alrededor, se encuentran infinidad de comercios que benefician a lugareños y visitantes. Si paseas por la extensa plaza podrás disfrutar de la brisa y sombra que regalan los muchos árboles que allí se encuentran. Montero alberga una serie de monumentos históricos, como la parroquia Las Mercedes y la Casa de la Cultura, que te ofrecen la oportunidad de sumergirte en la historia y el patrimonio de este maravilloso lugar. El Casco Viejo de Montero es también un centro de actividad cultural y tradición, donde se celebran numerosos festivales y eventos a lo largo del año. Es, además, el hogar de una vibrante comunidad de productores de azúcar y apasionados por el fútbol, quienes, a lo largo de los años han sabido unificar esa pasión para hacer conocer a Montero como un epicentro de la producción de caña.

ph: DIRCOM GAM Montero

HELADOS PATO ROCA

Ubicación: Calle Independencia, esq. Sucre
Atención: Lunes a Domingo - 10:00 a 21:30

ph: DIRCOM GAM Montero

ph: DIRCOM GAM Montero

Desde su modesto inicio, hace más de 50 años, Helados Pato Roca ha sido más que una simple heladería; se ha convertido en una tradición arraigada en la comunidad montereña. Fundada por la pasión por crear helados de alta calidad con ingredientes frescos y naturales, la heladería ha mantenido su compromiso con la excelencia y la autenticidad a lo largo de los años. Lo que distingue a Helados Pato Roca es la variedad de sabores y lo tradicional de su preparación. En una maravillosa tarde con el sol en plenitud, ¿qué mejor que deleitarte, por ejemplo, con los picolés más clásicos como vainilla o chocolate? Y, si sos más aventurero, podés degustar opciones más exóticas como maracuyá, guanábana y chirimoya. Cada mordizco es una explosión de sabor, una fusión perfecta entre la cremosidad del helado y la frescura de los ingredientes locales cuidadosamente seleccionados. La clave del éxito de Helados Pato Roca radica en su dedicación a la artesanía y la calidad. Cada lote de helado se prepara con esmero en pequeñas cantidades, garantizando así la frescura y la consistencia en cada cucharada. Los maestros heladeros de la heladería combinan técnicas tradicionales con un toque de innovación para crear verdaderas obras maestras heladas que satisfacen incluso a los paladares más exigentes. Además de ofrecer helados de primera calidad, Helados Pato Roca es un espacio de encuentro y alegría para personas de todas las edades. Su acogedor ambiente y su cálida atención hacen que cada visita sea una experiencia memorable. Ya sea que estés disfrutando de un helado con amigos después de un día caluroso, o celebrando un evento especial con la familia, Helados Pato Roca siempre te recibirá con una sonrisa y un helado delicioso en la mano. Helados Pato Roca es mucho más que una heladería; es un símbolo de identidad, tradición y calidad del municipio de Montero.

CAMBA FLORENCIO

Ubicación: Plaza principal de Montero



ph: DIRCOM GAM Montero



ph: DIRCOM GAM Montero

ph: Santa Cruz de la Sierra Despertad

En la rica tradición oral de Santa Cruz, hay un personaje que brilla con luz propia: el inigualable Camba Florencio. Conocido por sus hazañas legendarias y su espíritu indomable, este personaje se ha convertido en una figura icónica en la historia y la cultura de la región, dejando una huella imborrable en la imaginación de los cruceños. A lo largo de su carrera, Camba Florencio se distinguió por su profunda conexión con las tradiciones y costumbres locales, capturando la esencia del hombre y la mujer de esta tierra oriental con una autenticidad inigualable. Su obra, impregnada de la riqueza y diversidad de la cultura camba, sirve como un testimonio perdurable de la identidad única de esta región, que se destaca por sus características propias en comparación con otras partes del país. El año 1964 marcó el debut oficial del Camba Florencio en el ámbito teatral, uniéndose al Teatro Sol y Horizonte de Montero. Desde entonces, su carrera floreció, colaborando con diversos elencos y compartiendo escenario con destacadas figuras del teatro boliviano, entre ellas Humberto Vaca Pereira, Humberto Parada Caro y Enrique Alfonso. Sin embargo, sería en la década de los noventa cuando alcanzaría un reconocimiento nacional al unirse al elenco de la productora Safipro, participando en aclamados dramas como “Carmelo Hurtado”, “La Virgen de las 7 Calles” y “La Última Expedición”. Él, con su peculiar sombrero de sao, abarcas desgastadas por el trajín y trabajo diario, su machete y charuto que jamás podían faltar, acompañaban a su barba espesa que fue pintándose de blanco con los años, es mucho más que un personaje de leyenda; constituye un símbolo de la identidad y la esencia de Santa Cruz. No fue hasta un doloroso 26 de julio de 2010, que nuestro declamador costumbrista perdió la vida a causa de una falla cardiaca. Ahora, vive en la historia como un representante cultural para la región.

ph: Santa Cruz de la Sierra Despertad

UNIÓN DE CAÑEROS GUABIRÁ

Ubicación: Casco viejo de Montero, sobre calle Bolivar entre Rafael Terrazas y c Cañoto
Atención: Lunes a viernes: 8:00 a 12:00 y 14:00 a 18:00 Hrs. Sábado: 08:00 a 12:00 Hrs.

ph: GAM Montero

En Montero, el sector cañero-azucarero se destaca como uno de los motores fundamentales de la economía local. Con su notable impacto en la generación de empleo, ingresos y divisas para la región, esta industria no solo impulsa el desarrollo socioeconómico, sino que también contribuye a la identidad y prosperidad del departamento. Conocida como la tierra del azúcar desde épocas de antaño, esta región ha sido un crisol de tradiciones que se remontan a épocas anteriores a la llegada de los ingenios azucareros. Antes de su industrialización, el dulce néctar de la caña se elaboraba artesanalmente en los tradicionales trapiches de palo, dando lugar a la exquisita "azúcar morena". Este legado se preserva con orgullo en cada rincón de Santa Cruz, donde la historia se fusiona con la dulzura de su producción azucarera, antes envasada con esmero en utensilios de barro que atestiguan la autenticidad de sus tradiciones producti-

vas. La Unión de Cañeros Guabirá es una asociación gremial agropecuaria que se erige como un pilar clave en la producción de caña de azúcar en el departamento de Santa Cruz. Fundada en 1996 en el municipio de Montero, capital de la provincia Obispo Santistevan, es una organización sin fines de lucro que se ha destacado por su compromiso con la excelencia y la sostenibilidad en la producción agrícola. Con más de 54,000 hectáreas de caña de azúcar bajo su cuidado y una producción promedio de más de 57 toneladas por hectárea, la Unión de Cañeros Guabirá juega un papel fundamental en el abastecimiento del Ingenio Azucarero. Con su impacto significativo en la economía regional y su enfoque en la sostenibilidad, esta asociación es un ejemplo destacado del espíritu emprendedor y la innovación agrícola en nuestro departamento. Sin lugar a dudas, la producción de azúcar es parte de la identidad del municipio de Montero.

PARQUE INDUSTRIAL

DE MONTERO

Ubicación: Av. Cadetes tres pasos al frente

ph: GAM Montero

El Parque Industrial de Montero, establecido para impulsar la industrialización y el crecimiento del norte del departamento de Santa Cruz, cuenta con una extensión total de 2.500 hectáreas, de las cuales 633 están ocupadas. Ubicado a 56 kilómetros de la capital del departamento, el parque se divide en dos áreas: una de 183 hectáreas gestionada por la Alcaldía de Montero y otra de 450 hectáreas destinada a empresas privadas. Desde su inauguración en junio de 2002, el parque ha experimentado un crecimiento continuo, convirtiéndose en un referente de innovación e industrialización. El desarrollo del parque no ha sido fácil; los primeros empresarios tuvieron que limpiar la maleza y trabajar con la alcaldía para desarrollar la infraestructura básica, como servicios y carreteras. Hoy en día, aunque aún se trabaja en mejorar los espacios, las condiciones han mejorado significativamente para los nuevos empresarios. Para adquirir un terreno, las empresas solo necesitan presentar un proyecto bien diseñado, con opciones de pago al contado o facilidades como plazos y bajas tasas de interés. El parque alberga una diversidad industrial, destacándose la agroindustria con empresas dedicadas al procesamiento de alimentos, producción agrícola y agroexportación. Montero, considerada el cuarto municipio más poblado del departamento, está posicionándose como el epicentro nacional de la comercialización de granos, con más de 150 empresas operando en el parque y generando empleo para más de 2.000 personas directamente y 15.000 indirectamente. El Parque Industrial de Montero tiene un impacto significativo en la economía y la sociedad de la región, contribuyendo a la reducción del desempleo y a la mejora del nivel de vida de la población. Además de atraer inversiones y fomentar la competitividad empresarial, promueve la transferencia de tecnología y conocimiento, estimulando el desarrollo y la innovación. Se espera que el Parque continúe creciendo y desarrollándose, atrayendo nuevas inversiones y empresas.

Una feria comercial y cultural que se ha convertido en un punto de encuentro clave para empresarios, emprendedores, artistas y amantes de la cultura en la región. Exponorte dinámica tiene sus raíces en la necesidad de promover el comercio y la industria en la región norte de Santa Cruz. Gracias a la iniciativa de ganaderos y empresarios visionarios del Norte Integrado, se da inicio a la feria en 1992 con una duración de 3 días. Los organizadores del evento fueron Aganorte (Asociación de Ganaderos del Norte), Cainco Norte (Cámara de Industria y Comercio del Norte) y Aplenor (Asociación de Productores de Leche del Norte). El principal objetivo de Exponorte dinámica es crear un espacio donde converjan los sectores comerciales e industriales, proporcionando una plataforma para el intercambio de ideas, la promoción de productos y servicios. Esta feria abarca una variada gama de temáticas y sectores, lo que la convierte en un evento inclusivo y diverso que atrae a una audiencia amplia. Son empresas locales, regionales e internacionales quienes exhiben sus productos y servicios, ofreciendo oportunidades de networking y ventas. A lo largo de los años, esta feria alcanzó dos reconocimientos por parte del Gobierno Municipal de la ciudad de Montero: Como Patrimonio Cultural a la Feria Exposición del Norte, con la Ordenanza Municipal Nro. 10/97 y la Institución Meritoria a la Feria Exposición del Norte, con la Ordenanza Municipal Nro. 51/94. Se presentan innovaciones en maquinaria, equipos industriales, tecnología y soluciones empresariales, brindándote la oportunidad de que conozcás las últimas tendencias y desarrollos en diversos campos industriales. Exponorte Dinámica tiene un impacto significativo en Santa Cruz y sus alrededores en varios aspectos. A medida que Exponorte Dinámica continúa creciendo y evolucionando, se espera que siga desempeñando un papel clave en la promoción del desarrollo económico, cultural y social de Santa Cruz y la región norte del país.

PORTACHUELO

ph: Parroquia Inmaculada Concepción Portachuelo
ph: GAM Portachuelo
ph: Horneados Portachuelo

PORTACHUELO

Provincia Sara
Fundación: Fue fundada el 8 de diciembre de 1770 por el sacerdote Juan Felipe Vargas, colaborado por el Capitán Francisco Javier Baca y el Sargento Mayor Diego de Bazán con el nombre de “La Inmaculada Concepción de la Virgen María de Portachuelo”.

DATOS GENERALES

Declarada como la “capital arrocera” de Bolivia y considerada uno de los pueblos más tradicionales de Santa Cruz. Son apreciadas las festividades religiosas por su manera tradicional de celebrarlas. En la gastronomía típica se caracteriza por el manjar blanco o dulce de leche, roscas de arroz y de maíz, empanizados, cuñapes, o las famosas “Salchichas de Portachuelo”.

CLIMA

Húmedo subtropical. Julio es su mes más frío del año y noviembre el más caliente.

DATOS GEOGRÁFICOS

Ubicación: 75 km al noroeste de la ciudad de Santa Cruz de la Sierra

Coordenadas: 17°21'17"S 63°23'41"O

Superficie: 1.069 Km²

Altitud : 289 s.n.m.

DATOS DEMOGRÁFICOS

Gentilicio: Portachueleño -a
Población (2023)[1]: 25.213 habitantes
Densidad (2023): 24 hab./Km²

ECONOMÍA

Economía[2]: Las actividades económicas más importantes son el pecuario y agrícola que de acuerdo al Valor Bruto de Producción (VBP) del municipio representan el 44.44% y 36.16 % respectivamente.

La población se dedica principalmente a la agricultura de los cultivos de arroz, caña de azúcar, soya, maíz y yuca. El cultivo del arroz representa el primer producto de la canasta familiar, ocupa el mayor número de mano de obra y genera gran movimiento económico. Los excedentes, en grandes volúmenes, son comercializados en el interior del país y son exportados.

Existe también una significativa riqueza ganadera, porcina y también la avícola que se comercializa en ciudades del interior de Bolivia.

Valor Bruto de Producción (VBP)[3]: 498 MM Bs.

---

[1] Encuesta de Estimación Poblacional de Santa Cruz 2023. Instituto Cruceño de Estadística
[2] Mapa de Complejidades, BDP 2019
[3] Mapa de Complejidades, BDP 2019

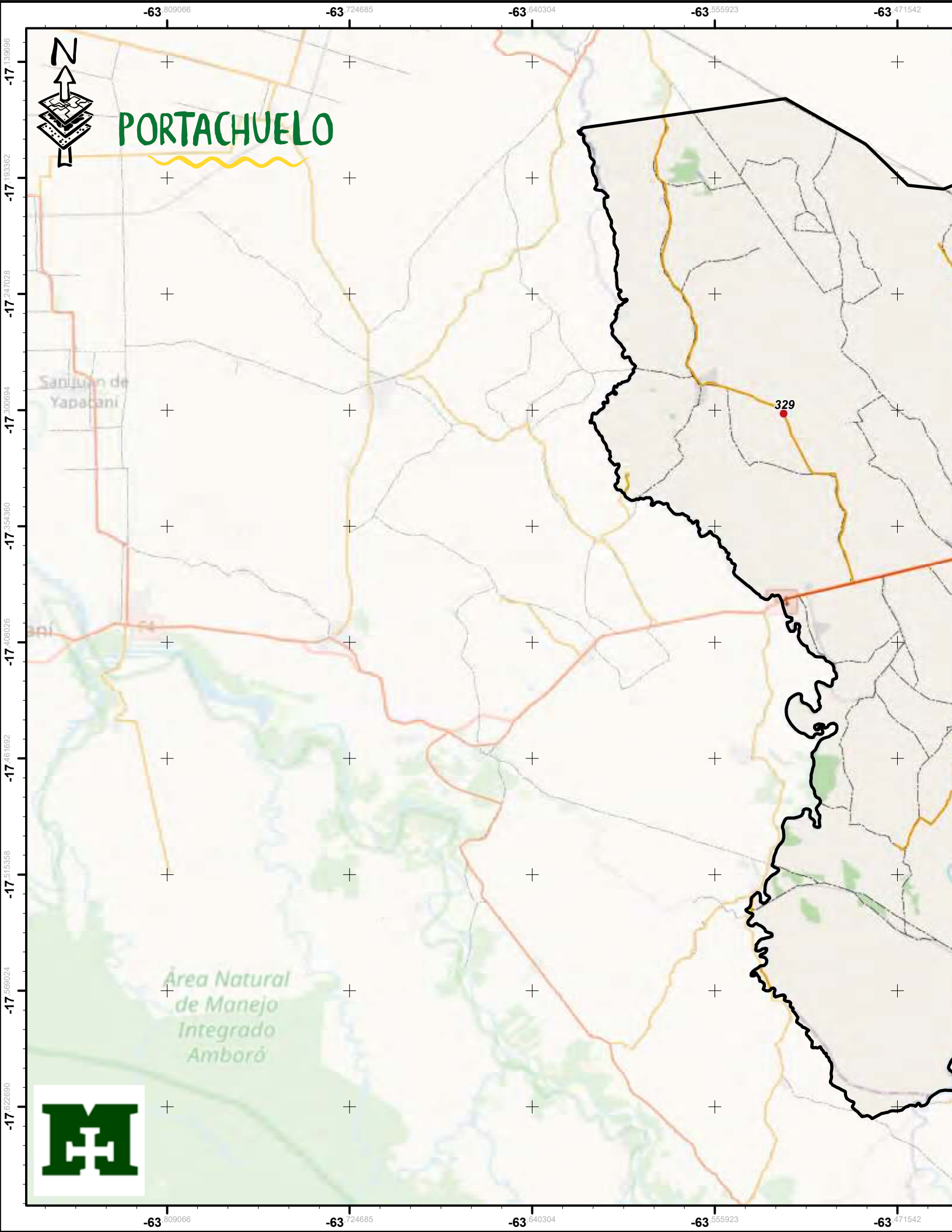
PORTACHUELO
N
329
Área Natural
de Manejo
Integrado
Amboró
-63.809066
-63.724685
-63.640304
-63.555923
-63.471542
-17.139696
-17.193362
-17.247028
-17.300694
-17.354360
-17.408026
-17.461692
-17.515358
-17.569024
-17.622690

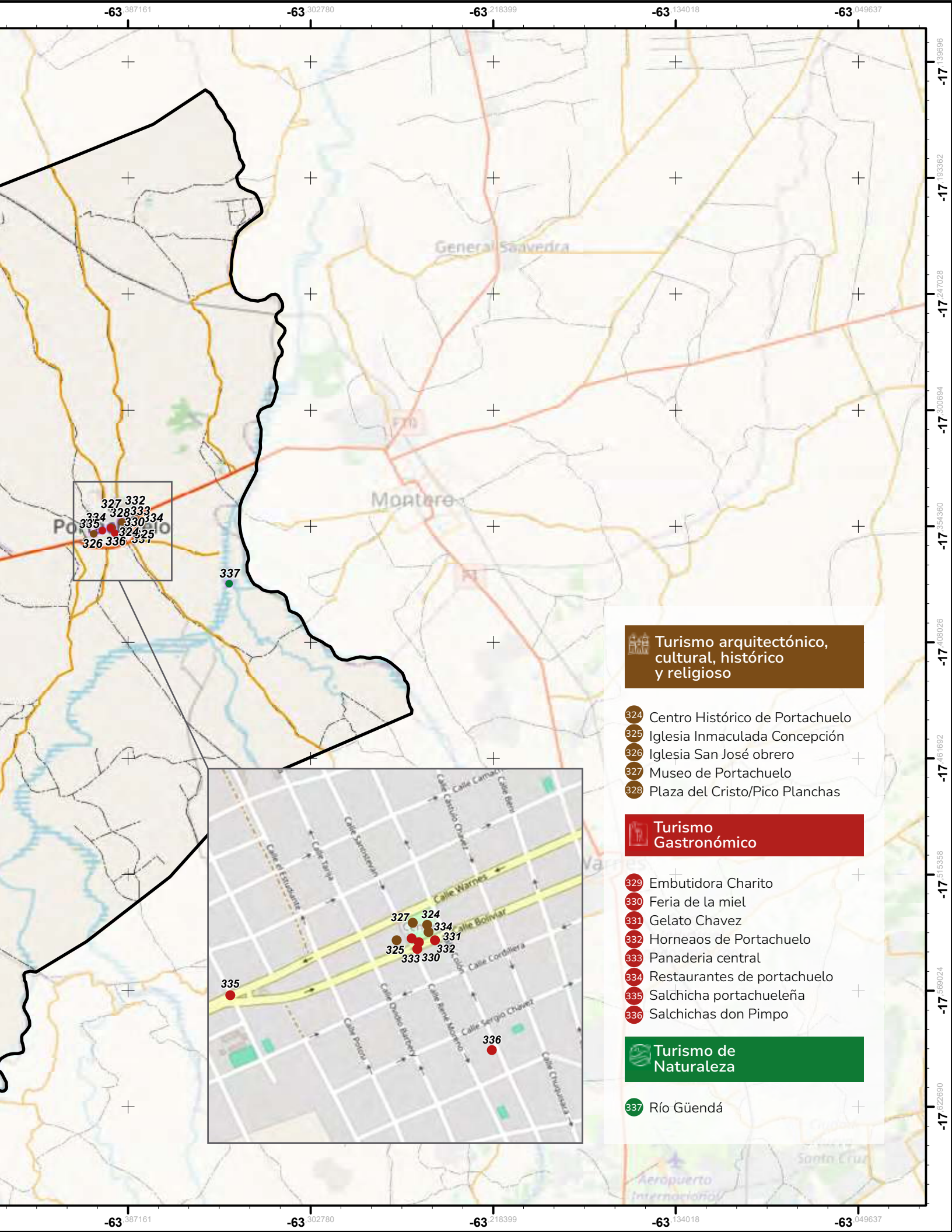

Turismo arquitectónico, cultural, histórico y religioso

- 324 Centro Histórico de Portachuelo
- 325 Iglesia Inmaculada Concepción
- 326 Iglesia San José obrero
- 327 Museo de Portachuelo
- 328 Plaza del Cristo/Pico Planchas

Turismo Gastronómico

- 329 Embutidora Charito
- 330 Feria de la miel
- 331 Gelato Chavez
- 332 Horneaos de Portachuelo
- 333 Panaderia central
- 334 Restaurantes de portachuelo
- 335 Salchicha portachueleña
- 336 Salchichas don Pimpo

Turismo de Naturaleza

- 337 Río Güendá

CENTRO HISTÓRICO

Ubicación: Perimetro contemplado entre esquinas Boliva, Coronel Mercado, Sucre y Monseñor Rivero

ph: Portachuelo Turístico

El histórico pueblo de Portachuelo, se encuentra ubicado a 71 kilómetros de Santa Cruz de la Sierra y fue fundado el 8 de diciembre de 1770, gracias a la iniciativa del sacerdote Juan Felipe Vargas, quien contó con la colaboración del Capitán Francisco Javier Baca y el Sargento Mayor Diego de Bazán. Este pintoresco e importante lugar fue nombrado "La Inmaculada Concepción de la Virgen María de Portachuelo". Existen múltiples razones que explican la fundación del ahora municipio. En primer lugar, la oportunidad del comercio a consecuencia de las misiones jesuitas de la región; la amenaza de que los colonizadores portugueses (quienes poblaban la zona amazónica)quisieran expandir su conquista a tierras pertenecientes a la corona española y por último, la búsqueda mítica del Dorado. Posterior a que los jesuitas fueran expulsados del reino de España y de sus territorios colonizados en la actual América, las iglesias misionales abandonadas empezaron a sufrir saqueos. En consecuencia a estos problemas, el rey ordenó la fundación de "ciudades" que fungieran como pilares de defensa y presencia del Reino de España. Estas nuevas ciudades fueron de carácter realengo (es decir, de carácter real), dentro de los dominios de la corona. Es así como nace la "ciudad" de Portachuelo, que fue poblada por españoles, tomando en cuenta la poca confianza que había en los criollos y mestizos que vivían aquí y eran considerados un riesgo terrible para los planes realistas. Gracias a eso, es que a través de los años, se fue edificando la ciudad de Portachuelo. Sus calles y casas aún conservan el legado arquitectónico de los españoles, fusionado con las características de la construcción de la región. No te perdás la oportunidad de conocer este encantador municipio, lleno de historía, cultura e identidad de Santa Cruz.

ph: Portachuelo Santa Cruz

MUSEO

DE PORTACHUELO

Ubicación: Calle Bolivar, entre René Moreno y Colón
Atención: Lunes a Viernes - 08:00 a 12:00 y 14:00 a 18:00

ph: El País Tarija

El museo de Portachuelo alberga una impresionante colección de tesoros que enriquecen el legado histórico del departamento y despiertan la curiosidad de quienes lo visitan. Ubicado dentro de la Casa de la Cultura, el museo cuenta con una asombrosa colección de 850 objetos, entre documentos históricos y coloniales, como cartas de la Guerra del Chaco, balas y bayonetas de la época, siendo estos los más representativos. Además, se exhiben piezas de las culturas chané y tiahuanacota. Entre los archivos, también hay libros notariales de 120 años atrás, con información sobre la fundación de los municipios de Montero, Saavedra (antes Bibosí), San Carlos y Buena Vista. Se destaca un relicario que data aproximadamente de los años 1770, libros coloniales de 1778 y manuscritos de curas que viajaron desde el Viejo Mundo al país durante la época colonial. Como una de sus últimas adquisiciones, el museo posee las cinco campanas de la Iglesia Inmaculada Concepción de Portachuelo, que estuvieron colgadas entre los años 1863 y 1903. No te perdás la oportunidad de visitar el museo de la Casa de la Cultura de Portachuelo; es, sin lugar a dudas, una experiencia que te permitirá reconectar con la historia de la región.

MIRADOR

EL CRISTO

Ubicación: Sobre calle Warnes y Boliviar, en la esquina del pico de plancha.

ph: ALD SCZ

Desde 2022, la Plaza Moderna “El Cristo” busca ser un lugar donde los residentes y visitantes puedan disfrutar de actividades recreativas. Esta plaza tiene como atractivo principal el famoso mirador de Portachuelo, que posee el símbolo representativo del municipio en su parte más alta. Este mirador tiene dos niveles, ambos ideales para sacarse fotos con vista a la localidad. Además, en este espacio los niños podrán divertirse y jugar, mientras que los padres pueden descansar y disfrutar de la tranquilidad de este municipio. En los alrededores de la plaza, específicamente en la calle de enfrente, se encuentran los famosos agachaos sobre el Pico de Plancha, donde podrás disfrutar de bocados de comida tradicional de la región. Estos agachaos son reconocidos por ofrecer una amplia variedad de platos cotidianos y típicos en Portachuelo.

IGLESIA DE LA

INMACULADA CONCEPCIÓN

Ubicación: Calle René Moreno, entre calle Bolivar y Warnes

ph: Wikipedia

Al igual que el municipio de Portachuelo, esta legendaria iglesia, que comenzó bajo la denominación de viceparroquia de la Inmaculada Concepción, tiene una de las historias más antiguas del norte integrado cruceño. En el siglo XVII, durante el apogeo de la corona española, el gobernador Luis Álvarez de Nava dejó una huella perdurable en la historia de Santa Cruz al convertirse en fundador de Portachuelo. El 8 de diciembre de 1770, la capilla recién construida con hojas de palma y una estructura de madera rústica, fue inaugurada bajo el nombre de Inmaculada Concepción de la Virgen María de Portachuelo. La construcción de la iglesia tardó alrededor de 200 años. En un inicio, fue edificada por europeos y feligreses, y en una fase posterior, fue construida y terminada bajo la dirección del párroco de la iglesia, José María Ruíz Díaz, quien fue un referente importante para los residentes de Portachuelo. Además de la iglesia, dejó un legado de aporte trascendental en la comunidad.

IGLESIA

SAN JOSÉ OBRERO

Ubicación: Av Jose Maria Ruiz, entre calle San José obrero y Portachuelo

ph: Parroquia Inmaculada Concepción Portachuelo

Visitá la Iglesia de San José Obrero en Portachuelo, un símbolo religioso que marca la historia local desde la llegada de los salesianos el 30 de enero de 1994. Este templo, es el corazón de una vibrante vida pastoral, con más de 20 grupos activos que apoyan a más de 15 comunidades rurales. Su enfoque en la educación y la juventud ha revitalizado la localidad, convirtiendo a Portachuelo en un referente educativo y religioso en el norte de Santa Cruz.

JINETES

DEL NORTE

Ubicación: Recorrido de 67 kilómetros, desde Portachuelo a Porongo

ph: GAM Porongo

La cabalgata de Jinetes del Norte es un evento que recuerda las tradiciones y a los próceres cruceños, en las luchas por la independencia de Santa Cruz. Además, busca incentivar en las nuevas generaciones los valores cívicos y el amor por los símbolos regionales. Esta antigua tradición, se práctica desde 1999 Cuando se conmemoraba la independencia de Santa Cruz, pero en los últimos años se ha perpetuado en homenaje a la fundación, ya que el evento ahora se celebra en vísperas del 26 de febrero. Originalmente, la cabalgata comenzaba en el municipio de Portachuelo y finalizaba en el emblemático Cristo Redentor; sin embargo, el crecimiento poblacional de la capital cruceña impide que los jinetes lleguen hasta dicho monumento. A pesar de esto, los Jinetes del Norte continúan realizando el recorrido, solo que ahora visitan el municipio de Porongo. Son alrededor de 60 jinetes que, con la bendición del párroco de la Iglesia Inmaculada Concepción, parten e inician la cabalgata por múltiples comunidades hasta llegar a su destino. Flavio Ríos Güenda, Perotó, La Perdiz, Las Cruces y Terebinto algunas de las comunidades testigos de este impresionante acontecimiento, que reúne a ambos municipios en una fiesta de celebración y alegría. Los jinetes son recibidos con entusiasmo, acompañados de una melodiosa tamborita y comida típica.

SALCHICHA PORTACHUELEÑA

Ubicación: Portachuelo, Santa Cruz – Bolivia.

ph: Charito Fiambres & Embutidos

Un producto culinario que data de hace más de 50 años y que se ha convertido en un referente cruceño de gama internacional, te presentamos la salchicha portachueleña. El secreto de la receta de la Salchicha Portachueleña reside en la mezcla de especias y condimentos tradicionales que se utilizan para sazonar la carne de cerdo. Una vez que la carne de cerdo ha sido sazonada con las especias y condimentos adecuados, se procede al proceso de embutido, donde se rellenan tripas naturales con la mezcla de carne y especias. Este paso es crucial para darle a la salchicha su forma característica y garantizar una textura jugosa y tierna una vez cocida. Después del embutido, las salchichas se ahúman lentamente sobre brasas de leña, lo que les otorga un sabor ahumado único y una profundidad de sabor que distingue a este peculiar embutido de otras variedades de salchichas. Además, la producción y venta de la Salchicha Portachueleña contribuye a la economía local, generando empleo y apoyando a las pequeñas empresas y productores locales, que estiman haber incrementado la producción un 1900% en los últimos 50 años. Su sabor único continúa conquistando paladares y dejando huella en cada bocado. ¡Vení a disfrutar de la auténtica Salchicha Portachueleña!

SALCHICHAS
DON PIMPO

Ubicación: Calle Colón Sur, N°210 Portachuelo.
Atención: 06:00 a 23:00 Hrs.

Hace 50 años, la familia Landívar trajo a Portachuelo una receta especial para la producción de salchicha, que sería parte de un legado en la historia de este municipio. A la fecha, Arsenio Alba, conocido cariñosamente como Don Pimpo, es quien lidera el negocio durante los últimos 30 años. Bajo su dirección, la empresa ha mantenido y perfeccionado la tradición familiar, asegurando la calidad y el sabor auténtico de sus productos. La dedicación de Don Pimpo ha consolidado el legado de su familia, convirtiendo el negocio en un referente local.

FERIA DE LA SALCHICHA
PORTACHUELEÑA

Ubicación: Av. Cambodromo, 4to anillo. Santa Cruz de la Sierra

Portachuelo y su emblemática feria de la salchicha, es un evento que destaca lo mejor de la gastronomía local y que reúne alrededor de 70 productores. Esta feria, te deleitará con una gran variedad de productos gastronómicos, artesanales e innvadores del municipio. Durante este evento, tendrás la oportunidad de disfrutar de una amplia selección de salchichas, preparadas con las recetas tradicionales y con un toque innovador. Entre esta variedad de salchichas, las más destacadas son las salchichas tradicionales, las salchichas con verduras, las salchichas picantes, y las salchichas elaboradas con chorizo 'viena' (que viene con queso y verduras). También encontrarás varios platos a base de chancho, como el escabeche, además de embutidos como morcilla y enrollado. La producción de la salchicha portachueleña ha alcanzado gran renombre, exportándose ya fuera del país y logrando que esta tradición cruceña sea conocida a nivel internacional. Cada año, la feria atrae a una gran cantidad de visitantes que disfrutan no solo de la gastronomía, sino también de un ambiente vibrante lleno de cultura local. A lo largo del evento, los asistentes podrán disfrutar de actividades como ballet, grupos musicales en vivo, juegos tradicionales y otros espectáculos que enriquecen esta celebración. Sin duda, es un evento que no solo resalta lo mejor de la comida, sino también la calidez de la gente de Portachuelo. ¡No te perdás de los sabores y la virtud culinaria de Portachuelo!

CHARITO
FIAMBRES Y EMBUTIDOS

Ubicación: Km 92, carretera a Santa Rosa del Sara.
Atención: Lunes a viernes: 07:00 a 18:00 Hrs.
Sábado: 07:00 a 11:00 Hrs.

Para disfrutar un buen churrasco junto a tu familia o amigos, no pueden faltar los chorrizos "Charito Fiambres y Embutidos" en tu parrilla. Esta innovadora empresa del municipio te ofrece una variedad de chorizos de excelente calidad, como chorizo parrillero, chorizo ahumado y chorizo criollo además de jamón, enrollado de cerdo, salchicha portachueleña y morcilla. Todas estas opciones son ideales para llevar a casa y ser anfitrión de excelentes momentos. No dudes en adquirir estos deliciosos productos.

HORNEADOS

PORTACHUELEÑOS

Ubicación: Dentro del centro histórico de Portachuelo

ph: Horneados Portachuelo

Portachuelo, un hermoso municipio que se caracteriza por la hospitalidad de su gente, es también un referente culinario cuando se habla de los horneados típicos. Estos son algunos lugares que definitivamente no podés perderte. El primer lugar es la Panadería Doña Laida, con más de 50 años de experiencia en la preparación de horneados. La segunda es la Panadería La Olla Típica, donde podrás probar deliciosos panes de arroz, empanadas y cuñapés, acompañados de un buen café. Por último, la Panadería Café con Leche ofrece una deliciosa oferta culinaria típica, ideal para eventos gracias a su decoración.

GELATO

CHÁVEZ

Ubicación: Calle Bolivar, entre Colón y René Moreno
Atención: Lunes a Viernes - 07:00 a 22:00

ph: Gelato Chavez

Si sos fan de los helados artesanales, Gelato Chávez es el lugar perfecto para vos. Ubicada frente a la plaza principal del municipio de Portachuelo, esta heladería se caracteriza por la calidad en su atención, además de su creatividad en productos. Aquí encontrarás una variada oferta de sabores de helado, para que elijás a tu gusto. Cuentan con frappés (bebidas escarchadas) de diferentes sabores y helados en diferentes preparaciones, siendo los más famosos los mezclados con frutilla y crema chantilly.

La Feria Nacional de la Miel se destaca como un evento imperdible para los amantes de la apicultura y los productos naturales. Esta feria reúne a productores y entusiastas de todo el país, aquí podrás conocer y disfrutar de una amplia variedad de productos derivados de la miel, como el polen y el propóleo, además cosméticos naturales de buena calidad. La feria no solo promueve el consumo de productos saludables y ecológicos, sino que también impulsa el desarrollo económico de los apicultores locales, consolidando a Portachuelo como un referente en la producción de miel en nuestro país. La Feria es organizada con el apoyo del Centro para la Participación y el Desarrollo Humano Sostenible (CEPAD) y la Fundación Solydes, además de la Diputación de Córdoba y la Mancomunidad Valle del Guadiato, ambas de España.

El Río Güenda, con una impresionante superficie de 44.711 hectáreas y la presencia de al menos cuatro ecosistemas distintos, es un verdadero tesoro de biodiversidad. Esos ecosistemas son pampas del Urubó, que tienen influencia de la flora del Chaco; las pampas con islas de Bosque Chiquitano de Arenales, Bosque Chiquitano en transición amazónica; y pampas húmedas de los ríos Güenda, Palacios y todo ese sistema. Desde el punto de vista geológico, el lugar posee excelentes características para almacenar agua de lluvia en sus acuíferos, lo que significa que puede captarla y guardarla de manera eficiente. Un atractivo natural que te permitirá disfrutar la del paisaje y maravillarte con la belleza de su serenidad.

BUENA VISTA

ph: Página Twitter Buena Vista
ph: Asociación de Turismo y cultura Buena Vista
ph: Hotel Spa Santa María La Antigua
ph: GAD SCZ

BUENA VISTA

Provincia: Ichilo
Fundación: Fundada por el sacerdote José Casas el 26 de febrero de 1723, después de que el padre jesuita Juan de Montenegro estableciera una comunidad en esos territorios.

DATOS GENERALES

Ubicado sobre una colina con vista al "Parque Nacional Amboró", que hace de este municipio una zona de belleza natural tropical.

CLIMA

Húmedo subtropical. Julio es su mes más frío del año y noviembre el más caliente.
Temperatura promedio Su temperatura media es de 24,3 °C; la máxima es de 27,8 °C y la mínima de 14,4 °C. Tiene una precipitación pluvial de 2.563 mm, con una humedad relativa de 80%.

DATOS DEMOGRÁFICOS

Gentilicio Buenavisteño -a
Población (2023)[1]: 21.210 habitantes
Densidad (2023): 8 hab./Km²

DATOS GEOGRÁFICOS

Ubicación: 99 km al noroeste de la ciudad de Santa Cruz de la Sierra

Coordenadas: 17°40'00"S 63°44'00"O

Superficie: 2.707 km²

Altitud : 300 m.s.n.m.

ECONOMÍA

Economía[2]: Las actividades económicas más importantes son agrícola, pecuario y manufactura que de acuerdo al Valor Bruto de Producción (VBP) del municipio representan el 36.12%, 34.77% y 24.15% respectivamente.

Es un municipio productor de gas. La planta de Caranda está activa hace 60 años. La producción de café sobresale en la población, hay dos asociaciones que lo siembran y procesan, posteriormente es exportada a Argentina, Chile y Estados Unidos. Los productores de queso, maduran una variedad del producto hasta diez meses, siendo el queso parmesano, elaborado por la Quesería Suiza, su producto estrella, el mismo que surte a todo el país.

Valor Bruto de Producción (VBP)[3]: 130 MM Bs.

---

[1] Encuesta de Estimación Poblacional de Santa Cruz 2023. Instituto Cruceño de Estadística
[2] Mapa de Complejidades, BDP 2019
[3] Mapa de Complejidades, BDP 2019

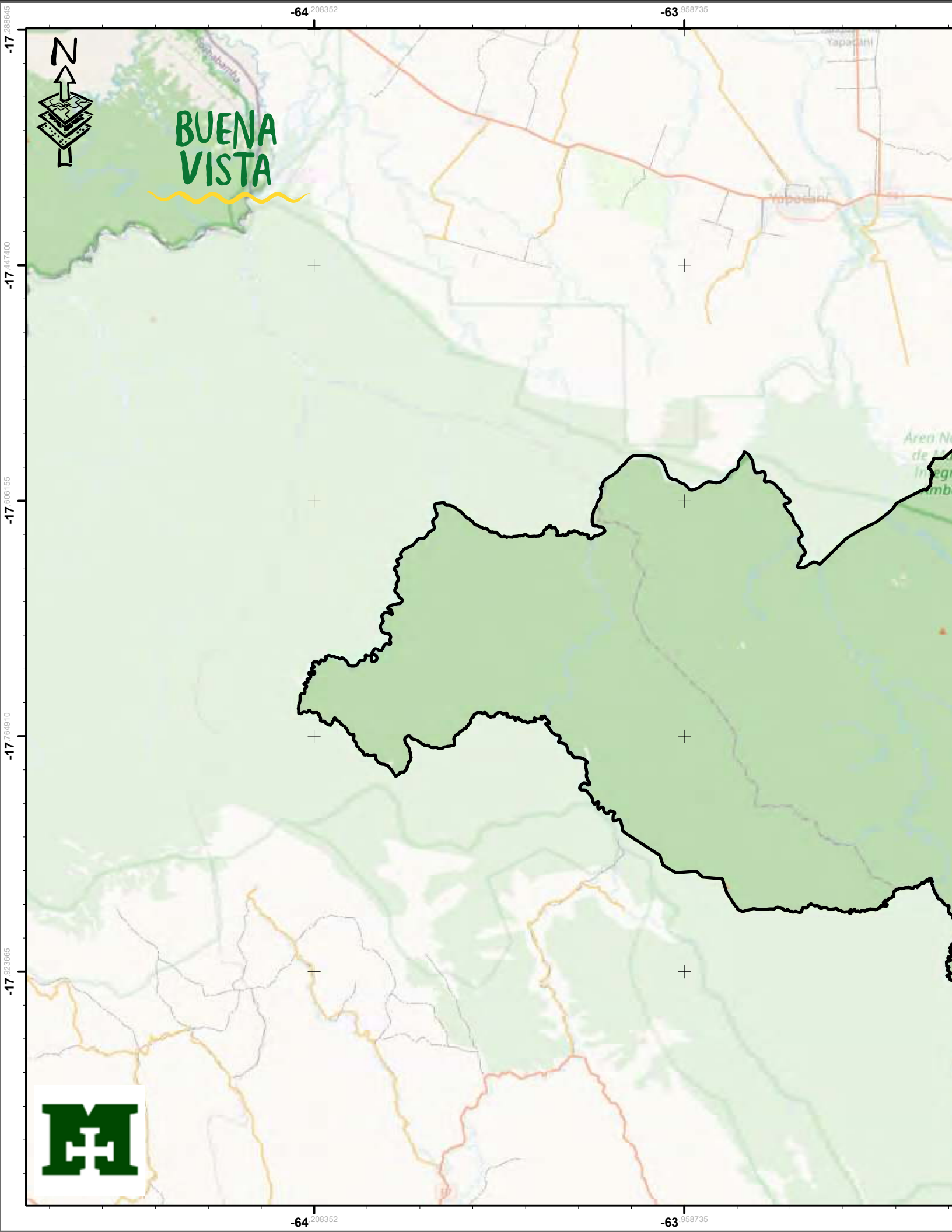
-64.208352
-63.958735
-17.288645
-17.447400
-17.606155
-17.764910
-17.923665
N
BUENA VISTA
Yapacani

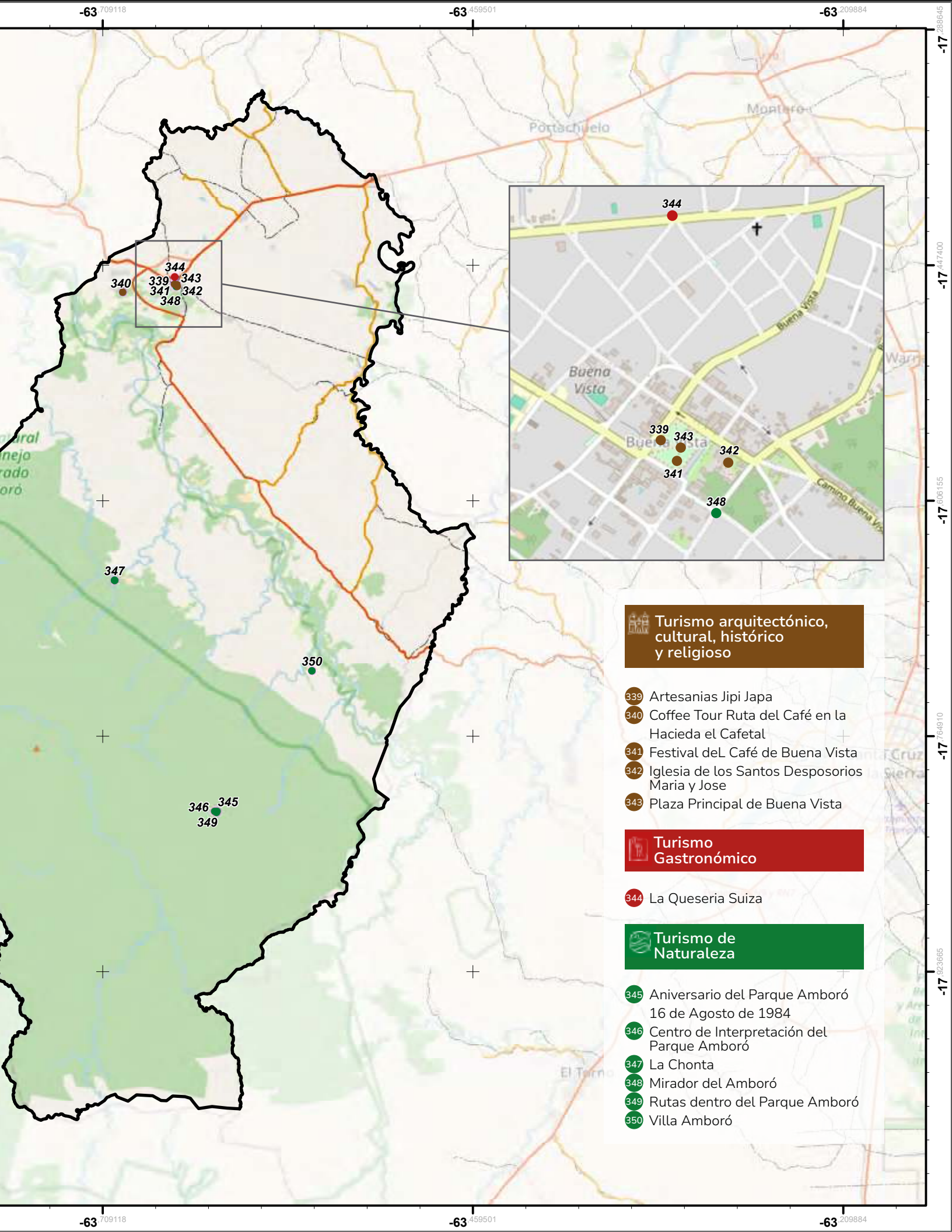
-63.709118
-63.459501
-63.209884
-17.208645
-17.447400
-17.686155
-17.764910
-17.923665
Portachuelo
Montero
344
340
339
343
341
342
348
347
350
346
345
349
Buena Vista
Camino Buena Vista
Turismo arquitectónico, cultural, histórico y religioso
339 Artesanias Jipi Japa
340 Coffee Tour Ruta del Café en la Hacieda el Cafetal
341 Festival deL Café de Buena Vista
342 Iglesia de los Santos Desposorios Maria y Jose
343 Plaza Principal de Buena Vista
Turismo Gastronómico
344 La Queseria Suiza
Turismo de Naturaleza
345 Aniversario del Parque Amboró 16 de Agosto de 1984
346 Centro de Interpretación del Parque Amboró
347 La Chonta
348 Mirador del Amboró
349 Rutas dentro del Parque Amboró
350 Villa Amboró

PLAZA PRINCIPAL

DE BUENA VISTA

Ubicación: Entre calles Celso Sandóval, José Stembch y Mariano Saucedo

ph: Mystic Ilustrator

Rodeada de una exuberante vegetación y considerada un emblema de encuentro para los turistas, la Plaza Principal de Buena Vista se erige como la puerta norte al Parque Nacional Amboró. En 1629, se instauró la Misión Jesuítica de los Santos Desposorios María y José, cuyas figuras son objeto de devoción en el municipio. Esta plaza es aclamada como una de las más pintorescas de la región, enmarcada por una diversidad de árboles, todos ellos representativos de la zona.

Por los alrededores de la plaza, podrás encontrar una amplia gama de servicios turísticos incluyendo restaurantes locales que ofrecen productos elaborados con el delicioso café de la región. Dentro de la plaza hay un recorrido que culmina con una imponente cruz símbolo representativo del municipio de Buenavista. Este espacio es comúnmente utilizado durante Semana Santa para la representación del viacrucis de cristo.

SANTOS DESPOSORIOS MARIA Y JOSÉ

Ubicación: Calle Mariano Saucedo Silva Buena Vista
Atención: Lunes a Domingo - 14:30 a 19:00

ph: Abrrant

La Misión de los Santos Desposorios fue fundada por el Padre Juan de Montenegro y por el Padre José Francisco de Acre (se le atribuye a ambos) en 1694. Sin embargo, la iglesia misional se estableció en 1723, cuando el Padre José Casas fundó la Misión de los Santos Desposorios José y María, lo hizo sobre una meseta que sobresalía y que, para él, ofrecía una buena vista del paisaje natural. Según historiadores, el diseño original de la iglesia fue realizado por el Padre Jesuita Martín Schmid, lo que explicaría las similitudes con la iglesia de San Javier de Chiquitos, donde él residía. La construcción inicial del templo mantenía las características propias de las misiones jesuíticas, con muros de adobe, horcones de madera y techos de teja. Junto al templo, se habría construido una casa misional con sus dependencias y una torre que servía tanto de campanario como de torre de vigilancia. En la década de 1960, debido a la precariedad del edificio, los padres americanos de la Sociedad Santiago Apóstol ordenaron la demolición del templo jesuítico y la casa parroquial, construyendo en su lugar el templo actual. Actualmente, se están realizando investigaciones arqueológicas por parte de la Gobernación de Santa Cruz para conocer más sobre esta misión. Estas investigaciones indican que existen vestigios de los cimientos y del suelo original de la obra arquitectónica proyectada por el misionero Martin Schmid. Dentro de la Iglesia, encontrarás vitrinas que exponen vestigios del legado jesuita en el municipio. Actualmente visitar el templo es un símbolo de fe y esperanza. La iglesia de Buena Vista recibe en sus paredes a múltiples parejas que buscan unirse en sagrada unión y ser bendecidas por María y José.

ph: Abrrant

La Quesería Suiza emerge como uno de los pilares fundamentales en la industria quesera de nuestro país. Con dos décadas de experiencia en el sector, esta emblemática empresa ha consolidado su posición como uno de los principales productores de queso, ofreciendo una amplia variedad de 13 tipos diferentes, que van desde los suaves y frescos hasta los denominados curados. La Quesería tiene once variedades con leche de vaca y dos con leche de cabra. Más allá de simplemente fabricar quesos, la empresa ofrece una experiencia completa a sus clientes a través de su famoso "tour de queso".

Este recorrido no solo te permitirá conocer el proceso de elaboración del queso, sino también degustar una amplia selección de sus productos. Además de su línea de productos masivos, Quesería Suiza también ofrece una línea gourmet, especialmente diseñada para satisfacer las necesidades de restaurantes y pizzerías de alta cocina.

Esta práctica se remonta al siglo XVIII, con la creación talleres promovidos por los jesuitas, quienes tuvieron la misión de evangelizar a los indígenas del oriente boliviano. La planta carludovica palmata, conocida como Jipi Japa en Santa Cruz, fue utilizada ancestralmente por artesanos locales para confeccionar sombreros y otros objetos artesanales.

Esta actividad, transmitida de generación en generación, es una importante fuente de ingresos para las familias, especialmente para las mujeres, aunque los hombres también participan en la recolección y tejido. Originalmente esta era una labor masculina; sin embargo, el tejido se convirtió en una tarea femenina debido a cambios en la demanda de moda. En Buenavista, asociaciones como ARTE CAMPO y El Tojo agrupan a mujeres emprendedoras dedicadas a la elaboración de artesanías en Jipi Japa y otros materiales como madera y croché.

RUTA DEL CAFÉ

HACIENDA EL CAFETAL

Ubicación: Sobre Celso Sandoval con destino al Parque Nacional Amboró, comunidad Candelaria
Atención: Todos los días de 09:00 a 16:00 Hrs.

ph: Twitter Buena Vista

La Ruta del Café en la Hacienda "El Cafetal" es una ruta en la que participan grupos pequeños, conducidos por un guía, quien explica exactamente el proceso desde la recolección de los frutos hasta la germinación de las semillas. La temporada ideal para disfrutar de este tour es entre marzo y junio, coincidiendo con la cosecha, en la que participan campesinos de diversas comunidades, utilizando métodos tradicionales y sistemas comunitarios para la extracción de las semillas.

ph: Twitter Buena Vista

ph: Twitter Buena Vista

ph: Hacienda El Cafetal

Durante el recorrido, podrás apreciar los diferentes métodos de extracción del café utilizados a lo largo del tiempo, desde técnicas familiares hasta ingeniosos sistemas comunitarios. Al final del trayecto, te ofrecerán una degustación de las distintas variedades de café y sus formas de preparación, brindándonte la oportunidad de ampliar tu conocimiento y disfrutar de esta bebida de una manera más informada. Pasear por una extensión de 100 hectáreas de cafetal, sentir la mezcla de aromas despedidos por una tupida vegetación es algo que no podés dejar pasar si visitás el municipio de Buenavista.

ph: Buena Vistabol

HOTEL SPA

SANTA MARIA LA ANTIGUA

Ubicación: Km 103, a 5 kilómetros del la plaza Buena Vista
Atención: Siempre abierto

ph: Hotel Spa Santa María La Antigua

Viví una experiencia única y reparadora en el Hotel Santa María La Antigua, un refugio en plena naturaleza, rodeado de exuberante vegetación, aves exóticas y más de 2.000 hectáreas de parques nacionales. Este hermoso entorno ofrece vistas espectaculares y una atención cálida proporcionada por la gente del lugar, que hace de la estancia una experiencia memorable. Entre las actividades más destacadas, podrás montar a caballo, una excelente opción para disfrutar en familia. También cuentan con una pequeña reserva ecológica, donde podrás observar y alimentar a yacarés (caimanes) y sus crías en un ambiente controlado. Además, el hotel tiene una lechería, donde cada mañana se realiza el ordeño de las vacas lecheras, y los huéspedes pueden probar la ambrosía, una bebida hecha de leche recién ordeñada y licor. Los niños también tienen la oportunidad de interactuar con los terneros en el kínder de la lechería.

ph: Hotel Spa Santa María La Antigua

ph: Hotel Spa Santa María La Antigua

El hotel cuenta con diversas instalaciones para el disfrute de sus visitantes, como una piscina al aire libre, una capilla artesanal, canchas de tenis, fútbol, voleibol, mini golf y parques infantiles. Para los amantes de la naturaleza, ofrece senderismo guiado, una experiencia relajante y única en contacto con el entorno. Los alrededores del hotel son ideales para realizar guiados en vehículos 4x4, permitiéndote visualizar animales sorprendentes. Además, por la noche, se enciende una fogata donde los huéspedes pueden disfrutar de malvaviscos, creando un ambiente acogedor.

ph: Hotel Spa Santa María La Antigua

ph: Hotel Spa Santa María La Antigua

El restaurante “El Rocío” ofrece lo mejor de la gastronomía cruceña y boliviana, con platos preparados con productos frescos de la misma hacienda. Para una experiencia de bienestar completa, el hotel cuenta con un spa que ofrece masajes relajantes, tratamientos faciales y baños de vapor, lo que lo convierte en el destino perfecto para quienes buscan relajarse y escapar del bullicio de la ciudad.El Hotel Santa María La Antigua es el lugar ideal para disfrutar de un entorno natural incomparable, combinado con una atención excepcional y actividades que te conectarán con la naturaleza. ¡Una experiencia turística que no te podés perder!

PARQUE AMBORÓ

Ubicación: Km 100, desde la ciudad de Santa Cruz de la Sierra

ph: Nathan K.

RUTAS Y VISTAS

Ubicado a 100 kilómetros de la capital cruceña, el Parque Nacional Amboró, posee una enorme variedad de rutas que podés recorrer. A continuación, te mencionamos las más conocidas: La primera se encuentra en la región de Mataracú. Aquí observarás un bosque húmedo tropical, poblado de diversas especies forestales, animales como el melero o el perezoso y caídas de agua con pozos de aguas cristalinas. El segundo lugar es el campamento Saguayo, que cuenta con una elevada diversidad paisajística. Observarás la topografía montañosa de la región de los valles, los ríos tormentosos y las caídas de agua, además de diferentes tipos de aves. Como tercer lugar, tenés el albergue ecoturístico Laguna Verde, que ofrece hospedaje en camping y cabañas, así como servicios de guiado, alimentación y transporte en vehículos 4x4. En el camino a la laguna, encontrarás en los senderos árboles exóticos, como el Bibosí de 8 metros, además de huellas de múltiples animales silvestres que, de vez en cuando, se ven transitar. La laguna es de color agua verdoso y alberga una variedad de peces, además de ser el bebedero del jochi pintau. Se ofrecen los servicios de ciclismo, caminatas, paseos a caballo, escalada de rocas y farallones, natación, canotaje y de la interpretación de flora y fauna, con la posibilidad de observar aves y realizar investigaciones científicas, ya sea biológicas o arqueológicas. Sin lugar a duda, el Parque Natural Amboró es un territorio de gran envergadura, siendo un tesoro del departamento de Santa Cruz y de nuestro país.

MIRADOR DEL AMBORÓ

Ubicación: Sobre calle Jose Stembach esq. Los Artistas.

El Mirador del Amboró es un fascinante parque infantil y de esparcimiento que cautiva a visitantes de todas las edades.Su principal encanto reside en la espectacular vista panorámica que ofrece de los alrededores del pueblo y de las majestuosas serranías del Parque Amboró, brindando un escenario natural inigualable para que disfrutés en familia o con amigos. Para los más pequeños, el parque infantil ofrece una amplia gama de juegos y actividades recreativas, garantizando horas de diversión y entretenimiento en un ambiente seguro y acogedor. Los niños pueden explorar áreas de juegos equipadas con columpios y estructuras de escalada, mientras que los adultos pueden relajarse en las áreas de descanso, que cuentan con mesas de madera bastante pintorescas, disfrutando de la tranquilidad del entorno natural y recargando energías para continuar explorando las maravillas de Buena Vista y sus alrededores.

ANIVERSARIO DEL AMBORÓ

Fecha Aniversario : 16 de agosto

Los inicios del Parque Amboró datan desde los años setentas, cuando solo una sección del Cerro Amboró fue declarada reserva natural. Sin embargo, en 1984, esta Área Protegida, fue declarada Parque Nacional y Área Natural de Manejo Integrado Amboró, con una superficie de 673,600ha, de las cuales 442,500 ha corresponden a la categoría Parque Natural y 195,100 ha a la categoría de ANMI. El Parque Nacional Amboró es una de las reservas con mayor biodiversidad a nivel mundial; sin lugar a dudas, un destino que no te podés perder si visitas el municipio. Es por eso que desde el 16 de agosto, fecha aniversario del Parque, múltiples operadores turísticos, grupos privados, instituciones estatales y personas aventureras ingresan en la zona ANMI del Parque para poder disfrutar de diferentes tipos de rutas, buscando observar y honrar el aporte ecosistémico que este brinda al mundo entero. Por parte del municipio de Buena Vista, el festejo comienza el 16 de agosto, con el acto conmemorativo del Centro de interpretación del Parque Amboró. En los días posteriores, se realiza una caminata que tiene una duración de 2 días, con un aporte voluntario que ronda entre los Bs 20, determinado por la fecha que sea fin de semana. Este evento busca concientizar a la población local sobre el apoyo a la conservación y el cuidado de los recursos naturales. Los organizadores son la dirección del Parque, el municipio de Buena Vista y el Grupo Ecologista Amboró (GEA). En los demás municipios como San Carlos, Comarapa, Pampa grande y Mairana, se tienen planificadas actividades como caravanas y competencias de ciclismo, así como concursos de poemas y pinturas.

CENTRO DE INTERPRETACIÓN

Ubicación: Dentro del municipio de Buena Vista

El Centro de Interpretación Amboró es un espacio crucial para el aprendizaje y la conciencia ambiental, tanto para locales como para visitantes. Ofrece información detallada sobre la biodiversidad, la geografía y la cultura del Parque Nacional y Área Natural de Manejo Integrado Amboró, destacando la importancia de su conservación. Es el primer centro de interpretación de un área protegida en Bolivia. Este Centro, ubicado en el municipio, proporciona oportunidades educativas para entender y apreciar la riqueza natural de la región. El Centro cuenta con instalaciones y equipamiento didáctico, incluyendo salas audiovisuales y de interpre-

tación. Aquí, podrás disfrutar de paneles informativos, maquetas y exhibiciones interactivas que muestran la biodiversidad y los procesos ecológicos del Amboró. Además, ofrece actividades lúdicas como juegos temáticos y senderos interpretativos que te permitirán conocer la fauna y la flora del parque. Este proyecto fue resultado de la colaboración entre el Servicio Nacional de Áreas Protegidas y el Gobierno Municipal de Buena Vista, con el apoyo de organizaciones como WWF y COBIMI, así como la cooperación de USAID, la Cooperación Técnica Belga y la Prefectura del Departamento de Santa Cruz (actual Gobernación de Santa Cruz). Su objetivo es promover el desarrollo sostenible del Amboró y fomentar el cuidado de su biodiversidad mediante la educación y el ecoturismo.

LA CHONTA

Ubicación: Km 110, pasando el río Surutú

En el sector norte del Parque Nacional Amboró, existe un campamento de guardaparques y complejo turístico conocido como La Chonta. Caracterizado por su alta diversidad en flora y fauna, ofrece senderos de interpretación. Un ejemplo es el circuito Las Palmeras, donde podrás ver árboles de más de 100 años de antiguedad, plantas medicinales, helechos, orquídeas y patujusales. Además, en medio camino encontrarás un mirador para deleitarte con los alrededores. Si te gusta nadar, podrás disfrutar de pozas naturales desplazándote por las aguas del río, cerca de la Chonta. Este complejo te ofrece cabañas de hospedaje con alimentación incluida y con hamacas.

VILLA AMBORÓ

Ubicación: Km 150, pasando el río Surutú

Villa Amboró es un refugio ecoturístico ideal para que conozcas la gran riqueza y diversidad de la naturaleza. Además, ofrece muchas rutas que podrás realizar. Para comenzar, podrás hacer la ruta Maravillas, que tiene una distancia de 800 metros y es apta para todo tipo de turistas. Aquí observarás distintas especies forestales, huellas de mamíferos y una gran cantidad de mariposas. Como segundo sendero está la ruta de los Tatúicitos, con una distancia de 1.400 metros, donde podrás identificar más de 800 especies de árboles, acompañadas de una gran cantidad de orquídeas. En tercer lugar, está la ruta al Mirador del Amboró, con una distancia de 3.500 metros. Este sendero está recomendado solamente para personas que están acostumbradas a realizar largas caminatas, de entre 3 a 4 horas. Por último, tenemos el sendero de Macuñucú y los cajones del Amboró. Aquí apreciarás la biodiversidad de toda la zona durante el recorrido, llegando hasta la Cueva de los Guácharos, donde podrás observar aves nocturnas en peligro de extinción.

RÍO SURUTÚ

Ubicación: Km 100, desde la capital de Santa Cruz

El río Surutú nace de la confluencia de las quebradas Blanca y Surutú, que desembocan en el Parque Nacional Amboró. Con una longitud de 89 kilómetros, ofrece numerosas playas de arenas blancas que invitan a disfrutar de un chapuzón en sus tranquilas y cristalinas aguas, ideales para la familia y un día de campo. Existen varios puntos desde donde podrás acceder al río: el primero es Puerto Villa Aquiles, a 3 kilómetros; el segundo es Puerto El Cairo, accesible por la comunidad de Candelaria, a 5 kilómetros. También están Palillos, a 12 kilómetros, y el sendero de los Cafetales, a 5.5 kilómetros. Todas estas distancias desde el municipio de Buenavista.

ph: GAD SCZ

ph: GAD SCZ

ph: Fundación Natura

ph: GAD SCZ

ph: GAD SCZ

ph: GAD SCZ

ph: GAD SCZ

PLATOS BANDERA

TURISMO GASTRONÓMICO

Santa Cruz de la Sierra, Cotoca, Porongo, La Guardia, El Torno, Warnes, Okinawa I, Pailón, Colpa Bélgica, Montero, Portachuelo y Buena Vista

ph: GAD SCZ

Conocido también como Majau o Majadito, su nombre proviene del verbo "majar" que significa moler. Se encuentra en dos presentaciones, el batido y el tostado, que generan un debate de gustos entre sus comensales. Es un arroz mesclado con carne, charque o pollo, sazonado con especias como urucú que le otorga su característico color. Se acompaña de huevo frito, plátano frito y a veces yuca y/o ensalada. Se lo encuentra en prácticamente cualquier local de comidas en toda la Región Metropolitana desde restaurantes, mercados hasta pensiones.

ph: GAD SCZ

Una de las referencias emblemáticas de la gastronomía boliviana es sin duda la infaltable "Salteña"; una empanada jugosa rellenada con jigote de carne, pollo, huevo duro, papa y especias, cocidas al horno; existiendo, por lo tanto, variedades de acuerdo a su relleno, pero siempre manteniendo su estilo y masa particular y adoptando en su sabor, rasgos peculiares de acuerdo a las manos que la preparan. Se caracteriza por ser muy asequible, llegando a ser un aperitivo de media mañana para todos los bolivianos. Se la suele acompañar con gaseosas o jugos de frutas. En la Región Metropolitana de Santa Cruz, la salteña es vendida en diferentes locales denominadas coloquialmente como "salteñerías", las cuales tienen una larga trayectoria en la oferta de este particular platillo. Se puede encontrar también en mercados, supermercados y otros comercios a lo largo de toda la Región Metropolitana.

SOPA DE MANI

ph: GAD SCZ

El conocido plato boliviano tiene una importante presencia en todos los municipios de la Región metropolitana. Es una Sopa que en su preparación contiene maní y carnes según gusto. Se acompaña con papas fritas y/o perejil. Se lo consume en restaurantes, mercados, pensiones y eventos de comida al aire libre.

SÁBALO Y PACÚ

ph: GAD SCZ

La oferta de pescado a la parrilla tiene como protagonistas 2 especies: El Pacú y el Sábalo. Estos se preparan al carbón adquiriendo el sabor ahumado y sazonados con limón. Se puede encontrar en Mercados y restaurantes de toda la Región Metropolitana, especialmente en municipios como Cotoca (Puerto Pailas), Pailon, Buena Vista y Santa Cruz de la Sierra

KJARAS

ph: GAD SCZ

Kjaras, también denominado K'jaras o qaras, es un plato típico procedente de la provincia Vallegrande. El nombre del plato proviene del vocablo "qara", que en quechua significa "piel", refiriéndose al cuero del chancho. El plato se compone de porciones de chuleta de cerdo, cuero de cerdo, chorizo parrillero acompañado de papa, mote y queso. Se suele servir con la infaltable llajua o ají (salsa picante). Su preparación a la parrilla le da un sabor ahumado que le brinda un sabor diferente a los comensales. Este plato típico se ha convertido en una tradición en la Región Metropolitana de Santa Cruz, consumido principalmente en los días a los que se ha denominado los "Viernes de Kjaras" aunque también se pueden encontrar los días sábados u otro día de la semana. Puede ser consumido en locales que además acompañan su consumo con música al vivo y bebidas como cerveza, pero sobre todo en hogares que acostumbran comercializar este plato en las aceras de sus viviendas en los barrios de cualquier municipio de la Región Metropolitana.

CHICHARRÓN

ph: GAD SCZ

Plato frito característico de los municipios con alta actividad de pesca y cría, es preparado en base a una especie de pez característico de la región. Se sirve normalmente acompañado de yuca frita, arroz, choclo y ensalada; se suele sazonar con limón. Se lo puede encontrar en toda la Región Metropolitana, especialmente en municipios como Cotoca (Puerto Pailas), Pailon, Buena Vista y Santa Cruz de la Sierra. Se sirve en mercados y restaurantes.

LOCRO

ph: GAD SCZ

Es una sopa de pollo con arroz y sazonado con especias, verduras y otros ingredientes que varían según gusto. Se suele acompañar de yuca hervida. Este plato se suele consumir como alternativa a un almuerzo, a una cena e inclusive a un desayuno. Conocido como un plato popular, se lo sirve a lo largo y ancho de toda la Región Metropolitana en restaurantes, pensiones y mercados.

ASADITO VALLEGRANDINO

ph: GAD SCZ

Un plato tradicional herencia de Vallegrande, es un preparado de Cerdo sazonado con urucú (que le da su color característico) y servido con Mote (grano de maíz) y papa. Se lo suele consumir durante la mañana y también se ofrece combinado con escabeche, otro preparado típico en base a chancho y vinagre. Se lo encuentra especialmente en el Municipio de La Guardia, no obstante también se lo comercializa y consume en toda la Región Metropolitana. Se acostumbra a consumir en Mercados, locales al paso y restaurantes.

CHURRASCO

ph: Las Ranas Porongo

ph: GAD SCZ

El churrasco, como se conoce en Santa Cruz a la carne asada a la parrilla, es mucho más que un plato típico, es un rito cultural y lugar de encuentro. Este exquisito plato fomentado por el acceso a excepcional carne producida en la Región, tiene un lugar especial en el corazón de los cruceños y en sus reuniones familiares, sociales y culturales.

Preparar un churrasco es casi un ritual. Se hace a la parrilla, donde la carne se cocina lentamente sobre carbón, logrando ese sabor ahumado que es inconfundible. Los cortes de carne más populares en Santa Cruz son la Punta de "S", el bife de chorizo, la picaña y el asado de tira, aunque también se suelen incluir chorizos y morcillas en la parrilla. Las carnes son sazonadas con sal gruesa únicamente.

El acompañamiento es tan importante como la carne. No puede faltar la yuca frita, ensaladas frescas como la de tomate y cebolla, y un buen ají para los amantes del picante. En algunos casos, el arroz con queso, otro clásico cruceño, complementa el plato. El churrasco fomenta las relaciones humanas; vos sabés que, al sentarte a compartir esta comida, estás participando en una tradición que une generaciones. Es un momento para desconectarse de las preocupaciones y conectarse con los demás. Los anfitriones, orgullosos de su destreza en la parrilla, suelen poner el corazón en cada asado, y los comensales retribuyen con elogios y gratitud. Más allá del sabor, el churrasco es un reflejo del espíritu hospitalario y festivo de los cruceños. Es una excusa perfecta para estrechar lazos, celebrar ocasiones especiales o, simplemente, disfrutar de la buena compañía. Así, este plato no solo llena el estómago, sino también el alma.

Si alguna vez visitás Santa Cruz, no podés dejar de probar un churrasco. Lo encontrás en toda la Región Metropolitana, en todos los municipios, sin excepción.

Una bebida refrescante elaborada con durazno deshidratado, canela y azúcar. Es un excelente aliado para saciar la sed y combatir el calor. Se lo encuentra en todos los Municipios de Santa Cruz Metrópoli, tanto en locales al paso, restaurantes, tiendas y mercados.

Es una bebida refrescante hecha a base de harina, canela, clavo de olor y azúcar. Se puede tomar sola así como se suele usar de acompañamiento para un almuerzo o cena. Se encuentra en toda la Región Metropolitana en tiendas, mercados, restaurantes y negocios. También es frecuente consumirlo en carritos ambulantes adaptados especialmente para su comercialización.

Una bebida refrescante elaborada a base de maíz, harina, canela y que se sirve con el grano cocido de maíz el cual se consume simultáneamente a la bebida. Se toma frio y es una excelente alternativa para combatir el calor. Se lo encuentra en toda la Región Metropolitana en tiendas, mercados, restaurantes y negocios. También es frecuente consumirlo en carritos ambulantes adaptados especialmente para su comercialización.

La paleta helada conocida como “Picole” es un postre especialmente consumido en el municipio de Montero gracias a los tradicionales helados “Pato Roca”. Se presenta en diversos sabores y se puede encontrar también de otras marcas, tanto en presentaciones más industrializadas, como en las ventas de barrio bajo el nombre de los conocidos “heladitos”.

PAN DE ARROZ

ph: GAD SCZ

Es un horneado preparado en base a harina de arroz y yuca molida que en el caso de la Empanada de arroz lleva además queso en su interior. Ese se sirve envuelto en una hoja de platano. Se acostumbra consumirlo en el café de la siesta junto a las demás masitas. Si bien se lo encuentra por toda la Región Metropolitana, el Municipio de Warnes ha sido declarado como la capital Departamental del Pan de Arroz según Ley Departamental N° 272. También es muy tradicional en los municipios de Portachuelo y Santa Cruz de la Sierra. Se lo puede consumir en cafeterías, mercados, restaurantes, panaderías y tiendas de barrio.

ABISCOCHADOS

ph: GAD SCZ

Se denomina así a una serie de panadería crujiente preparada en base a recetas originales como el cuñape o la rosca de maíz, cambiando en su elaboración los tiempos de cocción para alcanzar un alimento deshidratado que le da mayor tiempo de duración a la comida. Es un Snack que también suele consumirse a la hora del cafecito de la tarde. Se encuentra en mercados, supermercados y tiendas de toda la Región Metropolitana, no obstante son especialmente característicos en los municipios de Portachuelo y Cotoca.

SONSO

ph: GAD SCZ

Una masita típica preparada en base a yuca hervida, molida en tacú, mesclado con queso y leche, para luego ser horneado. Es un frecuente acompañamiento del cafecito de la tarde. Se encuentra en dos presentaciones, tanto en una bandeja como en un palo como una banderilla. Si bien se los encuentra en toda la Región Metropolitana, son principalmente característicos en los municipios de Cotoca, Porongo y Santa Cruz de la Sierra donde incluso se puede encontrar preparado a leña.

MASACO

ph: GAD SCZ

Un alimento preparado con yuca hervida o con plátano (maduro o verde) que se combina con queso o charque y se sirve en molde o suelto. Este platillo suele acompañar los cafecitos y desayunos de los cruceños. Se puede encontrar en cafeterías, restaurantes y mercados de toda la Región Metropolitana por igual.

Uno de los horneados más característicos de Santa Cruz, preparado con almidón de yuca, queso, huevo y otros ingredientes que se hornean hasta conseguir un pan de intenso sabor. Es el acompañamiento más frecuente del cafecito de la tarde y se puede encontrar en cualquier municipio de Santa Cruz Metrópoli en cafeterías, mercados, supermercados, panaderías, tiendas de barrio y hasta de manera ambulante.

Un platillo de Choclo (Maiz) con queso que se prepara al interior de hojas de maíz. Es un infaltable a la hora de cualquier cafecito. Se consume en dos preparaciones: Al horno y a la olla, haciendo referencia a si es horneado o hervido.

Elaborada en base a la miel de caña, es un dulce que se acostumbra presentar en un recipiente hecho de barro a mano. Se encuentra en diversos lugares de toda la Región Metropolitana, pero sin duda alguna, Cotoca es el municipio de referencia para la venta del mismo, incluso declarándola mediante Ley Departamental N° 175 como “La Capital de la Jalea”.

Un dulce elaborado de miel de caña que se mescla con maní o leche hasta su solidificación como una tablilla, de ahí su nombre. Se comercializa a lo largo de toda la Región Metropolitana, pero especialmente en el municipio de Cotoca. Se puede encontrar en casi cualquier venta, mercados y algunos restaurantes.

También conocido como Maja´ Blaco, es un postre preparado en base harina de arroz, azúcar, leche y canela. Se sirve característicamente en el café como aderezo al pan, acompañado de queso o para un gusto en cualquier momento. Si bien se los encuentra en toda la Región Metropolitana, es principalmente característico de los municipios de Cotoca y Portachuelo donde incluso se lo puede encontrar preparado a la leña.

"CAFÉ DE LA SIESTA"

ph I y II : Cafetería Buen Día
ph III-VI: Fridolin

ph: GAD SCZ

El "Café de la Siesta" es una tradición cruceña que se remonta a la época colonial en Santa Cruz. Esta costumbre consiste en tomarse una pausa durante la tarde para disfrutar de una taza de café acompañado de horneados típicos como el cuñapé, pan de arroz, sonso de yuca, empanada de queso, de pollo, rosquitas de maíz y demás oferta derivada principalmente de los insumos disponibles en la región como la yuca, el queso y el plátano.

Según la historia, el "Café de la Siesta" nació en las haciendas de la región, donde los trabajadores se reunían después del almuerzo para descansar y compartir un café. Con el paso del tiempo, esta práctica se extendió a toda la población y se convirtió en una parte importante de la cultura cruceña, en una especie de ritual, que al buen estilo de los cruceños de antaño, permanece en el tiempo arraigada en todas las generaciones.

Actualmente, la experiencia del "Café de la Siesta" es la excusa perfecta para tener una "tertulia" (charla) con los familiares, amigos o la pareja, convirtiéndose en un momento de encuentro social, para compartir anécdotas o simplemente para disfrutar un momento de tranquilidad en medio de la rutina diaria. En este sentido, han surgido diferentes sitios de oferta como cafeterías y salones de té, ubicados en toda la región metropolitana de Santa Cruz, destacando varios de ellos por combinar las tradiciones con otras experiencias modernas de cafeterías internacionales, como sumar a su equipo a profesionales de preparación de café, como son los baristas y adecuar ambientes diversos, variados y temáticos, resaltando, algunas cafeterías por ejemplo, el contacto con la naturaleza, la historia y otros minimalistas o más futuristas, cada uno manteniendo su originalidad o la tradición de los cafés cruceños.

En definitiva, el Café de la Siesta es una tradición que refleja la hospitalidad y calidez de la gente cruceña, y que sin duda merece ser experimentada por aquellos que visitan la región. Una taza de café, un lugar acogedor y buena compañía son los ingredientes perfectos para disfrutar de esta hermosa costumbre que forma parte del alma de Santa Cruz.